Bulletin d'estimation du risque d'avalanche
(valable en dehors des pistes balisées et ouvertes)

MASSIF : Pays-Basque

Rédigé le samedi 14 février 2026 à 16h

Estimation des risques pour le : DIMANCHE 15 FÉVRIER

NEIGE FRAICHE VENTEE AVANT REDOUX ET PLUIES.

3

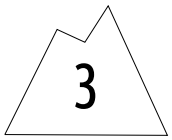

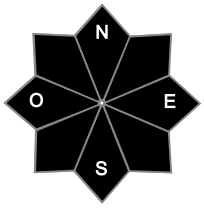

Indice de risque marqué.

Départs spontanés : nombreux, en neige fraîche en journée, en neige vite humidifiée ensuite.

Déclenchements provoqués : plaques instables.

Indices de risque : 5 très fort - 4 fort - 3 marqué - 2 limité - 1 faible -- En noir : les pentes les plus dangereuses

Stabilité du manteau neigeux

Situation avalancheuse typique : neige fraîche neige humide

Déclenchements provoqués : manteau neigeux instable formé d'**empilement de plaques à vent** de résistances très variables suivant les vents tourillonnant et irréguliers des derniers jours. Les plaques sont **nombreuses en tous versants**, assez **faciles à déclencher par un seul randonneur ou skieur à l'abri des vents d'ouest à nord** des derniers jours, **plus dures dans les secteurs directement exposés au vent**.
En journée de dimanche, **cassures linéaires importantes** dans les **pentes est à sud et sud-ouest**, avec des accumulations souvent de 50 à 80 cm, engendrant des **avalanches de taille 3, très localement taille 4 en est à sud**. Dans les **autres secteurs**, un skieur ou randonneur peut déclencher avec **un peu plus de sollicitation une avalanche de taille 2 à localement 3**.
Humidification rapide en fin de journée, se poursuivant en soirée et nuit suivante, départs faciles de neige lourde sous les skis.

Départs spontanés : en **neige sèche en journée,** dans les **pentes raides** avec les volumes de neige récente mobilisable, et par **surcharge due au transport par le vent**, déclenchant les **plaques formées et en formation décrites ci-dessus.** Quelques **avalanches de taille 2 en secteurs ouest à nord à taille 3 dans tous les autres secteurs**.
En **fin de journée**, temps plus doux, humide, avec des pluies jusqu'au plus haut du massif, intenses et se poursuivant en soirée et nuit suivante, sont à l'origine d'un **nombre d'avalanches de plus en plus important et de taille croissante** : on peut s'attendre à des départs d'avalanches de **grande taille** (3), **localement très grande** (taille 4), **susceptibles d'atteindre routes et infrastructures,** par déclenchement d'avalanches de fond notamment.

Qualité de la neige

Enneigement : bon enneigement, mais avec toujours crêtes, cols et sommets en expositions ouest souvent pelés, ou en glace. Saupoudrage en dessous 800/900m d'altitude, manteau neigeux débutant plutôt vers 1000m, s'épaississant notablement à partir de 1200 à 1300m, surtout en zones déventées.
Limites skiables : manteau neigeux skiable à partir de 1000 à 1100m dimanche matin, sur une sous-couche portante à 1200/1300m en nord, 1500/1600m en sud.
État de la neige : neige sèche dimanche matin, plus ou moins travaillée par le vent suivant les versants, s'humidifiant lentement en journée jusque 1600/1700m. L'humidification s'accélère en fin d'après-midi dans les nuages et avec l'arrivée des pluies pour la fin de journée et la nuit suivante.

Aperçu météo pour le dimanche 15 février

	nuit	matin	après-midi	soir

Chutes de neige faibles plus ou moins ventée avant redoux marqué et pluies.

Pluie-Neige	900 m	1 400 m	1 700 m	2 000 m
Iso 0 °C	1 200 m	1 700 m	2 000 m	2 300 m
Vent 1000 m	↙ 20 km/h	↘ 15 km/h	→ 20 km/h	↗ 25 km/h
Vent 2000 m	↘ 65 km/h	↘ 35 km/h	→ 40 km/h	→ 50 km/h

Épaisseur de neige hors-piste

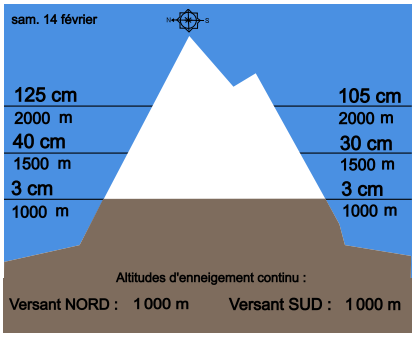

Précipitations à 1800 m

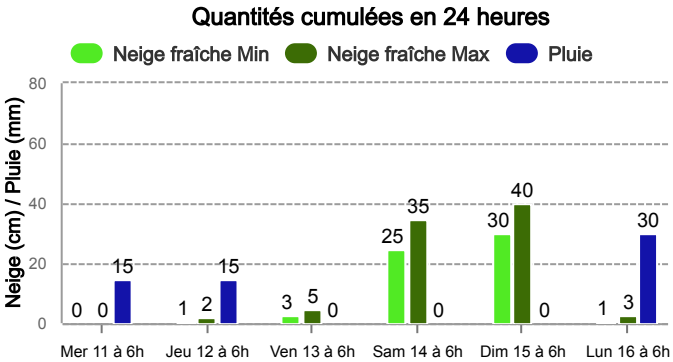

Tendance du lundi 16 février

3

Indice de risque marqué

Temps perturbé avec des pluies, maintien d'un risque marqué (3).

Pour consulter la vigilance en cours, veuillez vous rendre sur le site https://vigilance.meteofrance.fr/fr

Météo-France - 73 avenue de Paris, 94165 Saint-Mandé cedex - Contact : contact@meteo.fr

Rédigé par Météo-France avec la contribution des observateurs du réseau nivo-météorologiques. Partenariat : ANMSM (Maires de Stations de Montagne), DSF (Domaines Skiables de France), ADSP (Directeurs de Pistes et de la Sécurité des Stations de Sports d'Hiver) et autres acteurs de la montagne.

Bulletin neige & avalanches par téléphone au **0 892 68 10 20** Service 0,35 € / min + prix appel

RÉPUBLIQUE FRANÇAISE
Liberté Égalité Fraternité

METEO FRANCE
À VOS CÔTÉS, DANS UN CLIMAT QUI CHANGE

Bulletin d'estimation du risque d'avalanche

(valable en dehors des pistes balisées et ouvertes)

MASSIF : Pays-Basque

Rédigé le samedi 14 février 2026 à 16h

Conditions nivo-météo des 7 derniers jours

	dim. 08/02				lun. 09/02				mar. 10/02				mer. 11/02				jeu. 12/02				ven. 13/02				sam. 14/02			
	03h	09h	15h	21h	03h	09h	15h	21h	03h	09h	15h	21h	03h	09h	15h	21h	03h	09h	15h	21h	03h	09h	15h	21h	03h	09h	15h	21h
Météo																												
Vent (km/h)	90	40	45	30	60	50	50	60	70	90	90	80	70	80	100	120	120	110	80	75	110	110	85	90	100	75	80	75
à 2000m	↑	↘	↘	↑	↗	↗	↗	↗	↗	↗	↗	↗	↗	↗	↗	↗	↗	→	↘	↗	↑	↑	→	↘	↓	↓	↘	↓
Vent (km/h)	60	25	35	20	30	40	30	40	50	60	65	50	40	50	70	80	80	70	40	35	50	65	55	55	60	40	45	35
à 1000m	↑	↗	→	↑	↑	↑	↑	↑	↗	↗	↗	→	→	↑	↑	↗	↗	→	↘	↗	↗	↑	↗	↘	↓	↓	↓	↓

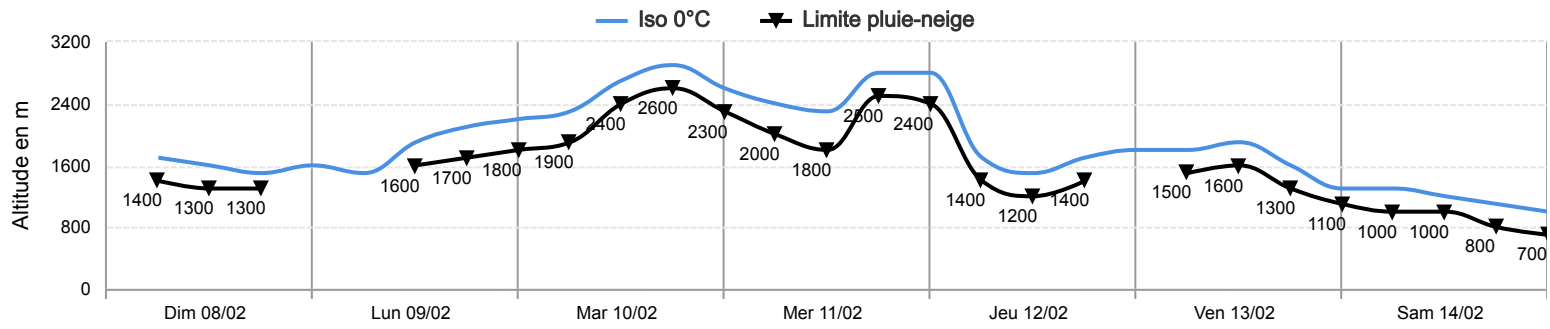

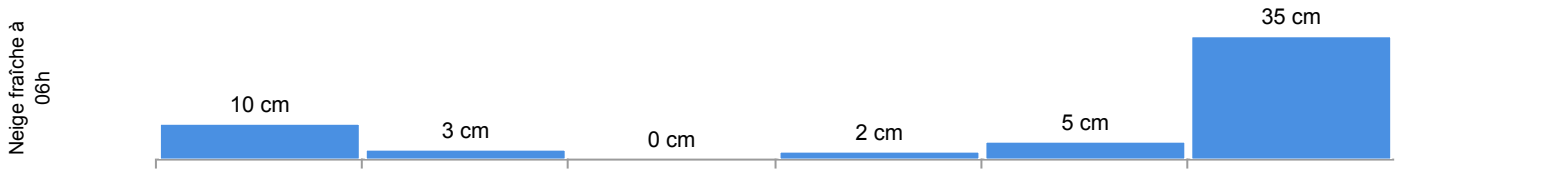

Risque d'avalanche	dim. 08/02	lun. 09/02	mar. 10/02	mer. 11/02	jeu. 12/02	ven. 13/02	sam. 14/02
	2	2	3	3	2	2	3

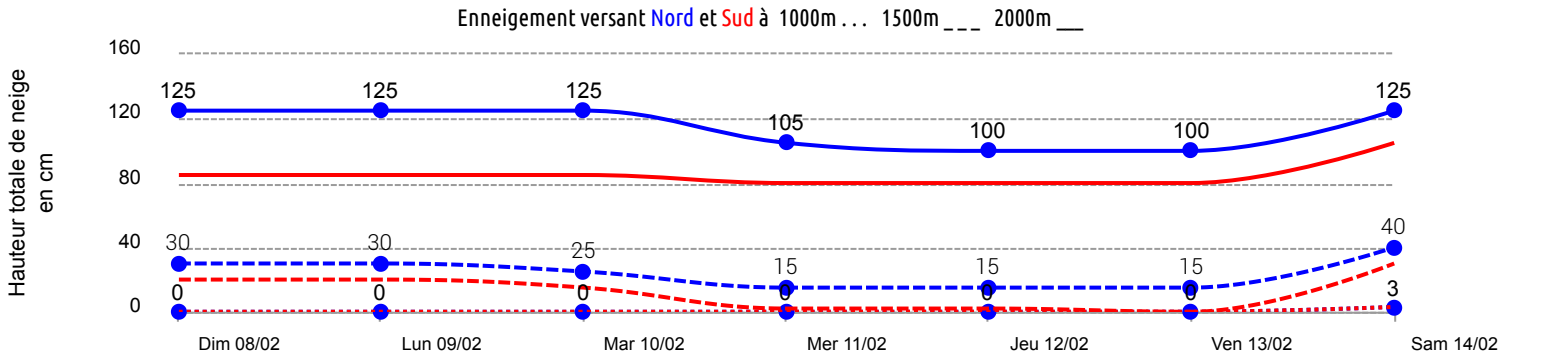

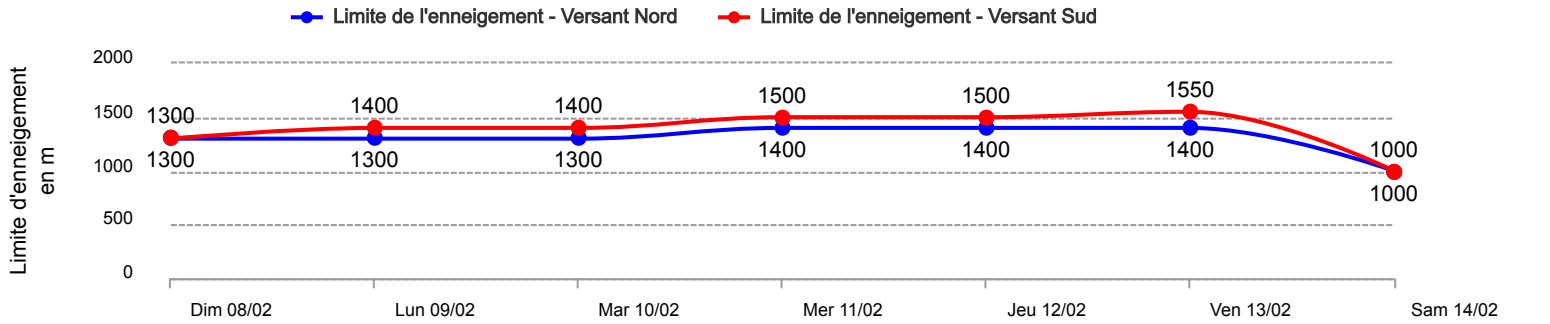

Pour consulter la vigilance en cours, veuillez vous rendre sur le site https://vigilance.meteofrance.fr/fr

Météo-France - 73 avenue de Paris, 94165 Saint-Mandé cedex - Contact : contact@meteo.fr

Rédigé par Météo-France avec la contribution des observateurs du réseau nivo-météorologiques. Partenariat : ANMSM (Maires de Stations de Montagne), DSF (Domaines Skiables de France), ADSP (Directeurs de Pistes et de la Sécurité des Stations de Sports d'Hiver) et autres acteurs de la montagne.

Bulletin neige & avalanches par téléphone au
0 892 68 10 20 Service 0,35 € / min + prix appel