Bulletin d'estimation du risque d'avalanche
(valable en dehors des pistes balisées et ouvertes)

MASSIF : Pelvoux

Rédigé le samedi 14 février 2026 à 16h

Estimation des risques pour le : DIMANCHE 15 FÉVRIER

MANTEAU NEIGEUX INSTABLE - AVALANCHES DE PLAQUES POUVANT ÊTRE VOLUMINEUSES

3

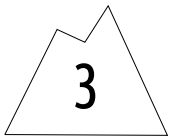

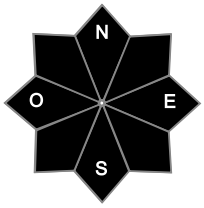

Indice de risque marqué.

Départs spontanés : en plaques avec le transport de neige par le vent, ou en neige récente humidifiée près des rochers au soleil.

Déclenchements provoqués : plaques faciles à déclencher dans la neige récente ventée, parfois volumineuses.

Indices de risque : 5 très fort - 4 fort - 3 marqué - 2 limité - 1 faible -- En noir : les pentes les plus dangereuses

Stabilité du manteau neigeux

Situation avalancheuse typique : neige ventée couche fragile persistante

Déclenchements provoqués : le manteau neigeux reste instable dans de nombreuses pentes. Les plaques sont fréquentes, faciles à déclencher et peuvent se rencontrer dans toutes les orientations. En cas de rupture, elles engendrent des avalanches généralement de taille moyenne à grandes (taille 2 à 3). Ces plaques se situent derrière les crêtes, les cols ou les bosses, mais parfois aussi en milieu de pente. Le vent fort de directions différentes a favorisé et génère encore beaucoup de transport de neige.
De façon très isolée, une très grande avalanche (taille 4) reste envisageable, en cas de rupture très épaisse emportant une grande partie du manteau neigeux en place sur une vaste zone. Un départ de cette ampleur est rare, mais il peut être initié par la surcharge d'une première avalanche de surface suffisamment volumineuse.

Départs spontanés : - quelques départs de plaque, suite à la surcharge liée au transport de neige par le vent. Avalanches reprenant les caractéristiques mentionnées au paragraphe des déclenchements provoqués.
- Quelques départs de neige récente humidifiée, au soleil près des rochers. Avalanches petites en général, ponctuellement moyennes (taille 1 à 2).

Qualité de la neige

L'enneigement est excédentaire pour un mois de février. Les chutes de neige se succèdent depuis le début du mois de janvier.
Hauteurs de neige observées : 280 cm à la Nivôse de Écrins vers 3000 m, 234 cm au Pré de Mme Carle à 1900 m, 160 cm au hameau de Dormillouse à 1730 m.

Limite d'enneigement skiable : la plupart des itinéraires sont skiables dès les fonds de vallées.

État de la neige de surface : manteau neigeux souvent bien travaillé par le vent de nord à nord-ouest. La neige est cartonnée ou durcie par le vent en altitude ; présence de corniches. Il reste encore de nombreux secteurs en neige plus légère, comme les forêts ou les combes et grandes pentes abritées.

Aperçu météo pour le dimanche 15 février

	nuit	matin	après-midi	soir
Pluie-Neige				1 200 m
Iso 0 °C	1 800 m	1 900 m	1 800 m	1 800 m
Vent 2000 m	↓ 40 km/h	→ 35 km/h	↘ 30 km/h	↘ 25 km/h
Vent 3000 m	↓ 80 km/h	↘ 70 km/h	↘ 60 km/h	→ 45 km/h

Matinée généralement ensoleillée. Le ciel se voile, puis se couvre l'après-midi, annonçant l'arrivée d'une perturbation pour la nuit suivante (20/30 cm à 2000 m). Fort vent de nord-ouest toute la journée.

Épaisseur de neige hors-piste

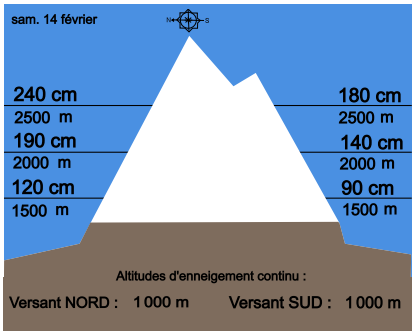

Précipitations à 1800 m

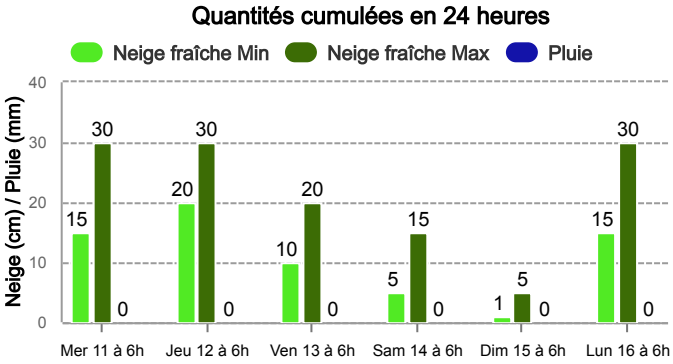

Tendance du lundi 16 février

4 **Indice de risque fort**

Risque d'avalanche en hausse, avec de fortes chutes de neige accompagnées d'un vent d'ouest à nord-ouest particulièrement tempétueux dès la mi-journée (rafales 100/130 km/h en altitude, 70/80 km/h jusqu'en vallées).
Avalanches naturelles de plus en plus nombreuses au fil de la journée, grandes, voire ponctuellement très grandes.

Pour consulter la vigilance en cours, veuillez vous rendre sur le site https://vigilance.meteofrance.fr/fr

Météo-France - 73 avenue de Paris, 94165 Saint-Mandé cedex - Contact : contact@meteo.fr

Rédigé par Météo-France avec la contribution des observateurs du réseau nivo-météorologiques. Partenariat : ANMSM (Maires de Stations de Montagne), DSF (Domaines Skiables de France), ADSP (Directeurs de Pistes et de la Sécurité des Stations de Sports d'Hiver) et autres acteurs de la montagne.

Bulletin neige & avalanches par téléphone au 0 892 68 10 20 Service 0,35 € / min + prix appel

RÉPUBLIQUE FRANÇAISE
Liberté Égalité Fraternité

METEO FRANCE
À VOS CÔTÉS, DANS UN CLIMAT QUI CHANGE

Bulletin d'estimation du risque d'avalanche
(valable en dehors des pistes balisées et ouvertes)

MASSIF : Pelvoux

Rédigé le samedi 14 février 2026 à 16h

Conditions nivo-météo des 7 derniers jours

	dim. 08/02				lun. 09/02				mar. 10/02				mer. 11/02				jeu. 12/02				ven. 13/02				sam. 14/02			
	03h	09h	15h	21h	03h	09h	15h	21h	03h	09h	15h	21h	03h	09h	15h	21h	03h	09h	15h	21h	03h	09h	15h	21h	03h	09h	15h	21h
Météo																												
Vent (km/h)	10	15	20	20	10	15	15	20	30	30	30	80	70	70	50	50	90	80	120	110	65	25	25	30	40	40	60	70
à 3000m																												
Vent (km/h)	5	15	20	20	5	5	10	10	10	15	20	20	20	20	30	25	30	35	65	55	35	15	20	15	15	15	30	45
à 2000m																												

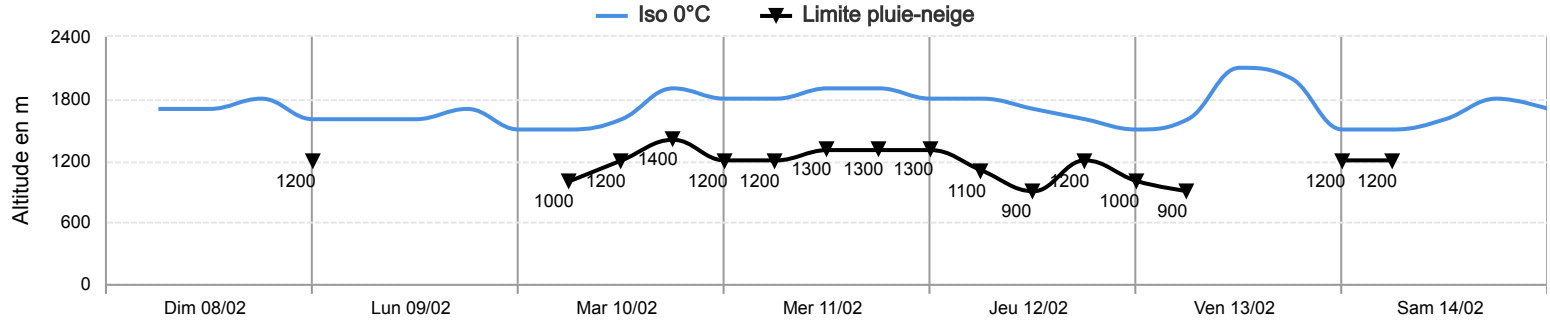

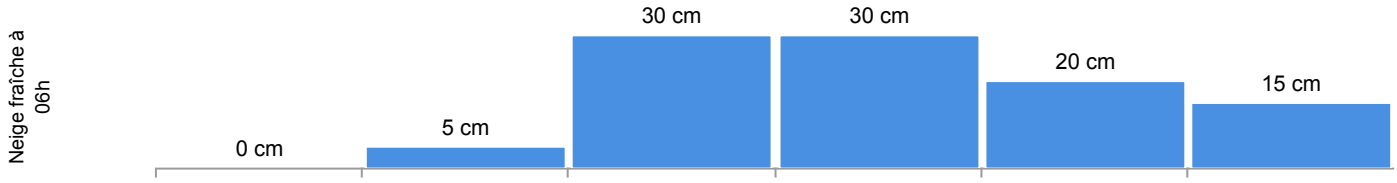

Risque d'avalanche	dim. 08/02	lun. 09/02	mar. 10/02	mer. 11/02	jeu. 12/02	ven. 13/02	sam. 14/02
	3	3	3	4	4	4	4

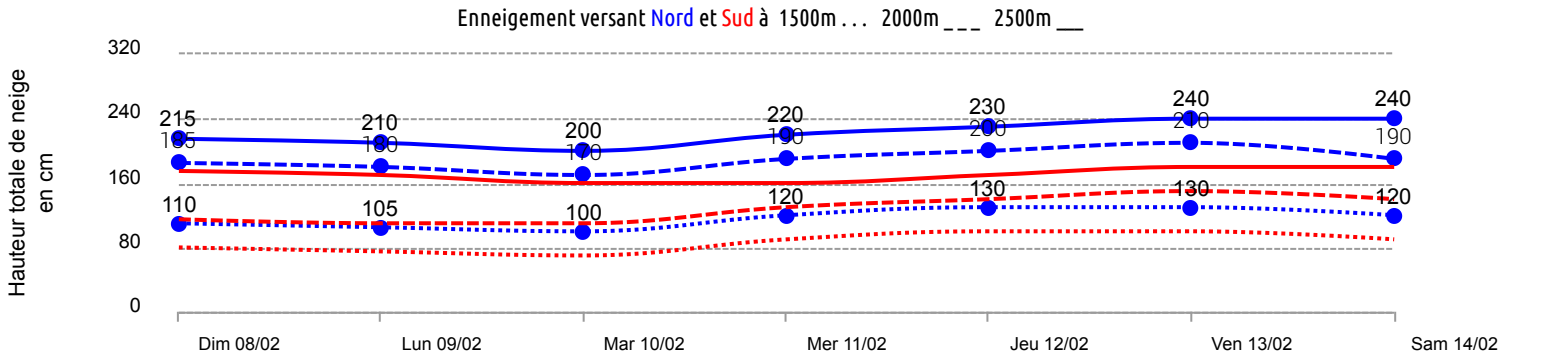

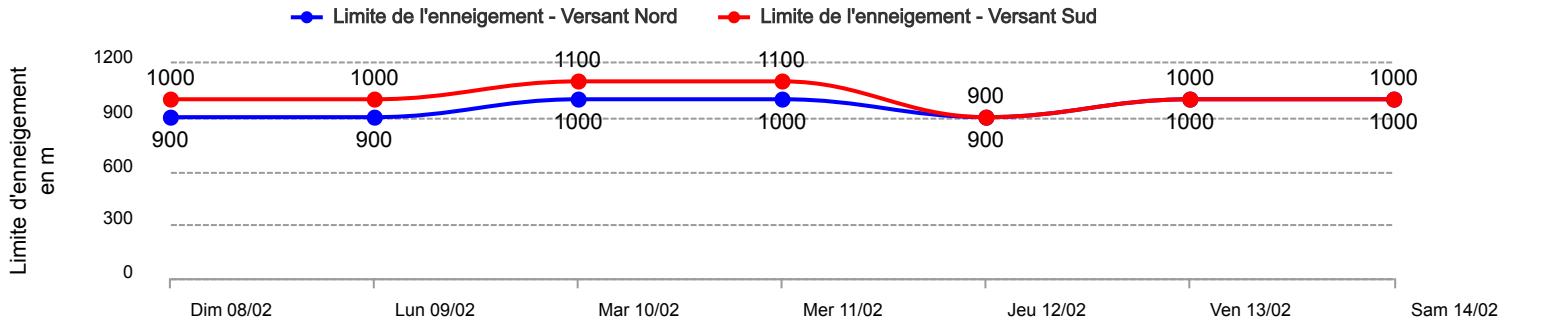

Pour consulter la vigilance en cours, veuillez vous rendre sur le site https://vigilance.meteofrance.fr/fr

Météo-France - 73 avenue de Paris, 94165 Saint-Mandé cedex - Contact : contact@meteo.fr

Rédigé par Météo-France avec la contribution des observateurs du réseau nivo-météorologiques. Partenariat : ANMSM (Maires de Stations de Montagne), DSF (Domaines Skiables de France), ADSP (Directeurs de Pistes et de la Sécurité des Stations de Sports d'Hiver) et autres acteurs de la montagne.

Bulletin neige & avalanches par téléphone au

0 892 68 10 20 Service 0,35 € / min + prix appel