Bulletin d'estimation du risque d'avalanche

(valable en dehors des pistes balisées et ouvertes)

MASSIF : Renoso Incudine

Rédigé le samedi 14 février 2026 à 16h

Estimation des risques pour le : DIMANCHE 15 FÉVRIER

ENCORE DES STRUCTURES DE PLAQUES EN ALTITUDE

2

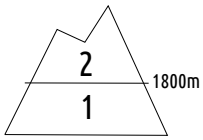

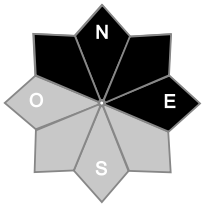

Au-dessus de 1800m indice de risque limité, plus bas indice faible.

Départs spontanés : Activité en baisse, quelques coulées et avalanches de neige sèche au-dessus de 1800 m

Déclenchements provoqués : plaques à vent en altitude

Indices de risque : 5 très fort - 4 fort - 3 marqué - 2 limité - 1 faible -- En noir : les pentes les plus dangereuses

Stabilité du manteau neigeux

Situation avalancheuse typique : neige ventée

Déclenchements provoqués : Plaques à vent en place d'aspect poudreux ou dures pouvant être masqués par la couche de neige fraîche en surface. Elles se situent principalement au-dessus de 1800/2000m environ, en tout versant là où le manteau neigeux n'a pas "connu" la pluie. Ces instabilités sont plutôt présentes en pentes raides, jusque loin en contrebas des crêtes. Surtout sensible à de forte surcharge elles sont généralement de taille petite à moyenne (taille 1 à 2). Les volumes de neige mobilisés peuvent être plus importants, en versants froids si l'avalanche entraîne la cassure d'une accumulation plus ancienne et enfouie, reposant sur une sous couche fragile persistante. Leur sollicitation est parfois possible là où l'épaisseur de neige est moins importante (abords des combes, ruptures de pente....) mais elles sont difficilement déclenchables car maintenant enfouies assez profondément..
En dessous de 1800 m, il est difficile de provoquer une avalanche dans ce manteau neigeux humide et tassé. Un skieur peut éventuellement favoriser un départ ponctuel en coupant une pente raide en neige humide.
Attention aux corniches formées récemment, grosses et fragiles.

Départs spontanés : Quelques coulées et avalanches de neige récente de taille petite à moyenne, dans les zones d'accumulation à la faveur des éclaircies.

Autres : Risque de glissade en neige dure ou glacée sur les crêtes et sommets balayés par les vents.

Qualité de la neige

Qualification de l'enneigement : L'enneigement est excellent pour la saison à toutes altitudes. On relève plus de 2 mètres dans les combes abritées.
Limite d'enneigement skiable : vers 1500 m.
État de la neige : un peu de neige récente humide recouvrira en dessous de 1800m une neige croutée plus ou moins portante. En altitude, elle reste sèche, légère à l'abri du vent d'Ouest. On trouve localement des accumulations de neige roulée. La neige est très changeante (dure, carton, regelée) dans les secteurs ventés. Corniches et accumulations parfois volumineuses en place. Les crêtes et sommets, balayés par le vent d'Ouest, sont souvent durs et glacés.

Aperçu météo pour le dimanche 15 février

	nuit	matin	après-midi	soir
Pluie-Neige				
Iso 0 °C	2 000 m	2 100 m	2 200 m	1 800 m
Vent 1500 m	↓ 35 km/h	↓ 20 km/h	↘ 25 km/h	↘ 60 km/h
Vent 2000 m	↓ 40 km/h	↓ 30 km/h	↘ 30 km/h	↘ 70 km/h

Épaisseur de neige hors-piste

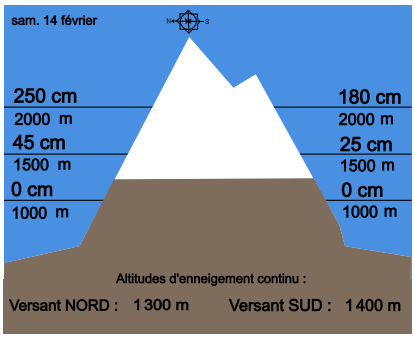

Précipitations à 1800 m

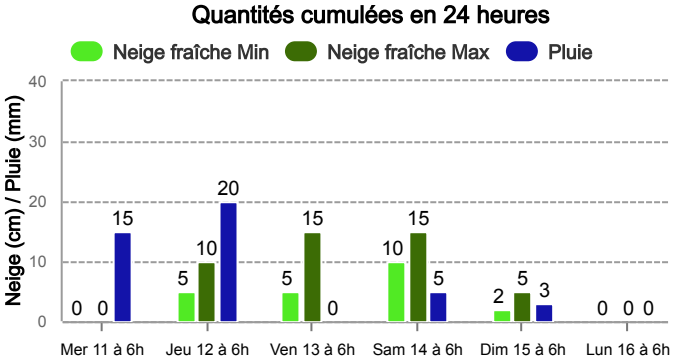

Tendance du lundi 16 février

3

Indice de risque marqué

Risque en hausse en altitude avec de nouvelles chutes de neige et le vent fort d'ouest.

Pour consulter la vigilance en cours, veuillez vous rendre sur le site https://vigilance.meteofrance.fr/fr

Météo-France - 73 avenue de Paris, 94165 Saint-Mandé cedex - Contact : contact@meteo.fr

Rédigé par Météo-France avec la contribution des observateurs du réseau nivo-météorologiques. Partenariat : ANMSM (Maires de Stations de Montagne), DSF (Domaines Skiables de France), ADSP (Directeurs de Pistes et de la Sécurité des Stations de Sports d'Hiver) et autres acteurs de la montagne.

Bulletin neige & avalanches par téléphone au **0 892 68 10 20** Service 0,35 € / min + prix appel

RÉPUBLIQUE FRANÇAISE
Liberté Égalité Fraternité

METEO FRANCE
À VOS CÔTÉS, DANS UN CLIMAT QUI CHANGE

Bulletin d'estimation du risque d'avalanche

(valable en dehors des pistes balisées et ouvertes)

MASSIF : Renoso Incudine

Rédigé le samedi 14 février 2026 à 16h

Conditions nivo-météo des 7 derniers jours

	dim. 08/02				lun. 09/02				mar. 10/02				mer. 11/02				jeu. 12/02				ven. 13/02				sam. 14/02			
	03h	09h	15h	21h	03h	09h	15h	21h	03h	09h	15h	21h	03h	09h	15h	21h	03h	09h	15h	21h	03h	09h	15h	21h	03h	09h	15h	21h
Météo																												
Vent (km/h)	50	15	30	15	10	5	15	10	20	20	30	50	80	110	120	110	80	120	120	120	60	50	35	70	50	20	40	40
à 2000m	→	↖	↑	↗	↑	→	→	→	→	→	→	→	→	→	→	→	→	→	↘	↘	↘	→	→	↑	↗	↖	↙	↙
Vent (km/h)	60	15	25	15	15	15	15	10	15	15	25	40	60	100	110	100	80	120	130	120	60	45	30	40	40	20	35	35
à 1500m	→	↖	←	←	↗	↘	→	→	→	→	→	→	→	→	→	→	→	→	→	↘	→	→	→	↖	↗	↖	↙	↓

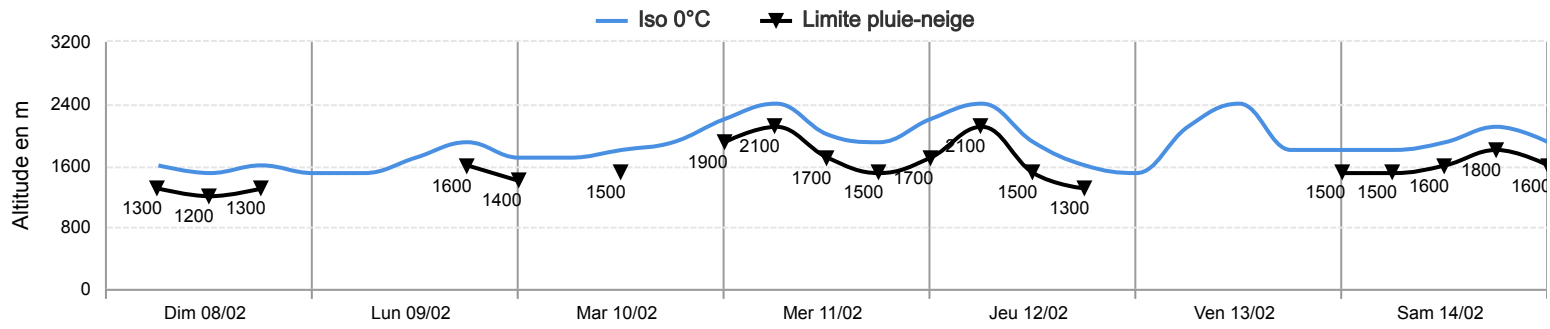

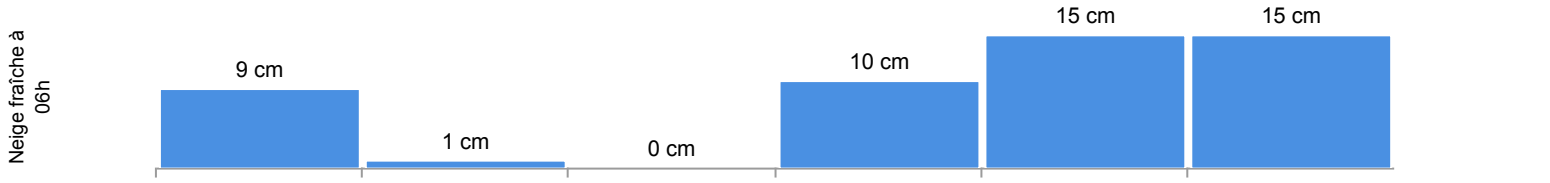

Risque d'avalanche	dim. 08/02	lun. 09/02	mar. 10/02	mer. 11/02	jeu. 12/02	ven. 13/02	sam. 14/02
	3	3	2	3	3	3	3

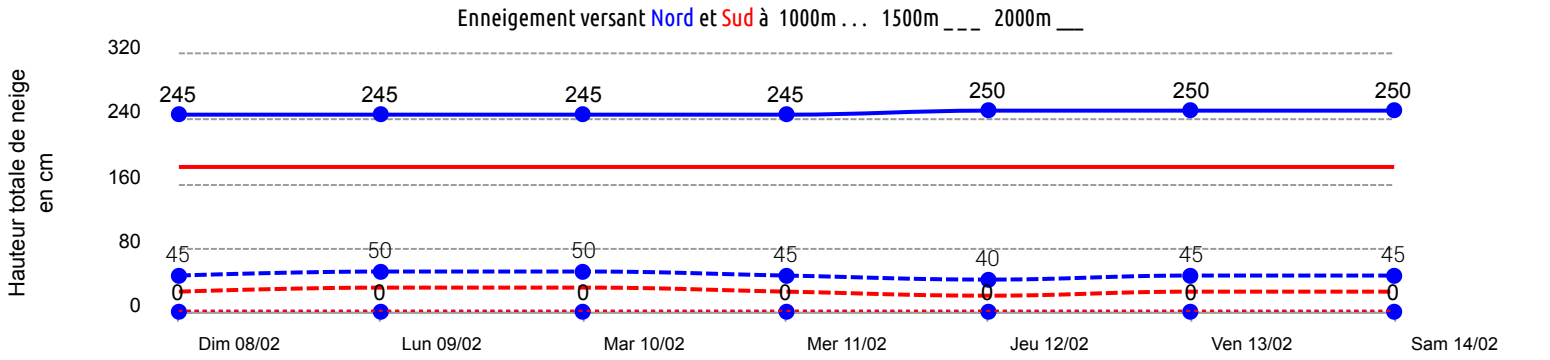

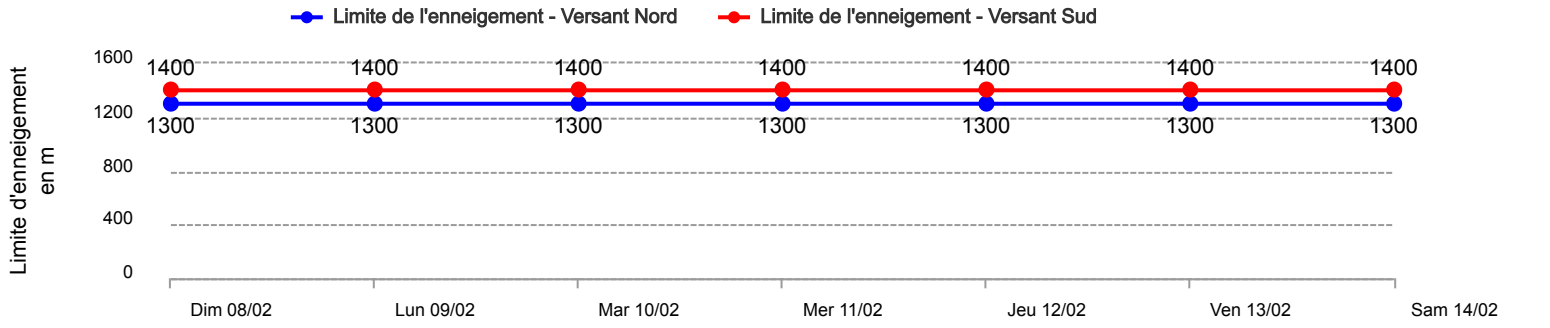

Pour consulter la vigilance en cours, veuillez vous rendre sur le site https://vigilance.meteofrance.fr/fr

Météo-France - 73 avenue de Paris, 94165 Saint-Mandé cedex - Contact : contact@meteo.fr

Bulletin neige & avalanches par téléphone au

0 892 68 10 20 Service 0,35 € / min + prix appel

Rédigé par Météo-France avec la contribution des observateurs du réseau nivo-météorologiques. Partenariat : ANMSM (Maires de Stations de Montagne), DSF (Domaines Skiables de France), ADSP (Directeurs de Pistes et de la Sécurité des Stations de Sports d'Hiver) et autres acteurs de la montagne.