Bulletin d'estimation du risque d'avalanche
(valable en dehors des pistes balisées et ouvertes)

MASSIF : Grandes-Rousses

Rédigé le samedi 14 février 2026 à 17h

Estimation des risques pour le : DIMANCHE 15 FÉVRIER

FORTE INSTABILITÉ SURTOUT EN DÉPARTS ACCIDENTELS ET EN ALTITUDE

3

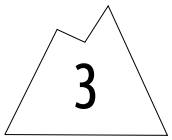

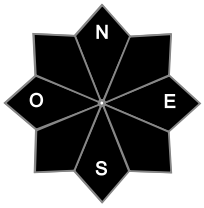

instable en altitude

Indice de risque marqué.

Départs spontanés : activité spontanée en baisse se limitant à quelques pentes raides. Rares départs d'ampleur à plus haute altitude encore possible.

Déclenchements provoqués : En altitude, risque accidentel toujours présent, près des crêtes comme en pleine pente avec le vent de Nord encore fort.

Indices de risque : 5 très fort - 4 fort - 3 marqué - 2 limité - 1 faible -- En noir : les pentes les plus dangereuses

Stabilité du manteau neigeux

Situation avalancheuse typique :

neige ventée

neige fraîche

Départs spontanés :

Ce risque est en nette baisse par rapport au derniers jours.
Pour dimanche, on peut attendre lors de brèves éclaircies, encore quelques coulées ou avalanches poudreuses près des rochers notamment. Aux altitudes modestes (sous 1600/1800m environ), la neige est assez humide en profondeur, on peut avoir quelques avalanches en pentes herbeuses, parfois de fond (glissement au terrain).
En haute montagne (au-dessus de 2200/2400m), la présence de sous couche fragile persistante qui pourrait rendre quelques rares avalanches de très grande ampleur encore possible.

Déclenchements provoqués :

Le risque accidentel reste marqué surtout en haute montagne et dès 2000/2200m, de nombreuses plaques encore bien instables, parfois loin des crêtes. Le vent a soufflé en diverses orientations favorisant la formation de nouvelles plaques.
Dans un large secteur Nord, des sous couches fragiles sont encore enfouies et une première rupture de plaque pourrait entrainer une épaisse et large cassure en contrebas, entrainant un volume de neige conséquent.
Plus bas que 1800/2000m environ, les sous couches sont un peu mieux stabilisées, risque de plaques surtout à proximité des crêtes, il est globalement plus faible.

Qualité de la neige

Qualification de l'enneigement : L'enneigement s'est encore amélioré en altitude, dans les combes, où il devient excellent pour la saison, notamment versant Vaujany.

Limites skiables : vers 1100 m.

Qualité de la neige dimanche :

Neige fraîche poudreuse plus épaisse en altitude et souvent soufflée/chahutée à l'abord des croupes et crêtes.
A 800/1000m, fine couche de 5/10 cm environ au matin.
Fortes épaisseurs au dessus de 2000m environ avec plus d'1m de neige récente vers 2500m, de grosses congères/corniches, des secteurs plus dégarnis...

Aperçu météo pour le dimanche 15 février

	nuit	matin	après-midi	soir
Pluie-Neige	1 000 m		1 200 m	1 500 m
Iso 0 °C	1 400 m	1 700 m	1 900 m	1 900 m
Vent 2000 m	↖ 5 km/h	↓ 10 km/h	↘ 25 km/h	↘ 20 km/h
Vent 3000 m	↓ 50 km/h	↓ 45 km/h	↘ 45 km/h	↘ 45 km/h

Matinée plutot calme avec des éclaircies possibles avec un temps plus couvert et une nouvelle perturbation en fin de journée.

Épaisseur de neige hors-piste

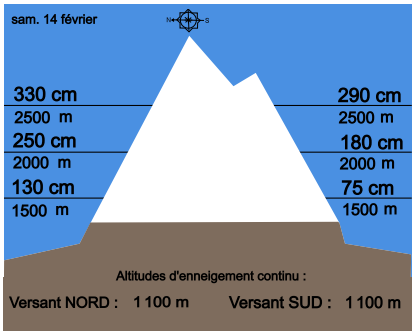

Précipitations à 1800 m

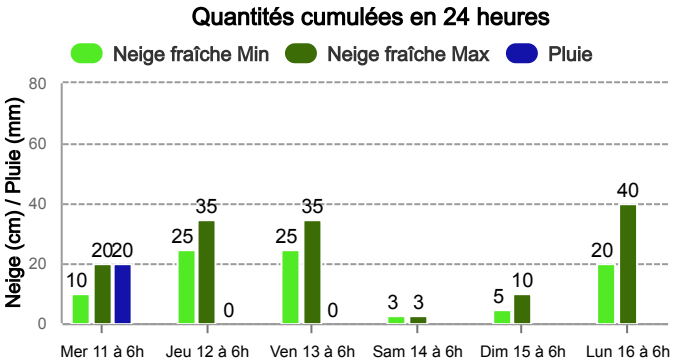

Tendance du lundi 16 février

4

Indice de risque fort

Risque en hausse progressive avec de nouvelles chutes de neige conséquentes prévues.

Pour consulter la vigilance en cours, veuillez vous rendre sur le site https://vigilance.meteofrance.fr/fr

Météo-France - 73 avenue de Paris, 94165 Saint-Mandé cedex - Contact : contact@meteo.fr

Rédigé par Météo-France avec la contribution des observateurs du réseau nivo-météorologiques. Partenariat : ANMSM (Maires de Stations de Montagne), DSF (Domaines Skiables de France), ADSP (Directeurs de Pistes et de la Sécurité des Stations de Sports d'Hiver) et autres acteurs de la montagne.

Bulletin neige & avalanches par téléphone au
0 892 68 10 20 Service 0,35 € / min + prix appel

RÉPUBLIQUE FRANÇAISE
Liberté Égalité Fraternité

METEO FRANCE
À VOS CÔTÉS, DANS UN CLIMAT QUI CHANGE

Bulletin d'estimation du risque d'avalanche

(valable en dehors des pistes balisées et ouvertes)

MASSIF : Grandes-Rousses

Rédigé le samedi 14 février 2026 à 17h

Conditions nivo-météo des 7 derniers jours

	dim. 08/02				lun. 09/02				mar. 10/02				mer. 11/02				jeu. 12/02				ven. 13/02				sam. 14/02			
	03h	09h	15h	21h	03h	09h	15h	21h	03h	09h	15h	21h	03h	09h	15h	21h	03h	09h	15h	21h	03h	09h	15h	21h	03h	09h	15h	21h
Météo																												
Vent (km/h)	15	20	25	25	30	15	15	25	35	35	50	60	100	85	85	100	100	100	90	40	35	25	35	15	25	20	50	45
à 3000m																												
Vent (km/h)	10	15	15	20	20	10	15	10	15	20	30	40	80	65	50	50	50	50	55	15	10	10	10	20	25	5	20	10
à 2000m																												

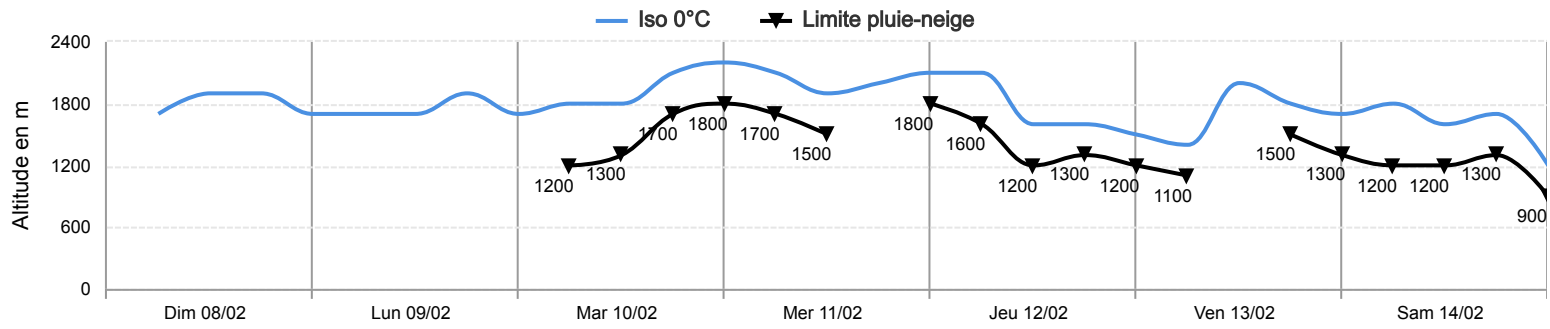

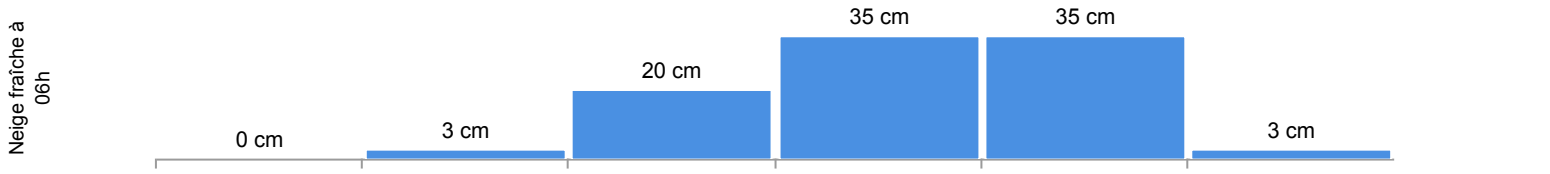

Risque d'avalanche	dim. 08/02	lun. 09/02	mar. 10/02	mer. 11/02	jeu. 12/02	ven. 13/02	sam. 14/02
	3	3	3	4	5	4	4

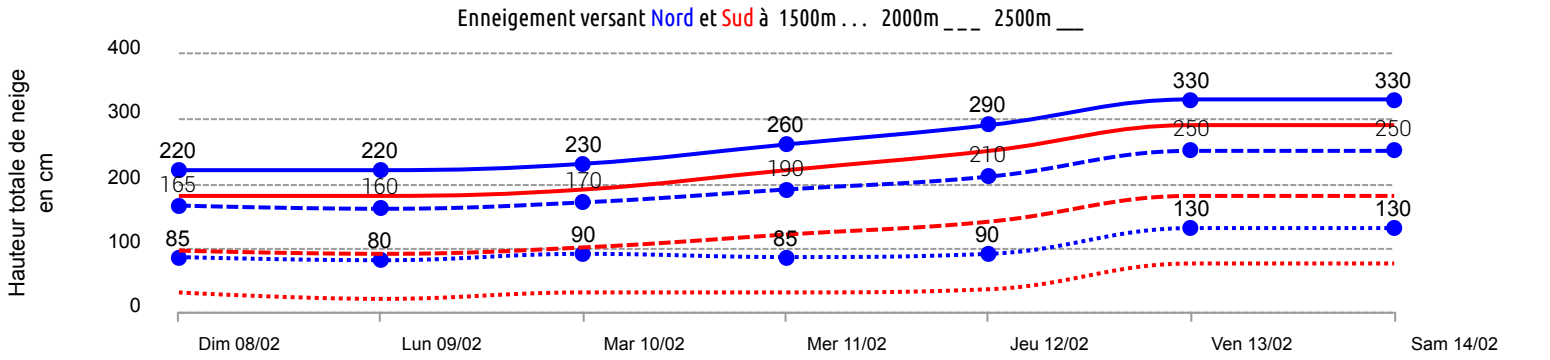

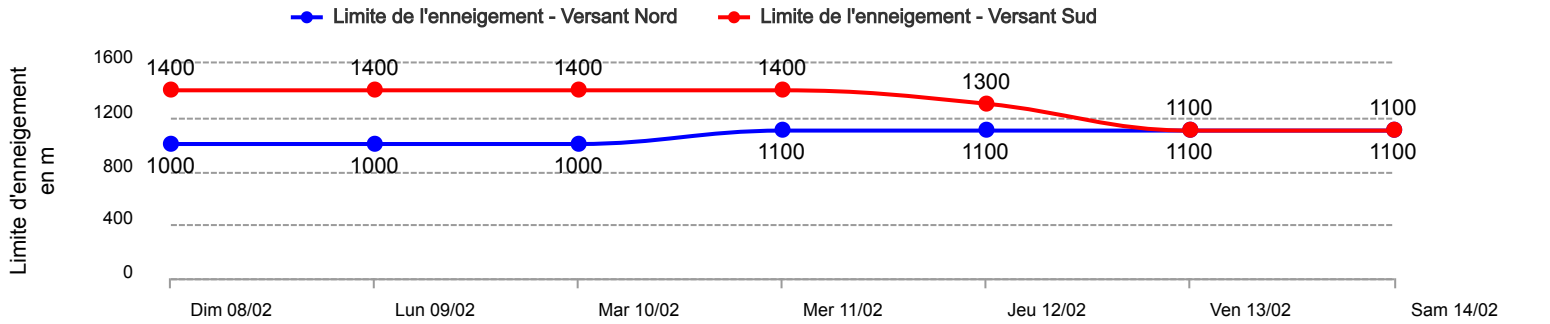

Pour consulter la vigilance en cours, veuillez vous rendre sur le site https://vigilance.meteofrance.fr/fr

Météo-France - 73 avenue de Paris, 94165 Saint-Mandé cedex - Contact : contact@meteo.fr

Rédigé par Météo-France avec la contribution des observateurs du réseau nivo-météorologiques. Partenariat : ANMSM (Maires de Stations de Montagne), DSF (Domaines Skiables de France), ADSP (Directeurs de Pistes et de la Sécurité des Stations de Sports d'Hiver) et autres acteurs de la montagne.

Bulletin neige & avalanches par téléphone au
0 892 68 10 20 Service 0,35 € / min + prix appel