GOBIERNO DE ESPAÑA
VICEPRESIDENCIA TERCERA DEL GOBIERNO
MINISTERIO PARA LA TRANSICIÓN ECOLÓGICA Y EL RETO DEMOGRÁFICO

Boletín de información nivológica y de peligro de aludes

Pirineo Navarro y Aragonés

aemet Agencia Estatal de Meteorología

domingo, 15 de febrero de 2026

Pronóstico hasta las 24 horas del lunes, día 16 de febrero

(Válido fuera de pistas de esquí balizadas y abiertas)

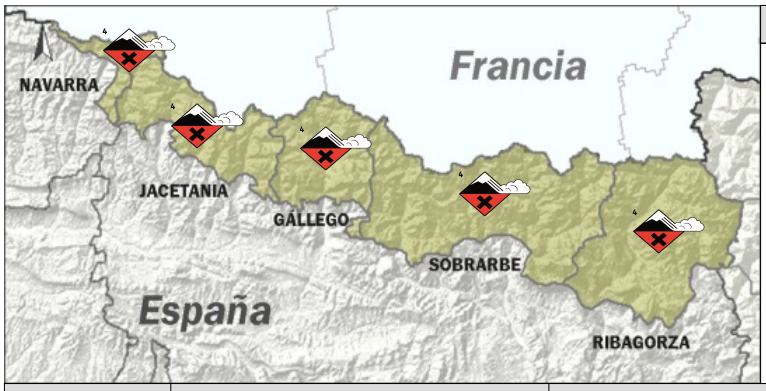

Problemas de aludes

Placas de viento

Nieve húmeda

Macizo	Peligro	Problemas de aludes, cota, orientación, tamaño	Innivación observada (m)
Navarra	4 Fuerte	**Placas de viento**: 2100, N O E S, 3 **Nieve húmeda**: 2100, N O E S, 3	2026-02-15 N S Cotas bajas
Jacetania	4 Fuerte	**Placas de viento**: 2100, N O E S, 3 **Nieve húmeda**: 2100, N O E S, 3	2026-02-15 N S Cotas bajas
Gállego	4 Fuerte	**Placas de viento**: 2100, N O E S, 3 **Nieve húmeda**: 2100, N O E S, 3	2026-02-15 N S Cotas bajas

AEMET. Se autoriza la reproducción de su contenido citando la fuente.

Boletín de información nivológica y de peligro de aludes

Pirineo Navarro y Aragonés

Sobrarbe	 **Fuerte**	**Placas de viento** 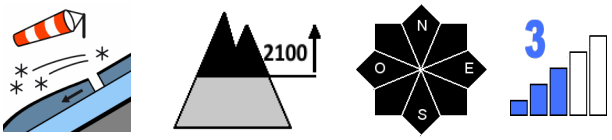 **Nieve húmeda** 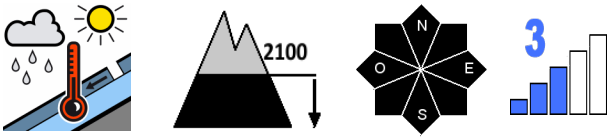	2026-02-15
Ribagorza	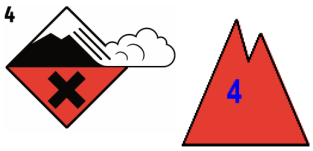 **Fuerte**	**Placas de viento** 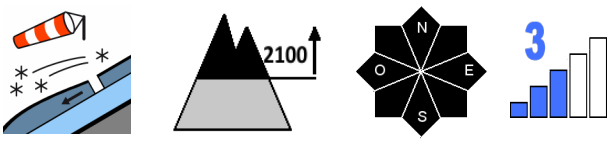 **Nieve húmeda** 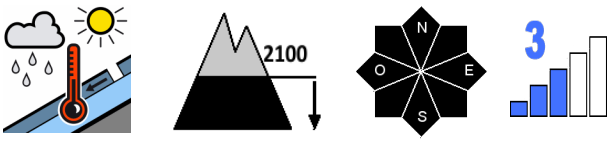	2026-02-15

Estado del manto y observaciones recientes

Se han vuelto a producir nevadas, depositando durante las últimas 24 horas cantidades de hasta 25 cm en algunos de los puntos de observación, aunque en otras zonas de la cordillera las intensas ventiscas han arrastrado gran cantidad de nieve y ello ha supuesto una merma en el grosor del manto. Pese a estos condicionantes, sigue siendo continuo desde fondos de valle, con espesores muy por encima del promedio habitual a estas alturas de la temporada, pues en torno a 2.100 metros se superan fácilmente los 180 a 200 cm, aún más en ventisqueros, hoyas y otras zonas propensas a la acumulación.

El perfil del manto consta de múltiples capas, la más externa de nieve reciente de grosor variable y algunas de ellas compuestas por estratos encostrados, aunque predomina el grano fino y grano redondo. En la alta montaña la nieve se presenta más seca, menos evolucionada y, sobre todo, muy venteada, pues se han formado numerosas placas.

Se han registrado aludes de nieve reciente seca, de tamaño pequeño en general, y alguno de placa friable.

Evolución del manto y peligro de aludes para el lunes, día 16

Situación de placas de viento en cotas altas, así como de nieve húmeda.

Para las próximas 24 horas se prevén nuevas precipitaciones, que podrán ser en forma líquida hasta altitudes considerables, de manera que la lluvia irá percolando por el manto y tenderá a inestabilizarlo en cotas medias y bajas, siendo probables las purgas de nieve húmeda en pendientes con suficiente inclinación y sin orientación preferente, que podrán ser de tamaño mediano o incluso grande, sin descartarse del todo la posibilidad de algún deslizamiento basal que, dada la importante acumulación de nieve en la cordillera, pueda adquirir dimensiones muy grandes y alcanzar fondos de valle.

AEMET. Se autoriza la reproducción de su contenido citando la fuente.

En cotas altas, los fuertes vientos de componentes oeste y norte seguirán formando placas en diferentes áreas, con preferencia en orientaciones este y sur. Estas vendrán a sumarse a las que ya existen, algunas de ellas asentadas sobre estratos débiles, y que han quedado enterradas tras las nevadas de jornadas previas, lo que dificulta su localización. Todas estas estructuras permanecen frágiles y podrán fracturarse ante sobrecargas débiles, dando lugar a aludes que podrán ser de dimensiones grandes, suficiente como para enterrar a un grupo de personas, por lo que se recomienda extremar las precauciones si se va a transitar por la zona.

Predicción meteorológica para el lunes, día 16

Predominio de cielos muy nubosos o cubiertos, con precipitaciones débiles o moderadas, más frecuentes en el Pirineo navarro, Jacetania, Alto Gállego y resto de la divisoria fronteriza, donde podrán ser persistentes. Cota de nieve: 1.800 a 2.000 metros, aunque con tendencia a descender al final del día a unos 1.600. Temperaturas mínimas en moderado o notable ascenso, y máximas sin cambios o en ligero descenso. Heladas débiles en la alta montaña, localmente moderadas. Vientos fuertes del oeste y noroeste, con rachas muy fuertes en cotas altas y zonas expuestas, donde no se descarta que puedan ser huracanadas.

Datos en la atmósfera libre:

Altitud de la isoterma de 0 ºC: 2.300 m
Altitud de la isoterma de -10 ºC: 4.100 m

Viento a 1500 m: NW 60 km/h
Viento a 3000 m: NW 100 km/h

Evolución para el martes día 17

Nivel de peligro sin grandes cambios.

(Información elaborada a partir de los datos recibidos de los refugios de Lizara, Panticosa, Bachimaña, Góriz, Pineta, Estós, Angel Orús, La Renclusa y Cap de Llauset, de las estaciones de esquí de Candanchú, Astún y Formigal y de la estación de esquí de fondo de Llanos del Hospital)

Escala europea de peligro de aludes

Débil | Limitado | Notable | Fuerte | Muy Fuerte

Problemas de aludes

Nieve reciente | Placas de viento | Capas débiles persistentes | Nieve húmeda | Deslizamientos basales | Sin problema evidente

Nota1: Se recuerda que, siempre que haya nieve, la ausencia total de peligro no existe. Hay que tener presente que en circunstancias desfavorables, con aludes de tamaño 1 (alud pequeño o colada) y tamaño 2 (alud mediano), se pueden sufrir severos daños personales.

Nota2: Los BPA se elaboran en base a información meteorológica así como al estado del manto nivoso a través de sondeos puntuales. Se advierte a los usuarios de la variabilidad de esta información al extrapolarla a zonas extensas de montaña. Por ello, AEMET no se hace responsable de su uso para la toma de decisiones que conciernen a la seguridad personal, ni de los riesgos físicos o materiales de ellas derivadas.

AEMET. Se autoriza la reproducción de su contenido citando la fuente.