Montag 16.02.2026

Veröffentlicht am 15.02.2026 um 17:00

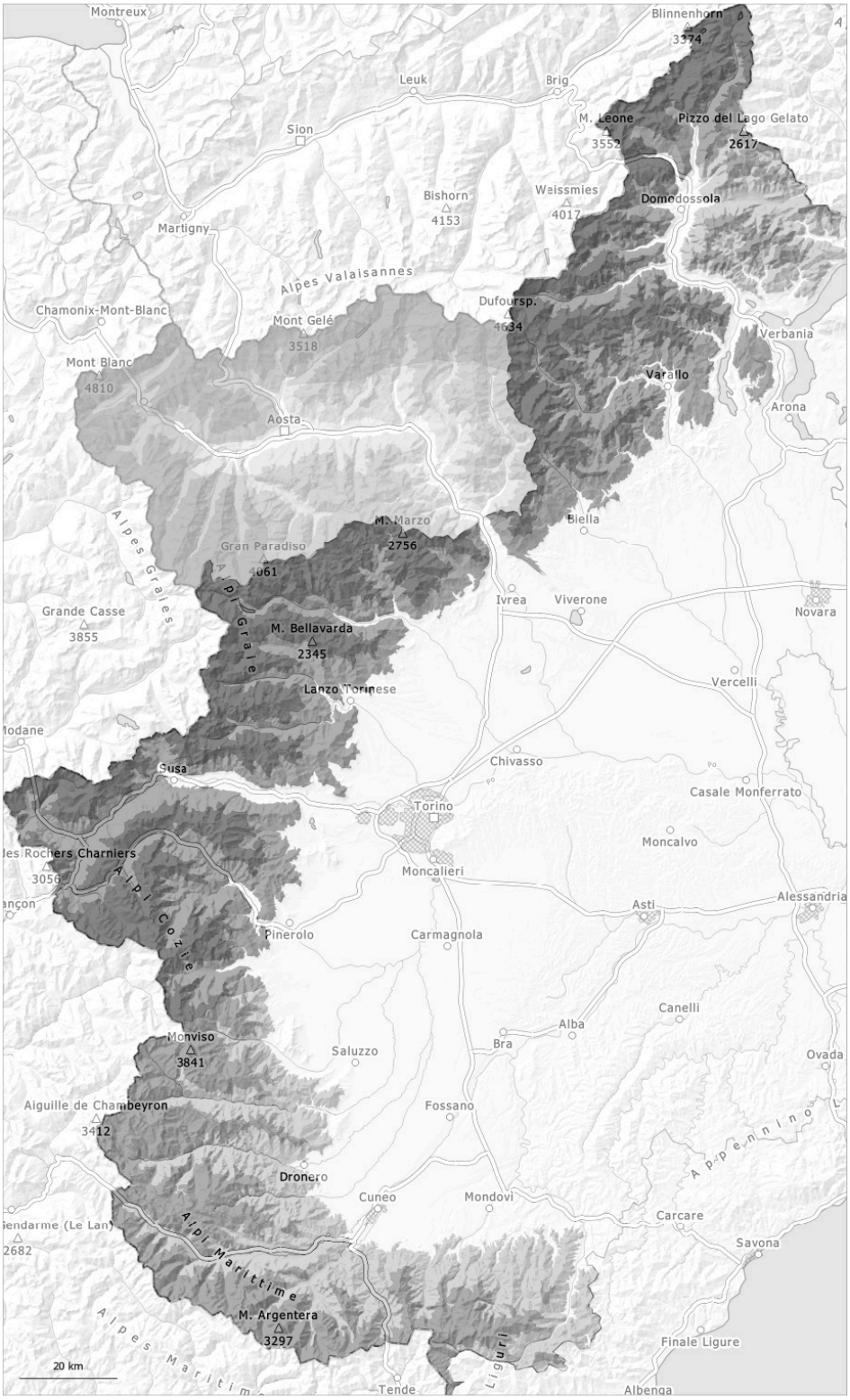

1	2	3	4	5
gering	mäßig	erheblich	groß	sehr groß

Gefahrenstufe 4 - Groß

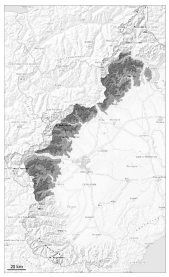

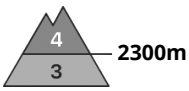

Tendenz: Lawinengefahr nimmt ab
am Dienstag, den 17.02.2026

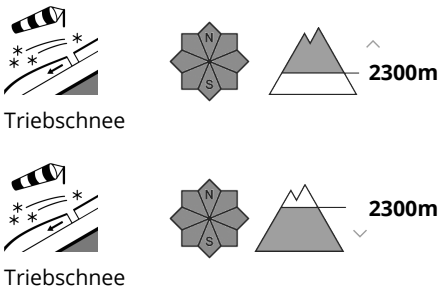

Allmählicher Anstieg der Lawinengefahr mit Neuschnee und Wind.

Bis am Abend fallen verbreitet oberhalb von rund 1400 m 10 bis 25 cm Schnee.
Der teilweise starke Wind verfrachtet Neu- und Altschnee. Mit Schneefall und mäßigem bis starkem Nordwestwind entstehen im Tagesverlauf frische Triebschneeansammlungen. Diese entstehen vor allem zwischen etwa 2100 und 2500 m.
Die frischen und älteren Triebschneeansammlungen können oberhalb der Waldgrenze schon von einzelnen Wintersportlern ausgelöst werden.

Dort wo lokal der Wind stärker bläst wird die Gefahrenstufe 4, "groß" erreicht.

Schneedecke

Gefahrenmuster gm.6: lockerer schnee und wind

Der teilweise starke Wind verfrachtet den Neuschnee und teilweise auch Altschnee.
V.a. in Gipfellagen liegen je nach Windeinfluss sehr unterschiedliche Schneehöhen.

In der Altschneedecke sind vor allem an steilen Nordwest-, Nord- und Osthängen Schwachschichten vorhanden.

Gefahrenstufe 4 - Groß

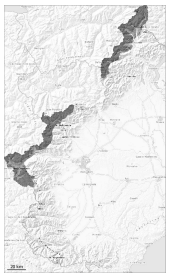

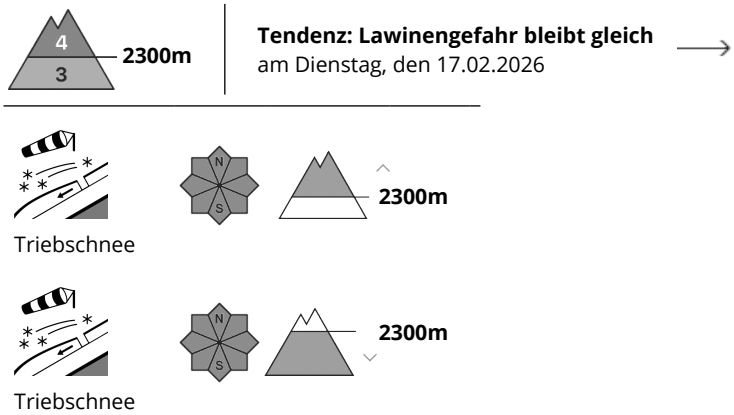

Allmählicher Anstieg der Lawinengefahr mit Neuschnee und Sturm.

Bis am Abend fallen v.a. entlang der Grenze zu Frankreich, entlang der Grenze zwischen dem Wallis und Italien oberhalb von rund 1700 m 25 bis 40 cm Schnee, lokal bis zu 60 cm.

Mit Schneefall und teils starkem Nordwestwind entstehen im Tagesverlauf frische Triebschneeansammlungen. Der starke Wind verfrachtet den Neuschnee und teilweise auch Altschnee. Die teils großen Triebschneeansammlungen können oberhalb der Waldgrenze schon von einzelnen Wintersportlern leicht ausgelöst werden.
An steilen Hängen und in Rinnen, Mulden und hinter Geländekanten ist die Lawinensituation sehr heikel.

An Triebschneehängen und in Kammlagen sind mittlere bis große Schneebrettlawinen möglich, vereinzelt auch aus steilen und hoch gelegenen südostseitigen und noch nicht entladenen Einzugsgebieten.

Schneedecke

Gefahrenmuster gm.6: lockerer schnee und wind

Der teilweise stürmische Wind verfrachtet Neu- und Altschnee intensiv.
V.a. in Gipfellagen liegen je nach Windeinfluss sehr unterschiedliche Schneehöhen.

In der Altschneedecke sind vor allem an steilen Nordwest-, Nord- und Osthängen Schwachschichten vorhanden. Verschiedene Triebschneeschichten liegen stellenweise auf Oberflächenreif.

Gefahrenstufe 3 - Erheblich

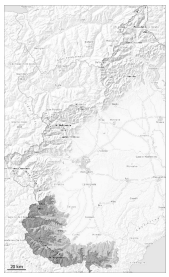

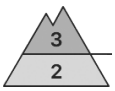

Waldgrenze

Tendenz: Lawinengefahr bleibt gleich
am Dienstag, den 17.02.2026

Triebschnee

Waldgrenze

Nassschnee

1800m

Triebschnee im Hochgebirge. Nass- und Gleitschnee in tiefen Lagen.

Mit mäßigem Wind aus nordwestlichen Richtungen entstehen in der Höhe Triebschneeansammlungen. Triebschneeansammlungen können schon von einzelnen Wintersportlern ausgelöst werden. Dies vor allem an steilen Schattenhängen im Hochgebirge sowie an Triebschneehängen, auch an Übergängen in Rinnen und Mulden in den Gebieten mit viel Wind.

Vereinzelt können Lawinen auch im Altschnee anbrechen und groß werden.

An steilen Hängen und in tiefen Lagen sind bis am Mittag weiterhin feuchte Lawinen möglich, aber diese können teils mittlere Größe erreichen.

Schneedecke

Gefahrenmuster gm.6: lockerer schnee und wind

In den letzten Tagen entstanden verbreitet harte Triebschneeansammlungen. Der teilweise stürmische Wind hat den Neuschnee intensiv verfrachtet. In Gipfellagen liegen je nach Windeinfluss sehr unterschiedliche Schneehöhen.

Mit mäßigem Wind aus nordwestlichen Richtungen entstehen meist kleine Triebschneeansammlungen.

In der Altschneedecke sind vor allem an steilen Nordwest-, Nord- und Nordosthängen Schwachschichten vorhanden.

Sonne und Wärme führten in tiefen Lagen zu einer Anfeuchtung der Altschneedecke.

Gefahrenstufe 3 - Erheblich

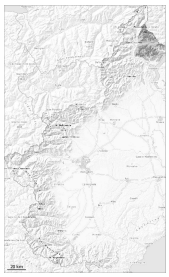

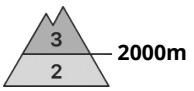

Tendenz: Lawinengefahr bleibt gleich
am Dienstag, den 17.02.2026

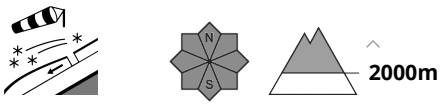

Triebschnee

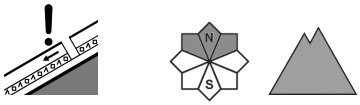

Altschnee

Mit Neuschnee und Wind nehmen die Gefahrenstellen zu.

Bis am Abend fallen lokal oberhalb von rund 1000 m 10 bis 20 cm Schnee.
Mit Schneefall und mäßigem bis starkem Wind entstehen im Tagesverlauf frische Triebschneeansammlungen. Die alten Triebschneeansammlungen werden überschneit und damit schwierig zu erkennen.
Frische und schon etwas ältere Triebschneeansammlungen können teilweise von einzelnen Wintersportlern ausgelöst werden.
Die Gefahrenstellen liegen besonders in Rinnen, Mulden und hinter Geländekanten sowie an Übergängen von wenig zu viel Schnee.

Sehr vereinzelt können Lawinen auch im Altschnee anbrechen und groß werden.

Schneedecke

Gefahrenmuster gm.6: lockerer schnee und wind

In der Altschneedecke sind v.a. an steilen West-, Nord- und Osthängen Schwachschichten vorhanden.