# Lundi 16.02.2026

Publié 15 02 2026, 17:00

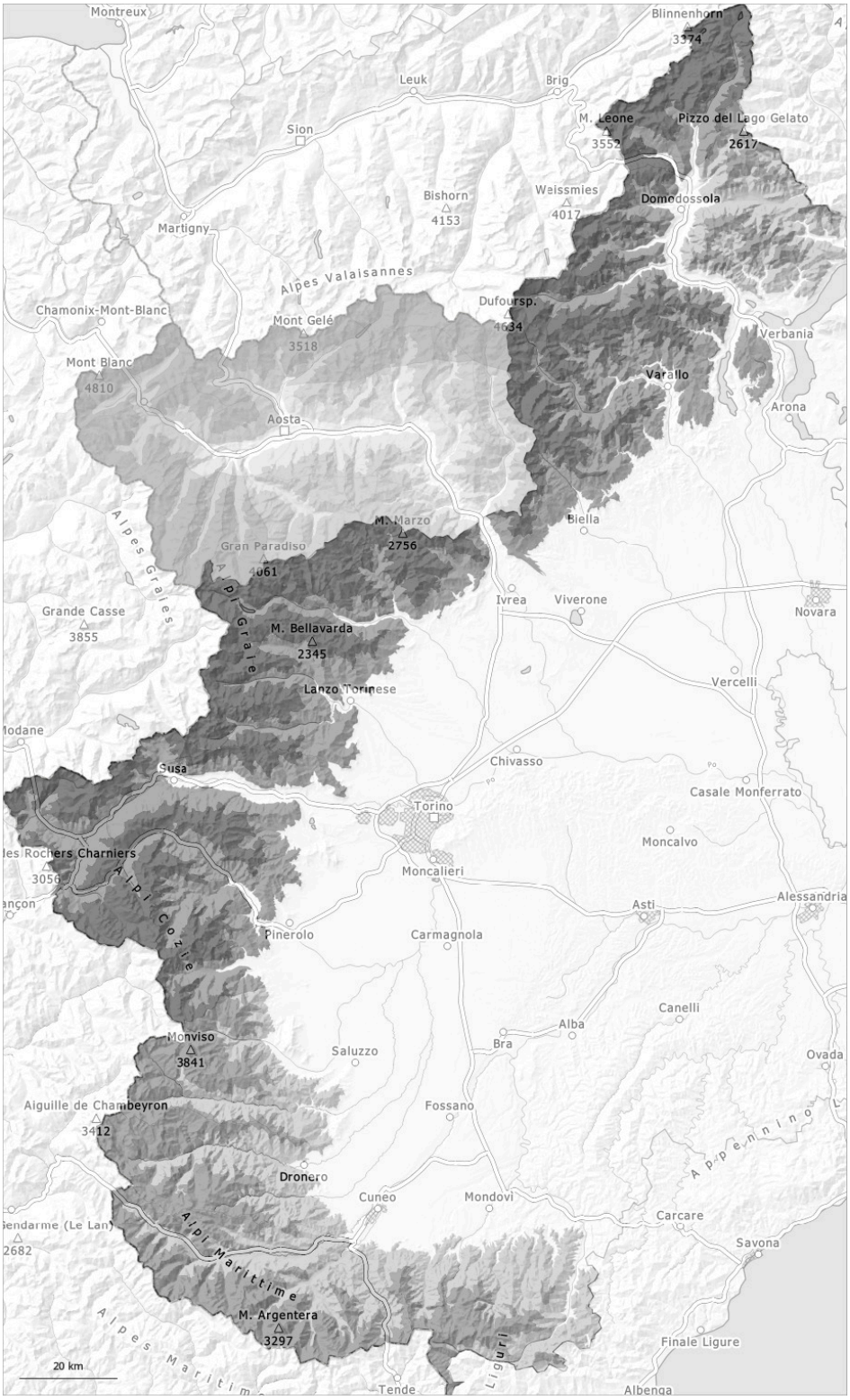


| 1 | 2 | 3 | 4 | 5 |
|---|---|---|---|---|
| faible | limité | marqué | fort | très fort |

## Degré de danger 4 - Fort

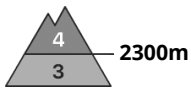


**Tendance: Diminution du danger d'avalanche**
leMardi 17 02 2026

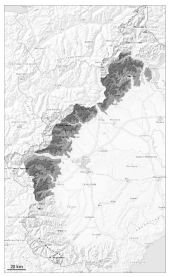

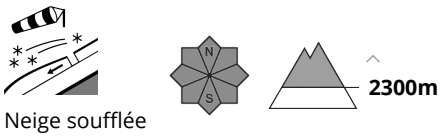


Neige soufflée
(Neige ventée)

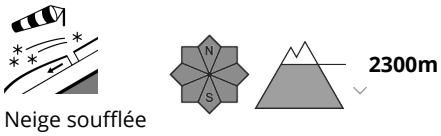


Neige soufflée
(Neige ventée)

## Augmentation progressive du danger d'avalanches avec la neige fraîche et le vent.

Jusqu'au soir il tombera en général au-dessus d'environ 1400 m de 10 à 25 cm de neige.
Le vent parfois fort transporte la neige fraîche et ancienne. Avec les chutes de neige et le vent de nord-ouest modéré à fort, de nouvelles accumulations de neige soufflée se forment en cours de journée. Celles-ci se forment surtout entre environ 2100 et 2500 m.
Les accumulations de neige soufflée fraîches et relativement anciennes peuvent déjà être déclenchées par un seul amateur de sports d'hiver au-dessus de la limite de la forêt.

Là où localement le vent souffle plus fort le degré de danger 4, "fort" sera atteint.

## Manteau neigeux

**Modèles de danger** md.6: froid, neige légère et vent

Le vent parfois fort transporte la neige fraîche et partiellement aussi la neige ancienne.
Surtout à proximité des sommets on trouve suivant l'influence du vent des hauteurs de neiges très différentes.

Dans le manteau neigeux ancien des couches fragiles sont présentes, surtout sur les pentes raides exposées au nord-ouest, au nord et à l'est.

## Degré de danger 4 - Fort

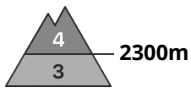


**Tendance: danger d'avalanche constant**
leMardi 17 02 2026

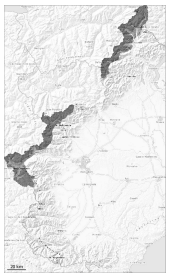

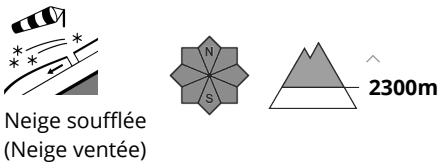


Neige soufflée
(Neige ventée)

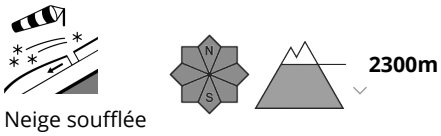


Neige soufflée
(Neige ventée)

### Augmentation progressive du danger d'avalanches avec la neige fraîche et la tempête.

Jusqu'au soir il tombera surtout le long de la frontière française, le long de la frontière entre le Valais et l'Italie au-dessus d'environ 1700 m de 25 à 40 cm de neige, localement jusqu'à 60 cm.

Avec les chutes de neige et le vent de nord-ouest parfois fort, de nouvelles accumulations de neige soufflée se forment en cours de journée. Le vent fort transporte la neige fraîche et partiellement aussi la neige ancienne.
Les accumulations de neige soufflée en partie grosses peuvent être déjà déclenchées facilement par un seul amateur de sports d'hiver au-dessus de la limite de la forêt.
Sur les pentes raides et dans les combes, couloirs et derrière les ruptures de terrain la situation avalancheuse est très délicate.

Des avalanches de plaque de neige de moyenne à grande taille sont possibles sur les versants où s'est accumulée la neige soufflée et à proximité des crêtes, de manière isolée aussi à partir des zones de départ raides et à haute altitude orientées sud-est et pas encore déchargées.

### Manteau neigeux

**Modèles de danger** md.6: froid, neige légère et vent

Le vent parfois tempétueux transporte la neige fraîche et ancienne de manière intensive.
Surtout à proximité des sommets on trouve suivant l'influence du vent des hauteurs de neiges très différentes.

Dans le manteau neigeux ancien des couches fragiles sont présentes, surtout sur les pentes raides exposées au nord-ouest, au nord et à l'est. Différentes couches de neige soufflée reposent par endroits sur du givre de surface.

## Degré de danger 3 - Marqué

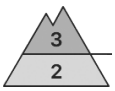


**Limite de la forêt**

**Tendance: danger d'avalanche constant**
leMardi 17 02 2026

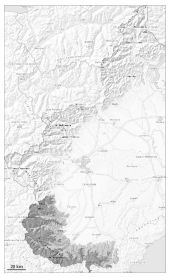

Neige soufflée
(Neige ventée)

**Limite de la forêt**

Avalanches
mouillées
(Neige
humide)

**1800m**

### Neige soufflée en haute montagne. Neige mouillée et glissante à basse altitude.

Des accumulations de neige soufflée se forment avec le vent de secteur nord-ouest modéré en altitude. Les accumulations de neige soufflée peuvent être déjà déclenchées par un seul amateur de sports d'hiver. Ceci surtout sur les pentes raides à l'ombre en haute montagne comme sur les versants où s'est accumulée la neige soufflée, aussi aux transitions vers les combes et couloirs dans les régions où le vent a beaucoup soufflé.

En outre, des avalanches peuvent de manière isolée se déclencher dans la neige ancienne et atteindre une grande taille.

Sur les pentes raides et à basse altitude jusqu'à midi des avalanches humides sont toujours possibles, mais celles-ci peuvent atteindre une taille moyenne partiellement.

### Manteau neigeux

**Modèles de danger** md.6: froid, neige légère et vent

En général des accumulations de neige soufflée dures se sont formées dans les derniers jours. Le vent parfois tempétueux a transporté intensivement la neige fraîche. À proximité des sommets on trouve suivant l'influence du vent des hauteurs de neiges très différentes.

Des accumulations de neige soufflée en général petites se forment avec le vent de secteur nord-ouest modéré.

Dans le manteau neigeux ancien des couches fragiles sont présentes, surtout sur les pentes raides exposées au nord-ouest, au nord et au nord-est.

> Le soleil et la chaleur ont entraîné à basse altitude une humidification du manteau neigeux ancien.

## Degré de danger 3 - Marqué

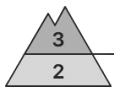


**Tendance: danger d'avalanche constant**
leMardi 17 02 2026

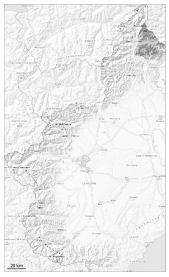

Neige soufflée
(Neige ventée)

Neige
ancienne
(Sous-couche
fragile
persistante)

### Avec la neige fraîche et le vent les endroits dangereux se multiplient.

Jusqu'au soir il tombera localement au-dessus d'environ 1000 m de 10 à 20 cm de neige.
Avec les chutes de neige et le vent modéré à fort, de nouvelles accumulations de neige soufflée se forment en cours de journée. Les anciennes accumulations de neige soufflée seront recouvertes de neige fraîche et donc difficilement identifiables.
Des accumulations récentes et déjà plus anciennes de neige soufflée peuvent être parfois déclenchées par un seul amateur de sports d'hiver.
Les endroits dangereux se situent spécialement dans les combes, couloirs et derrière les ruptures de terrain ainsi qu'aux transitions entre les endroits faiblement et fortement enneigés.

En outre, des avalanches peuvent de manière très isolée se déclencher dans la neige ancienne et atteindre une grande taille.

### Manteau neigeux

**Modèles de danger** md.6: froid, neige légère et vent

Dans le manteau neigeux ancien des couches fragiles sont présentes, surtout sur les pentes raides exposées à l'ouest, au nord et à l'est.