Lunedì 16.02.2026

Pubblicato il 15.02.2026 alle ore 17:00

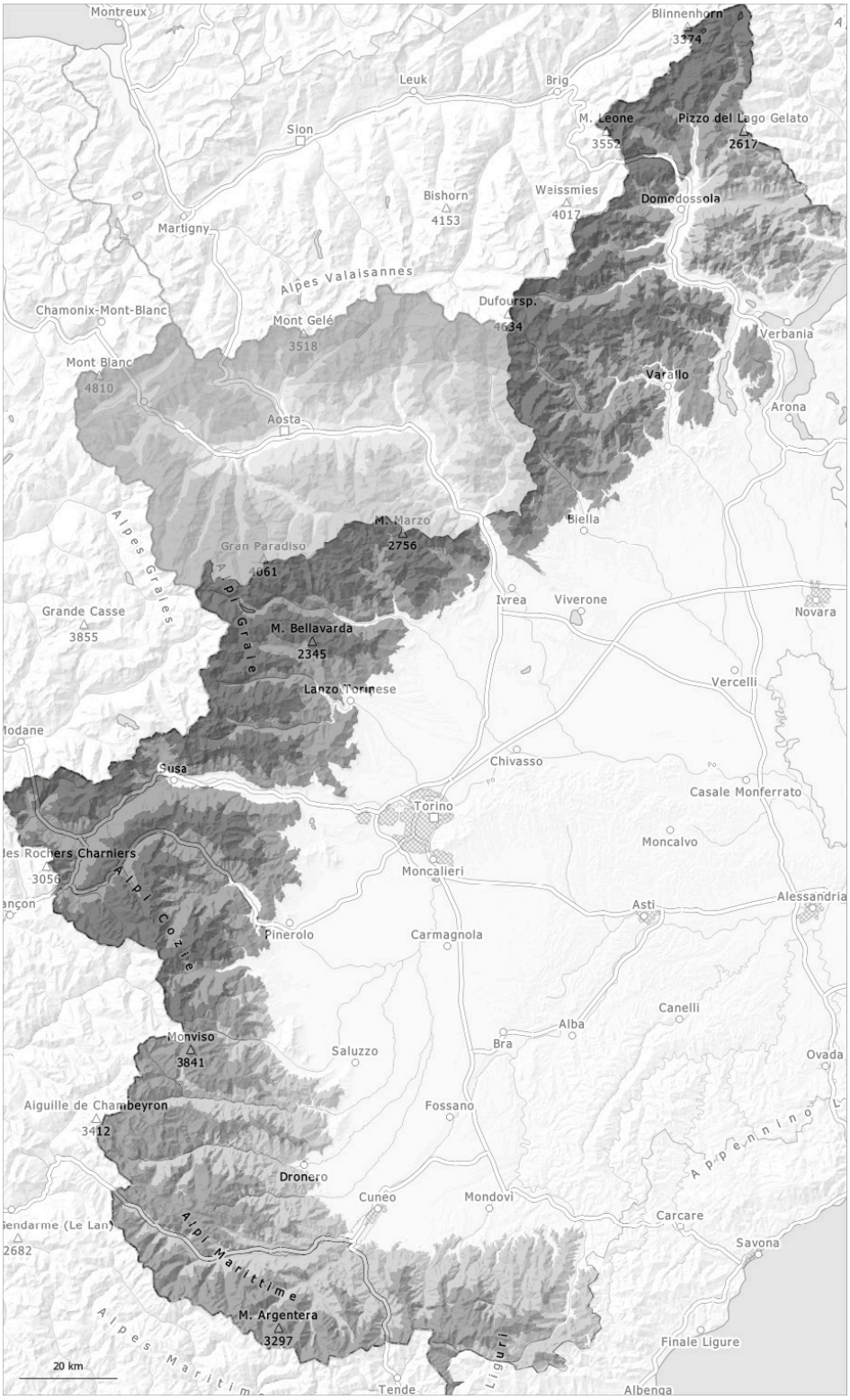

1	2	3	4	5
debole	moderato	marcato	forte	molto forte

Grado di pericolo 4 - Forte

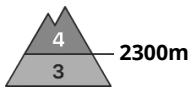

Tendenza: pericolo valanghe in diminuzione
per Martedì il 17.02.2026

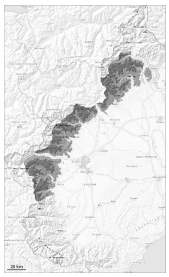

Lastrone da vento

2300m

Lastrone da vento

2300m

Con neve fresca e vento, progressivo aumento del pericolo di valanghe.

In molte regioni fino a sera cadranno da 10 a 25 cm di neve al di sopra dei 1400 m circa.
Il vento a tratti forte causerà il trasporto della neve fresca e della neve vecchia. Con le nevicate e il vento da moderato a forte proveniente da nord ovest, nel corso della giornata si formeranno nuovi accumuli di neve ventata. Questi ultimi si formeranno soprattutto tra i 2100 e i 2500 m circa.
Gli accumuli di neve ventata nuovi e meno recenti possono subire un distacco già in seguito al passaggio di un singolo appassionato di sport invernali al di sopra del limite del bosco.

Laddove a livello locale i venti saranno più forti, verrà raggiunto il grado di pericolo 4 "forte".

Manto nevoso

Situazione tipo st.6: neve a debole coesione e vento

Il vento a tratti forte causerà il trasporto della neve fresca e, in parte, anche della neve vecchia. Specialmente in prossimità delle cime l'innevamento è estremamente variabile a seconda dell'azione del vento.

Soprattutto sui pendii ripidi esposti a nord ovest, nord ed est, all'interno del manto di neve vecchia si trovano strati fragili.

Grado di pericolo 4 - Forte

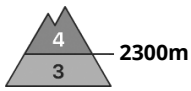

Tendenza: pericolo valanghe stabile
per Martedì il 17.02.2026

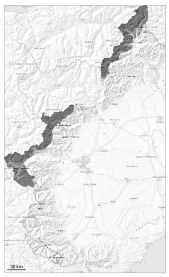

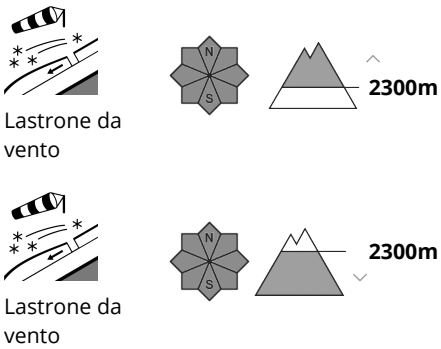

Con neve fresca e venti tempestosi, progressivo aumento del pericolo di valanghe.

Specialmente lungo il confine con la Francia, lungo il confine tra il Vallese e l'Italia fino a sera cadranno da 25 a 40 cm di neve al di sopra dei 1700 m circa, localmente sino a 60 cm.

Con le nevicate e il vento a tratti forte proveniente da nord ovest, nel corso della giornata si formeranno nuovi accumuli di neve ventata. Il forte vento causerà il trasporto della neve fresca e, in parte, anche della neve vecchia.
Gli accumuli di neve ventata in parte di grandi dimensioni possono facilmente subire un distacco già in seguito al passaggio di un singolo appassionato di sport invernali al di sopra del limite del bosco.
Sui pendii ripidi così come nelle conche, nei canaloni e dietro ai cambi di pendenza la situazione valanghiva è molto delicata.

Sui pendii carichi di neve ventata e nelle zone in prossimità delle creste sono possibili valanghe di neve a lastroni di dimensioni medio-grandi, a livello isolato anche dai bacini di alimentazione ripidi e situati ad alta quota esposti a sud est e non ancora scaricati.

Manto nevoso

Situazione tipo st.6: neve a debole coesione e vento

Il vento a tratti tempestoso rimaneggerà intensamente la neve fresca e la neve vecchia.
Specialmente in prossimità delle cime l'innevamento è estremamente variabile a seconda dell'azione del vento.

Soprattutto sui pendii ripidi esposti a nord ovest, nord ed est, all'interno del manto di neve vecchia si trovano strati fragili. In alcuni punti diversi strati di neve ventata poggiano su brina superficiale.

Grado di pericolo 3 - Marcato

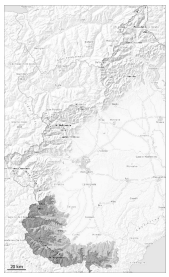

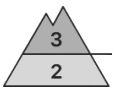

Limite del bosco

Tendenza: pericolo valanghe stabile
per Martedì il 17.02.2026

Lastrone da vento

Limite del bosco

Neve bagnata

1800m

Neve ventata in alta montagna. Neve bagnata e neve slittante a bassa quota.

Con vento moderato proveniente dai quadranti nord occidentali in quota si formeranno accumuli di neve ventata.
Gli accumuli di neve ventata possono distaccarsi già in seguito al passaggio di un singolo appassionato di sport invernali. Ciò soprattutto sui pendii ombreggiati ripidi in alta montagna, come pure sui pendii carichi di neve ventata, anche nei passaggi che conducono a conche e canaloni nelle regioni con molto vento.

Isolate valanghe possono anche coinvolgere il manto di neve vecchia e raggiungere grandi dimensioni.

Sui pendii ripidi e a bassa quota, sino a mezzogiorno sono ancora possibili valanghe umide, che in alcuni punti possono raggiungere dimensioni medie.

Manto nevoso

Situazione tipo st.6: neve a debole coesione e vento

Negli ultimi giorni in molti punti si sono formati accumuli di neve ventata duri. Il vento a tratti tempestoso ha rimaneggiato intensamente la neve fresca. In prossimità delle cime l'innevamento è estremamente variabile a seconda dell'azione del vento.

Con vento moderato proveniente dai quadranti nord occidentali si formeranno accumuli di neve ventata per lo più di piccole dimensioni.

Soprattutto sui pendii ripidi esposti a nord ovest, nord e nord est, all'interno del manto di neve vecchia si trovano strati fragili.

Il sole e il calore hanno causato a bassa quota un inumidimento del manto di neve vecchia.

Grado di pericolo 3 - Marcato

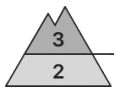

Tendenza: pericolo valanghe stabile
per Martedì il 17.02.2026

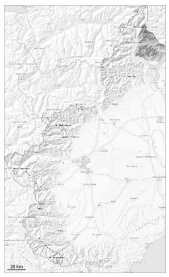

Lastrone da vento

Strati deboli persistenti

Con neve fresca e vento, i punti pericolosi aumenteranno.

A livello locale fino a sera cadranno da 10 a 20 cm di neve al di sopra dei 1000 m circa.
Con le nevicate e il vento da moderato a forte, nel corso della giornata si formeranno nuovi accumuli di neve ventata. I vecchi accumuli di neve ventata verranno innevati e saranno quindi difficilmente individuabili.
I nuovi accumuli di neve ventata e quelli meno recenti possono in parte subire un distacco in seguito al passaggio di un singolo appassionato di sport invernali.
I punti pericolosi si trovano principalmente nelle conche, nei canaloni e dietro ai cambi di pendenza come pure nelle zone di passaggio da poca a molta neve.

A livello molto isolato, le valanghe possono anche coinvolgere il manto di neve vecchia e raggiungere grandi dimensioni.

Manto nevoso

Situazione tipo st.6: neve a debole coesione e vento

Specialmente sui pendii ripidi esposti a ovest, nord ed est, all'interno del manto di neve vecchia si trovano strati fragili.