Lunedì 16.02.2026

Pubblicato il 15.02.2026 alle ore 17:00

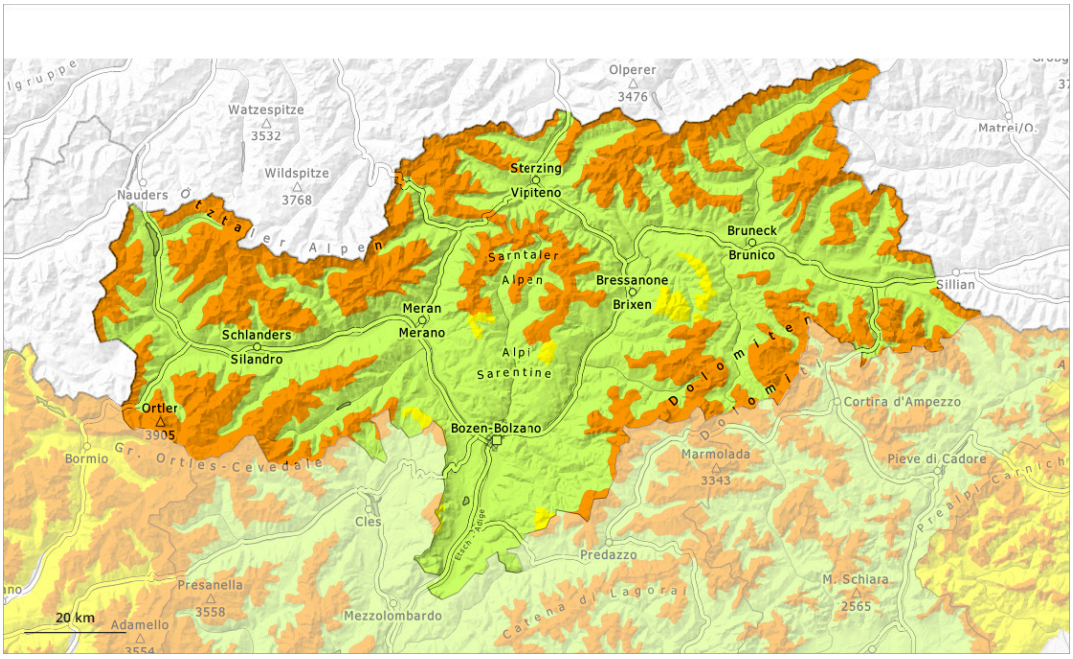

1	2	3	4	5
debole	moderato	marcato	forte	molto forte

Grado di pericolo 3 - Marcato

Limite del bosco

Tendenza: pericolo valanghe in aumento
per Martedì il 17.02.2026

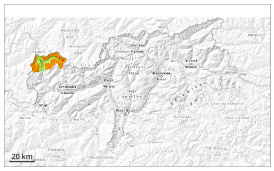

Strati deboli persistenti

Limite del bosco

Lastrone da vento

Limite del bosco

Le condizioni al di fuori delle piste sono pericolose. Attenzione alla neve ventata e alla neve vecchia con strati deboli persistenti.

La neve fresca e gli accumuli di neve ventata che si formeranno con il vento proveniente da ovest di forte intensità possono subire molto facilmente un distacco provocato. I punti pericolosi si trovano specialmente nelle conche, nei canaloni e dietro ai cambi di pendenza al di sopra del limite del bosco. Isolati punti pericolosi si trovano anche in prossimità del limite del bosco.
In alcuni punti, le valanghe possono anche distaccarsi coinvolgendo gli strati basali del manto e raggiungere grandi dimensioni a livello isolato, principalmente sui pendii esposti a ovest, nord ed est. Questi punti sono difficili da individuare. I rumori di "whum" e la formazione di fessure quando si calpesta la coltre di neve così come nuove valanghe sono campanelli di allarme che rimandano a questo pericolo. Sono possibili distacchi a distanza.

Con le nevicate, nel corso della giornata i punti pericolosi aumenteranno. Sono previste isolate valanghe spontanee.

Con la pioggia, alle quote di bassa e media montagna sono previste scaricamenti di neve bagnata a debole coesione di piccole dimensioni, specialmente sulle scarpate e sui pendii erbosi molto ripidi.

Manto nevoso

Situazione tipo st.1: strato debole persistente basale | st.8: brina di superficie sepolta

Lunedì cadranno diffusamente da 15 a 25 cm di neve, localmente anche di più. Con vento forte proveniente dai quadranti nord occidentali si formeranno accumuli di neve ventata instabili. Gli accumuli di neve ventata meno recenti poggiano in parte su brina di superficie.

La neve fresca e gli accumuli di neve ventata verranno depositati su un debole manto di neve vecchia soprattutto sui pendii esposti a ovest, nord ed est al di sopra del limite del bosco. Nella parte basale del

manto nevoso si trovano strati fragili a cristalli sfaccettati. I test di stabilità e le segnalazioni degli osservatori confermano la debole struttura del manto nevoso.

Tendenza

Con neve fresca e vento, ulteriore aumento del pericolo di valanghe.
Gli strati deboli presenti nella neve vecchia rappresentano la principale fonte di pericolo. Sono previste valanghe spontanee.

Grado di pericolo 3 - Marcato

Limite del bosco

Tendenza: pericolo valanghe stabile
per Martedì il 17.02.2026

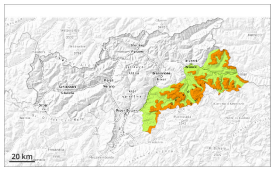

Strati deboli persistenti

Limite del bosco

Lastrone da vento

Limite del bosco

Attenzione alla neve ventata e alla neve vecchia con strati deboli persistenti.

Principalmente nelle zone poco frequentate, gli strati deboli molto pronunciati presenti nella neve vecchia possono distaccarsi facilmente in seguito al passaggio di un singolo appassionato di sport invernali. Sono possibili distacchi a distanza. I pendii ombreggiati ripidi e poco frequentati dovrebbero essere possibilmente evitati. Le valanghe sono per lo più di dimensioni medie. Attenzione soprattutto sui pendii ripidi esposti a ovest, nord ed est al di sopra del limite del bosco. I punti pericolosi sono difficili da individuare. I rumori di "whum" e la formazione di fessure quando si calpesta la coltre di neve così come nuove valanghe sono campanelli di allarme che rimandano a questo pericolo.

I nuovi accumuli di neve ventata e quelli meno recenti sono instabili, principalmente nelle conche, nei canaloni e dietro ai cambi di pendenza al di sopra del limite del bosco. Essi sono ben individuabili dall'escursionista esperto.

È consigliata prudenza.

Manto nevoso

Situazione tipo st.1: strato debole persistente basale | st.8: brina di superficie sepolta

Cadrà un po' di neve. Con vento forte proveniente dai quadranti nord occidentali principalmente nelle conche e nei canaloni si formeranno accumuli di neve ventata instabili. Gli accumuli di neve ventata meno recenti poggiano in parte su brina di superficie.

Al di sopra del limite del bosco: Il manto nevoso è instabile. All'interno del manto di neve vecchia si trovano pronunciati strati fragili. Ciò soprattutto sui pendii esposti a ovest, nord ed est.

Tendenza

Gli strati deboli presenti nella neve vecchia rappresentano la principale fonte di pericolo. È opportuna

> prudenza.
>
> Cadrà un po' di neve.

Grado di pericolo 3 - Marcato

Limite del bosco

Tendenza: pericolo valanghe stabile
per Martedì il 17.02.2026

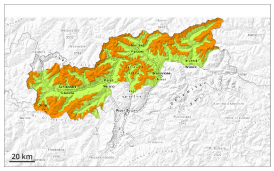

Strati deboli persistenti

Limite del bosco

Lastrone da vento

Limite del bosco

Le condizioni al di fuori delle piste sono sfavorevoli. Attenzione alla neve ventata e alla neve vecchia con strati deboli persistenti.

Principalmente nelle zone poco frequentate, gli strati deboli molto pronunciati presenti nella neve vecchia possono distaccarsi facilmente in seguito al passaggio di un singolo appassionato di sport invernali. Attenzione soprattutto sui pendii ripidi esposti a ovest, nord ed est al di sopra del limite del bosco. I punti pericolosi sono difficili da individuare. I rumori di "whum" e la formazione di fessure quando si calpesta la coltre di neve così come nuove valanghe sono campanelli di allarme che rimandano a questo pericolo. Sono possibili distacchi a distanza. Le valanghe sono per lo più di dimensioni medie.

Con neve fresca e vento forte proveniente da nord ovest soprattutto al di sopra del limite del bosco si formeranno accumuli di neve ventata facilmente distaccabili, principalmente nelle conche, nei canaloni e dietro ai cambi di pendenza. Sono previste isolate valanghe spontanee.

È consigliata prudenza.

Manto nevoso

Situazione tipo st.1: strato debole persistente basale | st.8: brina di superficie sepolta

Lunedì cadranno diffusamente da 10 a 20 cm di neve. Con vento forte proveniente dai quadranti nord occidentali principalmente nelle conche, nei canaloni e dietro ai cambi di pendenza si formeranno accumuli di neve ventata instabili. Gli accumuli di neve ventata meno recenti poggiano in parte su brina di superficie. All'interno del manto di neve vecchia si trovano pronunciati strati fragili. Ciò soprattutto sui pendii esposti a ovest, nord ed est al di sopra del limite del bosco.

Tendenza

Gli strati deboli presenti nella neve vecchia rappresentano la principale fonte di pericolo. È opportuna prudenza.

Con neve fresca e vento, in alcune aree aumento del pericolo di valanghe. Ciò soprattutto nelle aree settentrionali e nelle aree occidentali.

Grado di pericolo 2 - Moderato

Limite del bosco

Tendenza: pericolo valanghe stabile
per Martedì il 17.02.2026

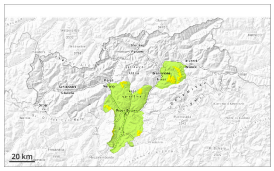

Strati deboli persistenti

Limite del bosco

Lastrone da vento

Limite del bosco

La neve ventata e la neve vecchia con strati deboli persistenti richiedono attenzione.

Le valanghe possono distaccarsi in seguito al passaggio di un singolo appassionato di sport invernali. Ciò specialmente sui pendii ombreggiati ripidi nelle zone in prossimità delle creste, nelle conche e nei canaloni al di sopra del limite del bosco.
Con il vento a tratti forte proveniente da nord, si formeranno nuovi accumuli di neve ventata. Questi ultimi sono in parte instabili. Le valanghe sono in parte di dimensioni medie.

Le escursioni richiedono attenzione e prudenza. È presente poca neve rispetto alla media stagionale.

Manto nevoso

Situazione tipo st.6: neve a debole coesione e vento

Cadrà un po' di neve. All'interno del manto di neve vecchia si trovano strati fragili a cristalli sfaccettati. Gli accumuli di neve ventata nuovi e meno recenti poggiano su una sfavorevole superficie del manto di neve vecchia in quota.

Alle quote di bassa e media montagna: Il manto nevoso è umido, con una crosta da rigelo a malapena portante in superficie.

Tendenza

Moderato pericolo di valanghe.