ICGC Institut Cartogràfic i Geològic de Catalunya

Servei Meteorològic de Catalunya meteo.cat

Boletín de peligro de aludes para el Pirineo de Catalunya
Del 15/02/2026 al 16/02/2026

(Válido fuera pistas de esquí y zonas no controladas)

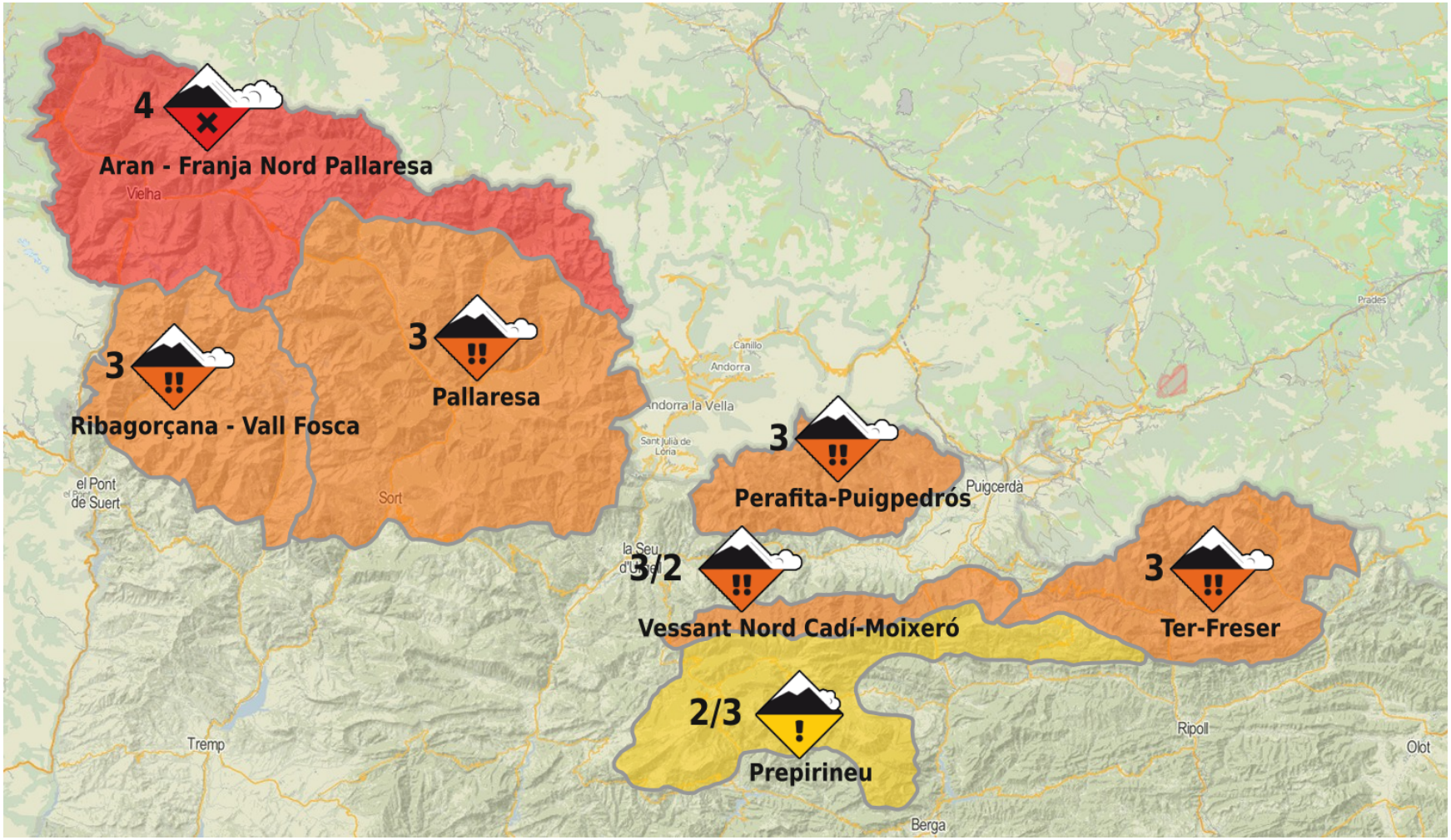

5 MUY FUERTE	4 FUERTE	3 NOTABLE	2 LIMITADO	1 DÉBIL

ICGC Institut Cartogràfic i Geològic de Catalunya

Servei Meteorològic de Catalunya meteo.cat

Boletín de peligro de aludes Aran - Franja Nord Pallaresa Del 15/02/2026 al 16/02/2026

(Válido fuera pistas de esquí y zonas no controladas)

FUERTE (4).

Situación primaria

Nieve venteada

Distribución

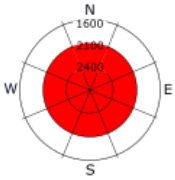

Tamaño

Origen

Tendencia

Situación secundaria

Nieve húmeda

Distribución

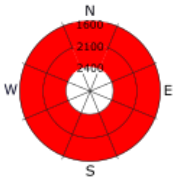

Tamaño

Origen

Tendencia

Estado del manto nivoso

La nevada del fin de semana ha acumulado hasta 60 cm, con fuerte viento del N. Ha habido numerosa actividad, con la caída natural y accidental de placas de viento, de tamaño medio y grande. Los problemas predominantes serán las placas de viento y los aludes de nieve húmeda, con las lloviznas previstas hasta la cota 2.000. El lunes, las placas continuarán muy frágiles y podrán caer de forma natural o al paso de un esquiador y generar aludes de gran tamaño (con capacidad de enterrar a un grupo de personas). Se podrán desencadenar a distancia debido a niveles débiles bajo la nieve venteada (nieve granulada y facetas). Las placas caerán en cualquier orientación, incluso por debajo del límite del bosque. Además, con el húmedo progresivo del manto, se esperan también aludes de nieve húmeda y de deslizamiento basal que podrán llegar hasta tamaño medio o grande (con capacidad para enterrar uno o más montañeros). Las condiciones serán peligrosas y se recomienda no circular por terreno de alud.

Distribución del manto nivoso

Hay nieve en el suelo a 1.400 m en Norte. El manto es esquiable por encima de unos 1.500 m en umbrías. Los espesores a unos 2.200 m son superiores a los normales y rondan los 120-140 cm en el norte de Arán y los 160-200 cm en la Franja Norte Pallaresa y en el sur de Aran.

Tendencia para las próximas 48-72h

Se esperan nuevas nevadas y viento, con cota de nieve entre 1600 y 1800 m. Peligro ESTACIONARIO.

El próximo boletín será emitido el día 2026-02-16

5 MUY FUERTE	4 FUERTE	3 NOTABLE	2 LIMITADO	1 DÉBIL

EAWS EUROPEAN AVALANCHE WARNING SERVICES

ICGC Institut Cartogràfic i Geològic de Catalunya

Servei Meteorològic de Catalunya

Boletín de peligro de aludes Ribagorçana - Vall Fosca Del 15/02/2026 al 16/02/2026

(Válido fuera pistas de esquí y zonas no controladas)

NOTABLE (3).

Situación primaria

Nieve venteada

Distribución

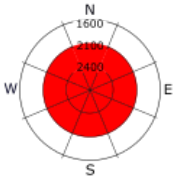

Tamaño

Origen

Tendencia

Situación secundaria

Nieve húmeda

Distribución

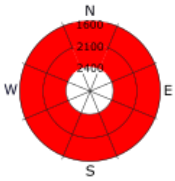

Tamaño

Origen

Tendencia

Estado del manto nivoso

La nevada con el fuerte viento del noroeste ha transportado la nieve a las laderas a sotavento. Para el lunes, el problema predominante será el de las placas de viento. Encontraremos nuevas placas, muy frágiles y podrán caer de forma natural o al paso de un esquiador y generar aludes de tamaño medio (con capacidad de enterrar a una persona). Los lugares donde se formarán serán en cualquier orientación, sobre todo, en Sur, Este y en Norte, por encima del límite del bosque, bajo collados y cordales y en terreno con convexidades. Las placas de viento se mantendrán muy frágiles. En las vertientes muy inclinadas, con el húmedo progresivo del manto y con las lloviznas previstas, podrán caer purgas de nieve húmeda, de pequeño tamaño y también medio. Se recomienda mucha prudencia y experiencia si debe circularse por zonas no controladas.

Distribución del manto nivoso

Hay nieve en el suelo a 1.500 m. El manto es esquiable por encima de unos 1500-1600 m. Los grosores alcanzan los 130-160 cm. Estos valores son muy superiores a los normales en la época.

Tendencia para las próximas 48-72h

Se mantendrá el viento en cota alta y caerán nuevos nevadas. Las placas se mantendrán reactivas. Peligro ESTACIONARIO.

El próximo boletín será emitido el día 2026-02-16

5 MUY FUERTE	4 FUERTE	3 NOTABLE	2 LIMITADO	1 DÉBIL

EAWS EUROPEAN AVALANCHE WARNING SERVICES

ICGC Institut Cartogràfic i Geològic de Catalunya

Servei Meteorològic de Catalunya

Boletín de peligro de aludes Pallaresa
Del 15/02/2026 al 16/02/2026

(Válido fuera pistas de esquí y zonas no controladas)

NOTABLE (3).

Situación primaria

Nieve venteada

Distribución

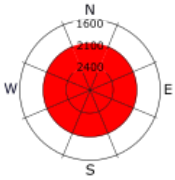

Tamaño

Origen

Tendencia

Situación secundaria

Nieve húmeda

Distribución

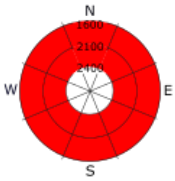

Tamaño

Origen

Tendencia

Estado del manto nivoso

La nevada con el fuerte viento del noroeste ha transportado la nieve a las laderas a sotavento. Para el lunes, el problema predominante será el de las placas de viento. Encontraremos nuevas placas, muy frágiles y podrán caer de forma natural o al paso de un esquiador y generar aludes de tamaño medio (con capacidad de enterrar a una persona). Los lugares donde se formarán serán en cualquier orientación, sobre todo, en Sur, Este y en Norte, por encima del límite del bosque, bajo collados y cordales y en terreno con convexidades. Las placas de viento se mantendrán muy frágiles. En las vertientes muy inclinadas, con el húmedo progresivo del manto y con las lloviznas previstas, podrán caer purgas de nieve húmeda, de pequeño tamaño y también medio. Se recomienda mucha prudencia y experiencia si debe circularse por zonas no controladas.

Distribución del manto nivoso

Hay nieve en el suelo a 1.500 m. El manto es esquiable por encima de unos 1500-1600 m. Los grosores alcanzan los 130-160 cm. Estos valores son muy superiores a los normales en la época.

Tendencia para las próximas 48-72h

Se mantendrá el viento en cota alta y caerán nuevas nevadas. Las placas se mantendrán reactivas. Peligro ESTACIONARIO.

El próximo boletín será emitido el día 2026-02-16

5 MUY FUERTE	4 FUERTE	3 NOTABLE	2 LIMITADO	1 DÉBIL

EAWS EUROPEAN AVALANCHE WARNING SERVICES

ICGC Institut Cartogràfic i Geològic de Catalunya

meteo.cat Servei Meteorològic de Catalunya

Boletín de peligro de aludes Perafita-Puigpedrós Del 15/02/2026 al 16/02/2026

(Válido fuera pistas de esquí y zonas no controladas)

NOTABLE (3).

Situación primaria

Nieve venteada

Distribución

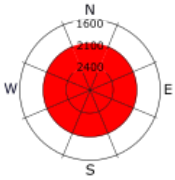

Tamaño

Origen

Tendencia

Situación secundaria

Nieve húmeda

Distribución

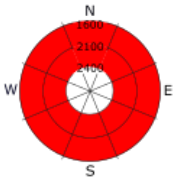

Tamaño

Origen

Tendencia

Estado del manto nivoso

La nevada con el fuerte viento del noroeste ha transportado la nieve a las laderas a sotavento. Para el lunes, el problema predominante será el de las placas de viento. Encontraremos nuevas placas, muy frágiles y podrán caer de forma natural o al paso de un esquiador y generar aludes de tamaño medio (con capacidad de enterrar a una persona). Los lugares donde las encontraremos serán en cualquier orientación, sobre todo, en Sur, Este y en Norte, por encima del límite del bosque, bajo collados y cordales y en terreno con convexidades. Las placas de viento se mantendrán muy frágiles. En las vertientes muy inclinadas, con el húmedo progresivo del manto y con las lloviznas previstas, podrán caer purgas de nieve húmeda, de pequeño tamaño y también medio. Se recomienda mucha prudencia y experiencia si debe circularse por zonas no controladas.

Distribución del manto nivoso

Hay nieve en el suelo por encima de 1.400-1500 m. Sin embargo, el manto es esquiable por encima de 1.500-1.600 m. Los grosores alcanzan los 130-150 cm a 2.200 m. Son grosores muy por encima de los habituales por la época.

Tendencia para las próximas 48-72h

Se mantendrá el viento en cota alta y caerán nuevos chubascos de nieve. Las placas se mantendrán reactivas. Peligro ESTACIONARIO.

El próximo boletín será emitido el día 2026-02-16

5 MUY FUERTE	4 FUERTE	3 NOTABLE	2 LIMITADO	1 DÉBIL

EAWS EUROPEAN AVALANCHE WARNING SERVICES

ICGC Institut Cartogràfic i Geològic de Catalunya

Servei Meteorològic de Catalunya meteo.cat

Boletín de peligro de aludes Vessant Nord Cadí-Moixeró Del 15/02/2026 al 16/02/2026

(Válido fuera pistas de esquí y zonas no controladas)

NOTABLE (3), por encima del límite del bosque. LIMITADO (2), en el resto.

Situación primaria

Nieve venteada

Distribución

Tamaño

Origen

Tendencia

Situación secundaria

Nieve húmeda

Distribución

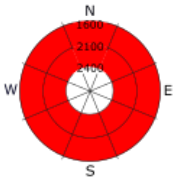

Tamaño

Origen

Tendencia

Estado del manto nivoso

Durante el fin de semana ha nevado unos 10 cm con viento moderado del Sur y posteriormente del Noroeste. En cota alta se habrán formado placas, a sotavento del viento predominante. El problema principal será, por tanto, el de las placas de viento, que las encontraremos en vertientes Este, Norte y Sur. Si se rompen las placas, al paso de un montañero, podrán generar aludes de pequeño tamaño, sin capacidad para enterrar a una persona y allí donde haya más acumulación, podrá caer algún alud de tamaño medio (que podría enterrar a un montañero), sobre todo en terreno trampa. Habrá que ir con copto en lo alto de las Canales del Cadí, donde podremos encontrar alguna nueva placa. Con el humedecimiento del manto, con el ascenso térmico, la nubosidad y alguna llovizna, podrá caer alguna purga de nieve húmeda en terreno inclinado. Se recomienda mucha prudencia y experiencia si se debe circular por zonas no controladas, especialmente debajo de collados, cordales o en la salida de las Canales.

Distribución del manto nivoso

Hay nieve desde 1.300 m. Norte y desde 1.400 a 1500 m. Sur, esquiable por encima de unos 1.500 m. Los grosores están alrededor de 150-170 cm a 2.200 m. Estos valores son muy excedentarios para la época del año.

Tendencia para las próximas 48-72h

Se mantendrá el viento en cota alta y caerán nuevos chubascos de nieve. Las placas se mantendrán reactivas. Peligro ESTACIONARIO.

El próximo boletín será emitido el día 2026-02-16

5 MUY FUERTE	4 FUERTE	3 NOTABLE	2 LIMITADO	1 DÉBIL

EAWS EUROPEAN AVALANCHE WARNING SERVICES

ICGC Institut Cartogràfic i Geològic de Catalunya

meteo.cat Servei Meteorològic de Catalunya

Boletín de peligro de aludes Prepirineu
Del 15/02/2026 al 16/02/2026

(Válido fuera pistas de esquí y zonas no controladas)

LIMITADO (2), por debajo del límite del bosque. NOTABLE (3), en el resto.

Situación primaria

Nieve venteada

Distribución

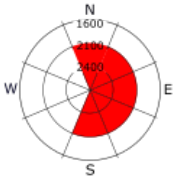

Tamaño

Origen

Tendencia

Situación secundaria

Nieve húmeda

Distribución

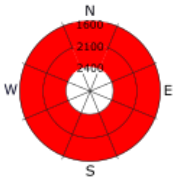

Tamaño

Origen

Tendencia

Estado del manto nivoso

Durante el fin de semana ha nevado (10 cm) con viento fuerte del Oeste y del Noroeste. En cota alta se han formado placas, a sotavento del viento predominante. El problema principal será, por tanto, el de las placas de viento, que las encontraremos por encima del límite del bosque, en laderas orientadas a Este, Nordeste, Sur y Sudeste. Si se rompen las placas, al paso de un montañero, podrán generar aludes de pequeño tamaño, sin capacidad para enterrar a una persona y allí donde haya más acumulación, podrá caer algún alud de tamaño medio (que podría enterrar a un montañero), sobre todo en terreno trampa. Se recomienda mucha prudencia y experiencia si debe circularse por zonas no controladas.

Distribución del manto nivoso

Hay nieve desde 1400-1500 m. El manto es esquiable a partir de 1600 m. Los grosores están alrededor de 110-130 cm a unos 2.200 my son superiores a los habituales.

Tendencia para las próximas 48-72h

Se mantendrá el viento en cota alta y caerán nuevos chubascos de nieve. Las placas se mantendrán reactivas. Peligro ESTACIONARIO.

El próximo boletín será emitido el día 2026-02-16

5 MUY FUERTE	4 FUERTE	3 NOTABLE	2 LIMITADO	1 DÉBIL

EAWS EUROPEAN AVALANCHE WARNING SERVICES

ICGC Institut Cartogràfic i Geològic de Catalunya

Servei Meteorològic de Catalunya meteo.cat

Boletín de peligro de aludes Ter-Freser
Del 15/02/2026 al 16/02/2026

(Válido fuera pistas de esquí y zonas no controladas)

NOTABLE (3).

Situación primaria

Nieve venteada

Distribución

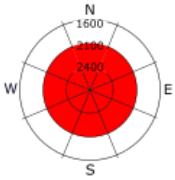

Tamaño

Origen

Tendencia

Situación secundaria

Nieve húmeda

Distribución

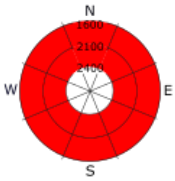

Tamaño

Origen

Tendencia

Estado del manto nivoso

El fuerte viento del noroeste ha transportado la nieve seca de la última nevada, generando nuevas placas. Por el lunes continuaremos con el problema de las placas de viento. Las encontraremos a sotavento del viento predominante del Norte y serán muy frágiles. Podrán caer de forma natural o al paso de un esquiador y generar aludes de hasta tamaño medio (con capacidad de enterrar a una persona). Los lugares donde se formarán serán en cualquier orientación, pero sobre todo, en Sur y Este, por encima del límite del bosque, bajo collados y cordales y en terreno con convexidades. En las vertientes muy inclinadas, con el humedecimiento progresivo del manto y con las lloviznas previstas hasta 2.000 m podrán caer purgas de nieve húmeda, de pequeño tamaño y también medio. Las condiciones serán delicadas, con ventisca en altura. Se recomienda mucha prudencia y experiencia si debe circularse por zonas no controladas.

Distribución del manto nivoso

El manto nivoso presenta grosores muy excedentarios para la época del año. En lugares no afectados por el viento, los espesores oscilan entre 100-140 cm a unos 2.000 m, siendo esquiable a partir de unos 1.500 m.

Tendencia para las próximas 48-72h

Se mantendrá el viento en cota alta y caerán nuevos chubascos de nieve. Las placas se mantendrán reactivas. Peligro ESTACIONARIO.

El próximo boletín será emitido el día 2026-02-16

5 MUY FUERTE	4 FUERTE	3 NOTABLE	2 LIMITADO	1 DÉBIL

EAWS EUROPEAN AVALANCHE WARNING SERVICES