MINISTERO DELLA DIFESA

meteomont
Servizio Nazionale di previsione neve e valanghe

EAWS EUROPEAN AVALANCHE WARNING SERVICES

CARABINIERI

ALPI RETICHE

Bollettino Valanghe N. 347/2026 del 14/02/2026 ore 14.00
Validità 48 ore prossima emissione 15/02/2026

A cura del Servizio METEOMONT dell'ARMA dei CARABINIERI
In collaborazione con Servizio Meteorologico dell'Aeronautica militare

SITUAZIONE alle 14:00 del 14/02/2026

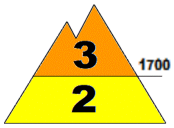

SITUAZIONE TIPO: strato debole persistente basale.



SITUAZIONE TIPO: pioggia su neve.

Quota neve (mslm)	Nord	Sud
	900 - 1300	1400 - 1500

Altezza Neve (cm)	Neve al suolo	Neve Fresca	Quota (mslm)
	45-60	4	2300
	36	2	1580

VALANGHE OSSERVATE: Nessuna valanga.

PREVISIONI 15/02/2026

GRADO DI PERICOLO: MARCATO 3

SITUAZIONE TIPO: strato debole persistente basale.

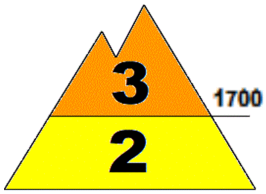

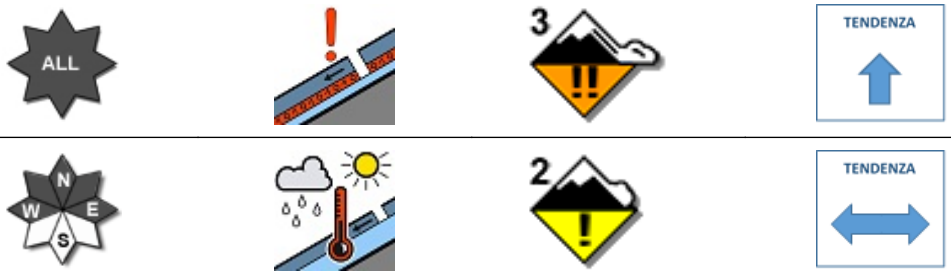

SITUAZIONE TIPO: situazione primaverile.

MANTO NEVOSO: La stabilità del manto nevoso è scarsa su molti punti (aree) per tutte le esposizioni al di sopra di 1700 mslm, possibili valanghe di dimensioni medie.
La stabilità del manto nevoso è molto scarsa su alcuni punti (aree) per versanti da ovest a est al di sotto di 1700 mslm, possibili valanghe di dimensioni piccole.

AVVERTENZE

A seguito dell'attività eolica prevista sono da evitare le zone di accumulo, conche, canaloni, cambi di pendenza e pendii sotto vento in genere.

SCALA EUROPEA DEL GRADO DI PERICOLO VALANGHE

LEGENDA PROBLEMA

Bollettino realizzato su scala sinottica-regionale (standard EAWS). La sua valutazione non può escludere in alcun modo la necessità di una seria e capace valutazione locale del pericolo (singolo pendio) che può essere anche sensibilmente diverso. Le previsioni meteorologiche sono relative all'orario UTC (per l'Italia +1 in inverno e +2 in estate).

MINISTERO DELLA DIFESA

meteomont
Servizio Nazionale di previsione neve e valanghe

EAWS EUROPEAN AVALANCHE WARNING SERVICES

CARABINIERI

ALPI RETICHE

PREVISIONE METEO

Quota		15/02/2026 h6:00	15/02/2026 h12:00	15/02/2026 h18:00
1000	Venti	03 Nodi da Nord	01 Nodi da Nord	01 nodi da N-Ovest
	Temperature	-05 °C	-05 °C	-03 °C
	Temp.percepita	-8 °C	-5 °C	-3 °C
2000	Venti	03 Nodi da Nord	01 Nodi da Nord	01 nodi da N-Ovest
	Temperature	-05 °C	-05 °C	-03 °C
	Temp.percepita	-8 °C	-5 °C	-3 °C
3000	Venti	07 Nodi da Nord	04 Nodi da Nord	04 Nodi da Ovest
	Temperature	-10 °C	-08 °C	-08 °C
	Temp.percepita	-16 °C	-12 °C	-12 °C
Zero termico		1100-1300 m.	1200-1400 m.	1200-1400 m.
Fenomeno		—	—	—
Stato del cielo				

LEGENDA FENOMENI

— Assenza Fenomeni · Nebbia · Foschia · Pioggia debole · Pioggia moderata · Pioggia forte · Temporali

Nevicata debole · Nevicata moderata · Nevicata forte

STATO DEL CIELO

Sereno · Poco nuvoloso · Nuvoloso · Molto nuvoloso · Coperto

Parametri meteonivometrici registrati presso i campi di rilevamento il 14/02/2026.

Località	Comune	Quota (m.s.l.m.)	Altezza neve (cm)	Neve caduta nelle 24 ore (cm)	Temp. Min (°C)	Temp. Max (°C)	Condizioni del tempo
SPONDA	Livigno (SO)	2150	52	3	-6	+1	Nevicata debole intermittente
BORMIO2000-LECCIONA	Valdisotto (SO)	2050	55	1	-3	+4	Assenza di precipitazioni
VALAR	Valdidentro (SO)	1930	64	4	-7	+4	Assenza di precipitazioni
DOSSO DEL VALLONE	Valfurva (SO)	2582	62	3	-7	-4	Assenza di precipitazioni
ALPE PALU'	Chiesa in Valmalenco (SO)	2010	78	6	-6	+3	Nevicata debole continua
PREDA	Edolo (BS)	1580	36	2	-1	+8	Assenza di precipitazioni
COLONIA VIGILI	Ponte di Legno (BS)	1640	54	10	N.P.	N.P.	Nevicata moderata
PISTA STELVIO *	Bormio (SO)	2300	65	3	N.P.	N.P.	Assenza di precipitazioni

(*) Rilievi fuori campo

L'INFORMAZIONE E' PREVENZIONE - LEGGI L'ATTUALE GRADO DI PERICOLO VALANGHE!

IL CAPO DEL CENTRO NAZIONALE METEOMONT
(Ten. Col. RFI Emanuela Gini)
FIRMA AUTOGRAFA OMESSA AI SENSI
DELL'ART.3 DEL D.LGS N.39/1993

Bollettino realizzato su scala sinottica-regionale (standard EAWS). La sua valutazione non può escludere in alcun modo la necessità di una seria e capace valutazione locale del pericolo (singolo pendio) che può essere anche sensibilmente diverso. Le previsioni meteorologiche sono relative all'orario UTC (per l'Italia +1 in inverno e +2 in estate).