MINISTERO DELLA DIFESA

meteomont
Servizio Nazionale di previsione neve e valanghe

EAWS EUROPEAN AVALANCHE WARNING SERVICES

CARABINIERI

ALPI PENNINE

Bollettino Valanghe N. 347/2026 del 15/02/2026 ore 14.00
Validità 48 ore prossima emissione 16/02/2026

A cura del Servizio METEOMONT dell'ARMA dei CARABINIERI
In collaborazione con Servizio Meteorologico dell'Aeronautica militare

SITUAZIONE alle 14:00 del 15/02/2026

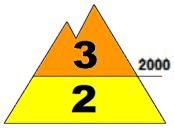

SITUAZIONE TIPO: neve a debole coesione e vento.



SITUAZIONE TIPO: neve a debole coesione e vento.

Quota neve (mslm)	Nord	Sud
	800 - 1000	1100 - 1200

Altezza Neve (cm)	Neve al suolo	Neve Fresca	Quota (mslm)
	139	000	2410
	076	000	1515

VALANGHE OSSERVATE: Valanghe di piccole dimensioni, I due tipi di valanghe di neve di superficie.

PREVISIONI 16/02/2026

GRADO DI PERICOLO: MARCATO 3

SITUAZIONE TIPO: neve a debole coesione e vento.



SITUAZIONE TIPO: neve a debole coesione e vento.

MANTO NEVOSO: La stabilità del manto nevoso è molto scarsa su molti punti (aree) per tutte le esposizioni al di sopra di 2000 mslm, possibili valanghe di dimensioni medie.
La stabilità del manto nevoso è scarsa su molti punti (aree) per tutte le esposizioni al di sotto di 2000 mslm, possibili valanghe di dimensioni medie.

AVVERTENZE

In considerazione delle avverse condizioni meteorologiche previste , le attività al di fuori delle piste battute e segnalate sono sconsigliate.

SCALA EUROPEA DEL GRADO DI PERICOLO VALANGHE

LEGENDA PROBLEMA

Bollettino realizzato su scala sinottica-regionale (standard EAWS). La sua valutazione non può escludere in alcun modo la necessità di una seria e capace valutazione locale del pericolo (singolo pendio) che può essere anche sensibilmente diverso. Le previsioni meteorologiche sono relative all'orario UTC (per l'Italia +1 in inverno e +2 in estate).

MINISTERO DELLA DIFESA

meteomont
Servizio Nazionale di previsione neve e valanghe

EAWS EUROPEAN AVALANCHE WARNING SERVICES

CARABINIERI

AERONAUTICA MILITARE SERVIZIO METEOROLOGICO

ALPI PENNINE

PREVISIONE METEO

Quota		16/02/2026 h6:00	16/02/2026 h12:00	16/02/2026 h18:00
1000	Venti	02 Nodi da Ovest	03 Nodi da Ovest	03 Nodi da Ovest
	Temperature	-01 °C	+02 °C	-03 °C
	Temp.percepita	-1 °C	0 °C	-5 °C
2000	Venti	05 Nodi da Ovest	09 nodi da Ovest	06 nodi da N-Ovest
	Temperature	-02 °C	-03 °C	-05 °C
	Temp.percepita	-5 °C	-8 °C	-10 °C
3000	Venti	13 nodi da N-Ovest	21 nodi da N-Ovest	20 nodi da N-Ovest
	Temperature	-08 °C	-10 °C	-12 °C
	Temp.percepita	-16 °C	-21 °C	-23 °C
Zero termico		1200-1400 m.	1600-1800 m.	1000-1200 m.
Fenomeno				
Stato del cielo				

LEGENDA FENOMENI

Assenza Fenomeni · Nebbia · Foschia · Pioggia debole · Pioggia moderata · Pioggia forte · Temporali

Nevicata debole · Nevicata moderata · Nevicata forte

STATO DEL CIELO

Sereno · Poco nuvoloso · Nuvoloso · Molto nuvoloso · Coperto

Parametri meteonivometrici registrati presso i campi di rilevamento il 15/02/2026.

Località	Comune	Quota (m.s.l.m.)	Altezza neve (cm)	Neve caduta nelle 24 ore (cm)	Temp. Min (°C)	Temp. Max (°C)	Condizioni del tempo
ALPE LUSENTINO	Domodossola (VB)	1184	16	0	+1	+7	Assenza di precipitazioni
OPACO DI PECETTO	Macugnaga (VB)	1330	60	0	N.P.	N.P.	Assenza di precipitazioni

(*) Rilievi fuori campo

L'INFORMAZIONE E' PREVENZIONE - LEGGI L'ATTUALE GRADO DI PERICOLO VALANGHE!

IL CAPO DEL CENTRO NAZIONALE METEOMONT
(Ten. Col. RFI Emanuela Gini)
FIRMA AUTOGRAFA OMESSA AI SENSI
DELL'ART.3 DEL D.LGS N.39/1993