MINISTERO DELLA DIFESA

meteomont
Servizio Nazionale di previsione neve e valanghe

EAWS EUROPEAN AVALANCHE WARNING SERVICES

CARABINIERI

In collaborazione con: MARCHE

APPENNINO UMBRO-MARCHIG. MERID. - MONTI SIBILLINI

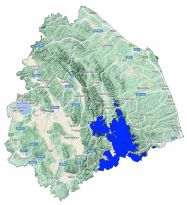

Bollettino Valanghe N. 299/2026 del 14/02/2026 ore 14.00
Validità 48 ore prossima emissione 15/02/2026

A cura del Servizio METEOMONT dell'ARMA dei CARABINIERI
In collaborazione con Servizio Meteorologico dell'Aeronautica militare

SITUAZIONE alle 14:00 del 14/02/2026

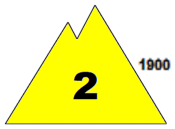

SITUAZIONE TIPO: neve a debole coesione e vento.



SITUAZIONE TIPO: pioggia su neve.

Quota neve (mslm)	Nord	Sud
	1500 - 1600	1600 - 1700

Altezza Neve (cm)	Neve al suolo	Neve Fresca	Quota (mslm)
	90-150	005	2000
	25 -45	002	1700

VALANGHE OSSERVATE: Nessuna valanga.

PREVISIONI 15/02/2026

GRADO DI PERICOLO: MARCATO 3

SITUAZIONE TIPO: neve a debole coesione e vento.

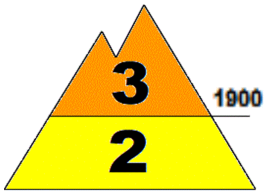



SITUAZIONE TIPO: pioggia su neve.

MANTO NEVOSO: La stabilità del manto nevoso è scarsa su molti punti (aree) per tutte le esposizioni al di sopra di 1900 mslm, possibili valanghe di dimensioni medie.
La stabilità del manto nevoso è scarsa su alcuni punti (aree) per isolati pendii al di sotto di 1900 mslm, possibili valanghe di dimensioni piccole.

AVVERTENZE

In considerazione delle avverse condizioni meteorologiche in atto, le attività al di fuori delle piste battute e segnalate sono limitate. Se effettuate, richiedono ottime capacità di valutazione del pericolo locale.

SCALA EUROPEA DEL GRADO DI PERICOLO VALANGHE

5 - MOLTO FORTE | *4 - FORTE* | *3 - MARCATO* | *2 - MODERATO* | *1 - DEBOLE* | NO NEVE *NO NEVE* | *NO INFO*

LEGENDA PROBLEMA

NEVE FRESCA | *LASTRONI DA VENTO* | *STRATI DEBOLI PERSISTENTI* | *NEVE BAGNATA* | *SLITTAMENTO* | *CORNICI* | *NESSUN PROBLEMA VALANGHIVO EVIDENTE* | *NO_INFO*

Bollettino realizzato su scala sinottica-regionale (standard EAWS). La sua valutazione non può escludere in alcun modo la necessità di una seria e capace valutazione locale del pericolo (singolo pendio) che può essere anche sensibilmente diverso. Le previsioni meteorologiche sono relative all'orario UTC (per l'Italia +1 in inverno e +2 in estate).

MINISTERO DELLA DIFESA

meteomont Servizio Nazionale di previsione neve e valanghe

EAWS EUROPEAN AVALANCHE WARNING SERVICES

CARABINIERI

In collaborazione con: MARCHE

APPENNINO UMBRO-MARCHIG. MERID. - MONTI SIBILLINI

PREVISIONE METEO

Quota		15/02/2026 h6:00	15/02/2026 h12:00	15/02/2026 h18:00
1000	Venti	03 Nodi da Nord	03 Nodi da Est	01 Nodi da Sud
	Temperature	+02 °C	-01 °C	-01 °C
	Temp.percepita	0 °C	-3 °C	-1 °C
2000	Venti	06 Nodi da Nord	05 Nodi da Est	03 nodi da Ovest
	Temperature	-01 °C	-04 °C	-01 °C
	Temp.percepita	-5 °C	-8 °C	-3 °C
3000	Venti	08 Nodi da N-Est	03 Nodi da N-Est	08 nodi da N-Ovest
	Temperature	-07 °C	-06 °C	-07 °C
	Temp.percepita	-13 °C	-9 °C	-13 °C
Zero termico		1700-1900 m.	1300-1500 m.	1300-1500 m.
Fenomeno				—
Stato del cielo				

LEGENDA FENOMENI

— Assenza Fenomeni · Nebbia · Foschia · Pioggia debole · Pioggia moderata · Pioggia forte · Temporali

Nevicata debole · Nevicata moderata · Nevicata forte

STATO DEL CIELO

Sereno · Poco nuvoloso · Nuvoloso · Molto nuvoloso · Coperto

Parametri meteonivometrici registrati presso i campi di rilevamento il 14/02/2026.

Località	Comune	Quota (m.s.l.m.)	Altezza neve (cm)	Neve caduta nelle 24 ore (cm)	Temp. Min (°C)	Temp. Max (°C)	Condizioni del tempo
FORCA DI GUALDO	Castelsantangelo sul Nera (MC)	1496	37	2	0	+7	Nevicata moderata
LA VALLETTA	Bolognola (MC)	1352	0	0	0	+4	Assenza di precipitazioni
FORCA DI PRESTA (ARQUATA DEL TRONTO) *	Arquata del Tronto (AP)	1535	1	1	N.P.	N.P.	Nevicata moderata
COLLE	Montegallo (AP)	1036	0	0	+2	+11	Assenza di precipitazioni
PARCO GUARNIERI	Montemonaco (AP)	980	0	0	+4	+14	Assenza di precipitazioni
RIFUGIO PERUGIA	Norcia (PG)	1500	0	0	N.P.	N.P.	Nevicata debole intermittente
FRONTIGNANO *	Ussita (MC)	1483	0	0	N.P.	N.P.	Assenza di precipitazioni

(*) Rilievi fuori campo

L'INFORMAZIONE E' PREVENZIONE - LEGGI L'ATTUALE GRADO DI PERICOLO VALANGHE!

IL CAPO DEL CENTRO NAZIONALE METEOMONT
(Ten. Col. RFI Emanuela Gini)
FIRMA AUTOGRAFA OMESSA AI SENSI
DELL'ART.3 DEL D.LGS N.39/1993

Bollettino realizzato su scala sinottica-regionale (standard EAWS). La sua valutazione non può escludere in alcun modo la necessità di una seria e capace valutazione locale del pericolo (singolo pendio) che può essere anche sensibilmente diverso. Le previsioni meteorologiche sono relative all'orario UTC (per l'Italia +1 in inverno e +2 in estate).