GOBIERNO DE ESPAÑA
VICEPRESIDENCIA TERCERA DEL GOBIERNO
MINISTERIO PARA LA TRANSICIÓN ECOLÓGICA Y EL RETO DEMOGRÁFICO

Boletín de información nivológica y de peligro de aludes

Pirineo Catalán

aemet Agencia Estatal de Meteorología

lunes, 16 de febrero de 2026

Pronóstico hasta las 24 horas del martes, día 17 de febrero

(Válido fuera de pistas de esquí balizadas y abiertas)

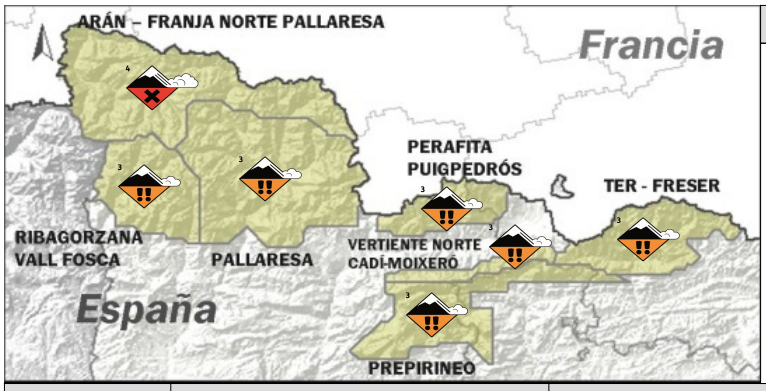

Problemas de aludes

Placas de viento

Nieve húmeda

Macizo	Peligro	Problemas de aludes, cota, orientación, tamaño	Innivación observada (m)
Arán - Franja norte Pallaresa	4 / 4 3 2500 / Fuerte	Placas de viento: 2100 ↑, N O E S, 3 Nieve húmeda: 2100 ↓, N O E S, 2	2026-02-16 N S Cotas bajas
Ribagorzana - Vall Fosca	3 / 3 2 2100 / Notable	Placas de viento: 2100 ↑, N O E S, 2 Nieve húmeda: 2100 ↓, N O E S, 2	2026-02-16 N S Cotas bajas
Pallaresa	3 / 3 2 2100 / Notable	Placas de viento: 2100 ↑, N O E S, 2 Nieve húmeda: 2100 ↓, N O E S, 2	2026-02-16 N S Cotas bajas

AEMET. Se autoriza la reproducción de su contenido citando la fuente.

Boletín de información nivológica y de peligro de aludes

Pirineo Catalán

Perafita - Puigpedrós	3 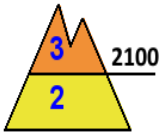 **Notable**	**Placas de viento**  **Nieve húmeda** 	2026-02-16 Cotas bajas
Ter - Freser	3 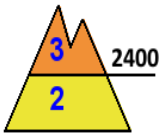 **Notable**	**Placas de viento** 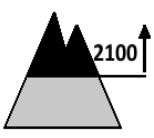  **Nieve húmeda** 	2026-02-16 Cotas bajas
Vertiente norte Cadí - Moixeró	3 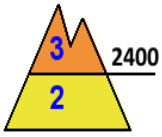 **Notable**	**Placas de viento** 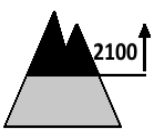  **Nieve húmeda** 	2026-02-16 Cotas bajas
Prepirineo	3 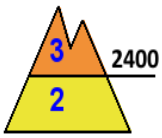 **Notable**	**Placas de viento** 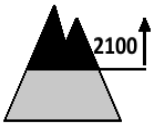  **Nieve húmeda** 	2026-02-16 Cotas bajas

Estado del manto y observaciones recientes

Las precipitaciones de los últimos días están siendo mucho más significativas en el Arán y la Franja Norte Pallaresa. Allí están teniendo lugar importantes procesos de humidificación en cotas medias y bajas a causa del actual episodio de precipitaciones, al tiempo que se siguen formando placas de viento en cotas altas. En el resto de zonas, las precipitaciones fueron inferiores pero la nieve sufrió importantes procesos de transporte debido a los intensos vientos.

AEMET. Se autoriza la reproducción de su contenido citando la fuente.

El manto es continuo desde cotas bajas, con espesores que en la mayor parte de la cordillera se encuentran en máximos, muy por encima de lo que cabría esperar a estas alturas de la temporada, superándose los 150 a 200 cm por encima de 2.200 metros en numerosas áreas.

Su perfil consta de múltiples capas, la más externa de nieve reciente de grosor variable y algunas de ellas estratos de nieve encostrada, aunque predomina el grano fino y grano redondo. En la alta montaña la nieve se presenta más seca, menos evolucionada y muy venteada.

Evolución del manto y peligro de aludes para el martes, día 17

Problemas de placas de viento y nieve reciente en cotas altas. Problema de nieve húmeda en cotas medias y bajas.

En cotas altas, siguen activos los procesos de formación de placas de viento. Estas se han ido formando en una mayoría de orientaciones, aunque con prevalencia de los sectores este y sur, y todavía permanecen frágiles, especialmente en la alta montaña donde la nieve se ha mantenido más seca y ligera. Serán susceptibles de colapsar ante sobrecargas débiles y podrán desencadenar aludes de tamaño mediano o grande.

También en cotas altas pero en zonas al abrigo del viento, pueden haber acumulaciones de nieve que den lugar a aludes de nieve reciente accidentales de tamaño pequeño o localmente mediano. Este problema está limitado al sector del Arán-F.N.Pallaresa

En cotas medias y bajas, en laderas con la suficiente inclinación, serán probables algunos aludes de nieve húmeda, ya sean espontáneos, debidos a lluvias débiles o a la radiación solar, o accidentales. Estos serán de tamaño pequeño o mediano. No se descarta algún deslizamiento basal.

Predicción meteorológica para el martes, día 17

Muy nuboso o cubierto, tendiendo a abrir grandes claros durante la segunda mitad del día. Precipitaciones débiles y ocasionales, principalmente en el valle de Arán y Franja Norte Pallaresa. Cota de nieve en torno a 900-1000 metros, subiendo por la tarde a unos 1700. Temperaturas mínimas en ligero o moderado descenso, y máximas en ligero o moderado descenso. Heladas débiles, moderadas en cotas altas, donde podrán ser localmente fuertes. Viento fuerte del noroeste, con rachas muy fuertes en cotas altas y zonas expuestas, que podrán superar los 100 km/h en algunos puntos, tendiendo a oeste y aflojando por la tarde.

Datos en la atmósfera libre:

Altitud de la isoterma de 0 ºC: 2000 m
Altitud de la isoterma de -10 ºC: 4600 m

Viento a 1500 m: NW 20 km/h
Viento a 3000 m: NW 100 km/h

AEMET. Se autoriza la reproducción de su contenido citando la fuente.

Evolución para el miércoles día 18

Nivel de peligro sin cambios o en ligero descenso.

Escala europea de peligro de aludes

Débil | Limitado | Notable | Fuerte | Muy Fuerte

Problemas de aludes

Nieve reciente | Placas de viento | Capas débiles persistentes | Nieve húmeda | Deslizamientos basales | Sin problema evidente

Nota1: Se recuerda que, siempre que haya nieve, la ausencia total de peligro no existe. Hay que tener presente que en circunstancias desfavorables, con aludes de tamaño 1 (alud pequeño o colada) y tamaño 2 (alud mediano), se pueden sufrir severos daños personales.

Nota2: Los BPA se elaboran en base a información meteorológica así como al estado del manto nivoso a través de sondeos puntuales. Se advierte a los usuarios de la variabilidad de esta información al extrapolarla a zonas extensas de montaña. Por ello, AEMET no se hace responsable de su uso para la toma de decisiones que conciernen a la seguridad personal, ni de los riesgos físicos o materiales de ellas derivadas.

AEMET. Se autoriza la reproducción de su contenido citando la fuente.