aineva.it

Dienstag 17.02.2026

Veröffentlicht am 16.02.2026 um 17:00

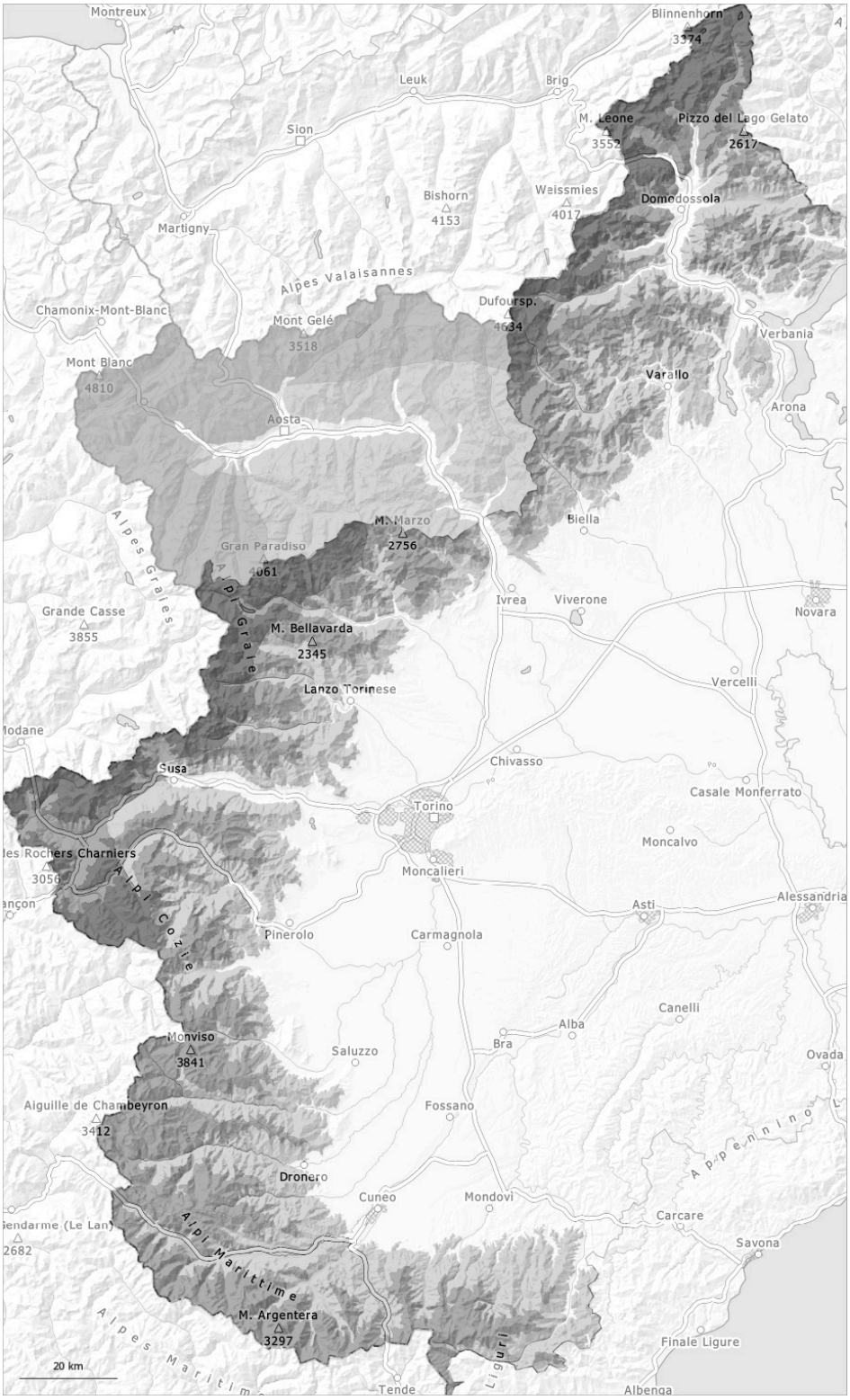

1	2	3	4	5
gering	mäßig	erheblich	groß	sehr groß

Gefahrenstufe 4 - Groß

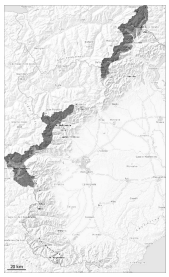

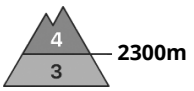

Tendenz: Lawinengefahr bleibt gleich
am Mittwoch, den 18.02.2026

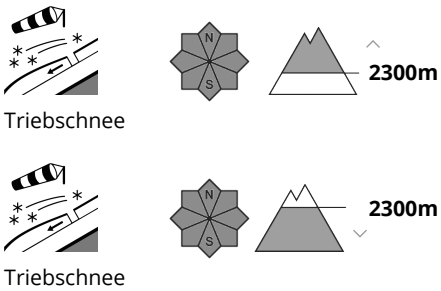

Mit Neuschnee und Sturm gefährliche Lawinensituation.

Bis am Mittag fällt vor allem entlang der Grenze zu Frankreich, entlang der Grenze zwischen dem Wallis und Italien etwas Schnee.

Der starke Wind verfrachtet den Neuschnee. Mit Schneefall und teils stürmischem Nordwestwind entstehen frische Triebschneeansammlungen. Dies vor allem in Rinnen und Mulden und im Bereich der Waldgrenze und in den Hauptniederschlagsgebieten.
Die störanfälligen Triebschneeansammlungen können schon von einzelnen Wintersportlern leicht ausgelöst werden.

An Triebschneehängen und an sehr steilen Hängen sind mittlere bis große Schneebrettlawinen möglich, vereinzelt auch aus steilen und hoch gelegenen südostseitigen und noch nicht entladenen Einzugsgebieten.

Schneedecke

Gefahrenmuster gm.6: lockerer schnee und wind

Gestern fielen gebietsweise verbreitet 25 bis 40 cm Schnee, lokal auch mehr. Bis am Mittag fällt etwas Schnee.
Der teilweise stürmische Wind verfrachtet Neu- und Altschnee intensiv.
V.a. in Gipfellagen liegen je nach Windeinfluss sehr unterschiedliche Schneehöhen.
In der Altschneedecke sind vor allem an steilen Nordwest-, Nord- und Osthängen Schwachschichten vorhanden. Verschiedene Triebschneeschichten liegen stellenweise auf Oberflächenreif.

Gefahrenstufe 3 - Erheblich

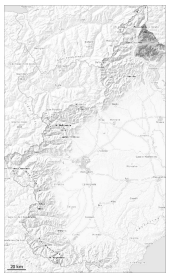

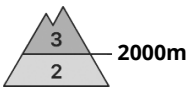

Tendenz: Lawinengefahr bleibt gleich
am Mittwoch, den 18.02.2026

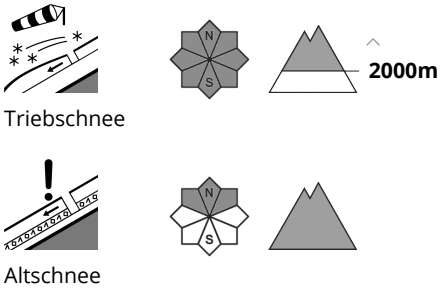

Triebschnee

Altschnee

Triebschnee beachten.

Der starke Wind verfrachtet den Neuschnee. Frische und schon etwas ältere Triebschneeansammlungen können teilweise von einzelnen Wintersportlern ausgelöst werden. Sie sind bei der schlechten Sicht kaum erkennbar.

Die Gefahrenstellen liegen vor allem in Rinnen, Mulden und hinter Geländekanten sowie an Übergängen von wenig zu viel Schnee.

Sehr vereinzelt können Lawinen auch im Altschnee anbrechen und groß werden.

Schneedecke

Gefahrenmuster gm.6: lockerer schnee und wind

Gestern fielen lokal oberhalb von rund 1000 m 10 bis 20 cm Schnee. Am Vormittag fällt lokal wenig Schnee. In der Altschneedecke sind v.a. an steilen West-, Nord- und Osthängen Schwachschichten vorhanden.

Gefahrenstufe 3 - Erheblich

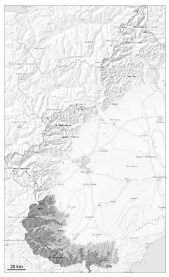

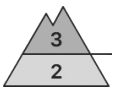

Waldgrenze

Tendenz: Lawinengefahr bleibt gleich
am Mittwoch, den 18.02.2026

Triebschnee

Waldgrenze

Triebschnee

Triebschnee im Hochgebirge.

Mit zunehmend starkem Wind aus westlichen Richtungen entstehen in der Höhe gut sichtbare Triebschneeansammlungen.
Triebschneeansammlungen können schon von einzelnen Wintersportlern ausgelöst werden, besonders an steilen Schattenhängen im Hochgebirge sowie an Triebschneehängen. Vorsicht an Übergängen in Rinnen und Mulden.

Vereinzelt können Lawinen auch im Altschnee anbrechen und groß werden.

Die Aktivität von feuchten und nassen Lawinen nimmt mit der Abkühlung ab.

Schneedecke

Gefahrenmuster gm.6: lockerer schnee und wind

In den letzten Tagen entstanden verbreitet harte Triebschneeansammlungen. Der teilweise stürmische Wind verfrachtet den lockeren Altschnee. In Gipfellagen liegen je nach Windeinfluss sehr unterschiedliche Schneehöhen.
Mit mäßigem Wind aus nordwestlichen Richtungen entstehen meist kleine Triebschneeansammlungen.

Tiefe und mittlere Lagen: Mit der Abkühlung und starkem Westwind bildet sich in der Nacht eine Oberflächenkruste.

Hohe Lagen und Hochgebirge: In der Altschneedecke sind vor allem an steilen Nordwest-, Nord- und Nordosthängen Schwachschichten vorhanden.

Gefahrenstufe 3 - Erheblich

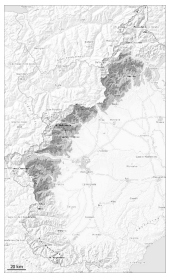

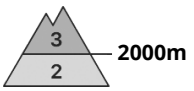

Tendenz: Lawinengefahr bleibt gleich
am Mittwoch, den 18.02.2026

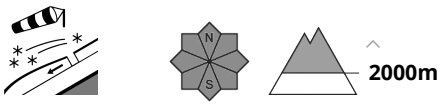

Triebschnee

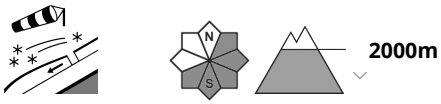

Triebschnee

Der Wind bläst zeitweise stark bis stürmisch. Triebschnee ist die Hauptgefahr.

Der teilweise starke Wind verfrachtet Neu- und Altschnee. Mit starkem Nordwestwind entstehen im Tagesverlauf frische Triebschneeansammlungen. Diese entstehen vor allem zwischen etwa 2100 und 2500 m.
Die Triebschneeansammlungen sind bei der schlechten Sicht kaum erkennbar. Sie können schon von einzelnen Wintersportlern ausgelöst werden.
Vorsicht vor allem an Hängen und an Triebschneehängen v.a. oberhalb der Waldgrenze.

Schneedecke

Gefahrenmuster gm.6: lockerer schnee und wind

Gestern fielen oberhalb von rund 1400 m 10 bis 25 cm Schnee. Der starke Wind verfrachtet den Neuschnee intensiv.
V.a. in Gipfellagen liegen je nach Windeinfluss sehr unterschiedliche Schneehöhen.

In der Altschneedecke sind vor allem an steilen Nordwest-, Nord- und Osthängen Schwachschichten vorhanden.