Dienstag 17.02.2026

Veröffentlicht am 16.02.2026 um 17:00

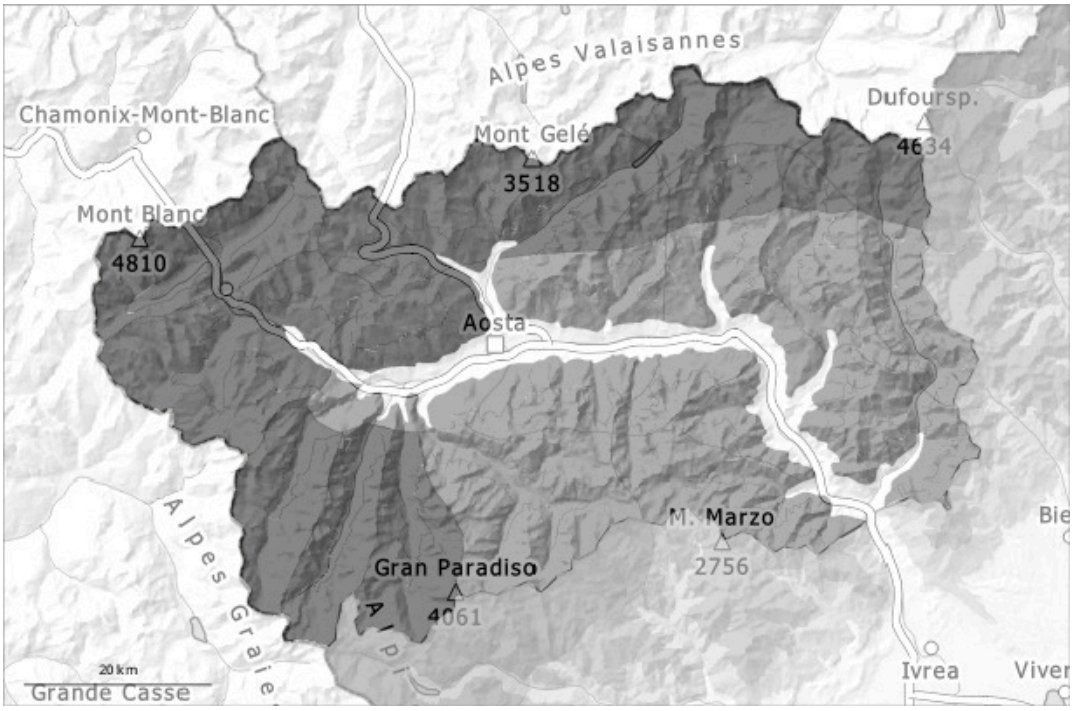

1	2	3	4	5
gering	mäßig	erheblich	groß	sehr groß

Gefahrenstufe 4 - Groß

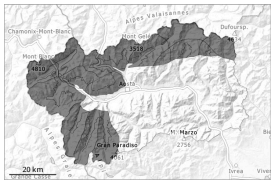

Tendenz: Lawinengefahr nimmt ab
am Mittwoch, den 18.02.2026

Triebschnee

1800m

Neuschnee

Weiterer Anstieg der Gefahr von trockenen Lawinen mit Neuschnee und starkem Wind.

Mit Schneefall oberhalb von rund 1000 m und teils stürmischem Nordwestwind wachsen die Triebschneeansammlungen im Tagesverlauf an. Nach Südosten hin nehmen Anzahl und Größe der Gefahrenstellen zu.
Besonders an sehr steilen Hängen und an Triebschneehängen sind zahlreiche mittlere und mehrfach große spontane Lawinen zu erwarten. Die Lawinen können dort in tiefen Schichten ausgelöst werden und sehr groß werden.
Die Lawinen können vor allem in den typischen Lawinenzügen bis in Tallagen vorstoßen und exponierte Verkehrswege gefährden.
Für Touren und Variantenabfahrten abseits gesicherter Pisten sind die Verhältnisse sehr heikel. Fernauslösungen sind möglich. Einzelne Wintersportler können Lawinen auslösen, auch große. Vorsicht an steilen Hängen und in Rinnen, Mulden und hinter Geländekanten.

Schneedecke

Gefahrenmuster gm.6: lockerer schnee und wind | gm.1: bodennahe schwachschicht

Bis in die Nacht fallen oberhalb von rund 1500 m verbreitet 40 bis 60 cm Schnee, lokal bis zu 80 cm. Bis Dienstag fallen oberhalb von rund 1000 m verbreitet 10 bis 25 cm Schnee. Am Montag blies der Wind verbreitet stark bis stürmisch. Bis Dienstag bläst der Wind verbreitet stark bis stürmisch.
Der Neuschnee sowie die während dem Schneefall entstehenden Triebschneeansammlungen werden zunehmend störanfällig.
Die Schneedecke ist ungünstig geschichtet.
In Kamm- und Passlagen liegen je nach Windeinfluss sehr unterschiedliche Schneehöhen.
Im Tagesverlauf sind mehrere mittlere bis große spontane trockene Lawinen abgegangen. In den letzten Tagen wurden mehrere Schneebrettlawinen ausgelöst.

Tendenz

> Die Wetterbedingungen erlauben eine allmähliche Verfestigung der Schneedecke.

Gefahrenstufe 3 - Erheblich

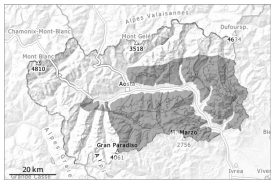

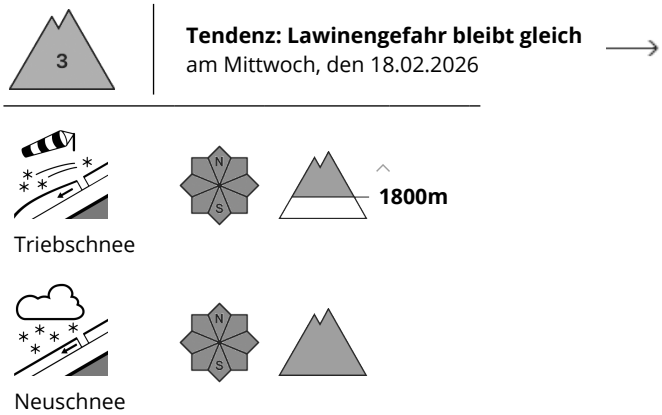

Allmählicher Anstieg der Gefahr von trockenen Lawinen mit Neuschnee und starkem Wind.

Mit Neuschnee und starkem Wind nehmen Anzahl und Größe der Gefahrenstellen zu.
Hoch gelegene Einzugsgebiete werden mit Schneefall und Wind weiter aufgefüllt.
Besonders an sehr steilen Hängen und an Triebschneehängen sind mittlere spontane Lawinen möglich.
Die Lawinen können stellenweise im Altschnee ausgelöst werden und recht groß werden.
Fernauslösungen sind möglich. Schwachschichten im Altschnee erfordern Vorsicht. Wummgeräusche und Risse beim Betreten der Schneedecke sind Alarmzeichen.
Einzelne Wintersportler können Lawinen auslösen. Vorsicht an steilen Hängen und in Rinnen, Mulden und hinter Geländekanten.

Schneedecke

Gefahrenmuster gm.6: lockerer schnee und wind | gm.1: bodennahe schwachschicht

Bis in die Nacht fallen oberhalb von rund 1600 m verbreitet 15 bis 40 cm Schnee. Bis Dienstag fallen oberhalb von rund 1200 m verbreitet 10 bis 20 cm Schnee. Der Wind bläst stark bis stürmisch.
In Kamm- und Passlagen liegen je nach Windeinfluss sehr unterschiedliche Schneehöhen. Die Schneedecke ist ungünstig geschichtet.
In der Altschneedecke sind v.a. an West-, Nord- und Osthängen kantig aufgebaute Schwachschichten vorhanden.

Tendenz

Die Wetterbedingungen erlauben eine langsame Verfestigung der Schneedecke.