Martedì 17.02.2026

Pubblicato il 16.02.2026 alle ore 17:00

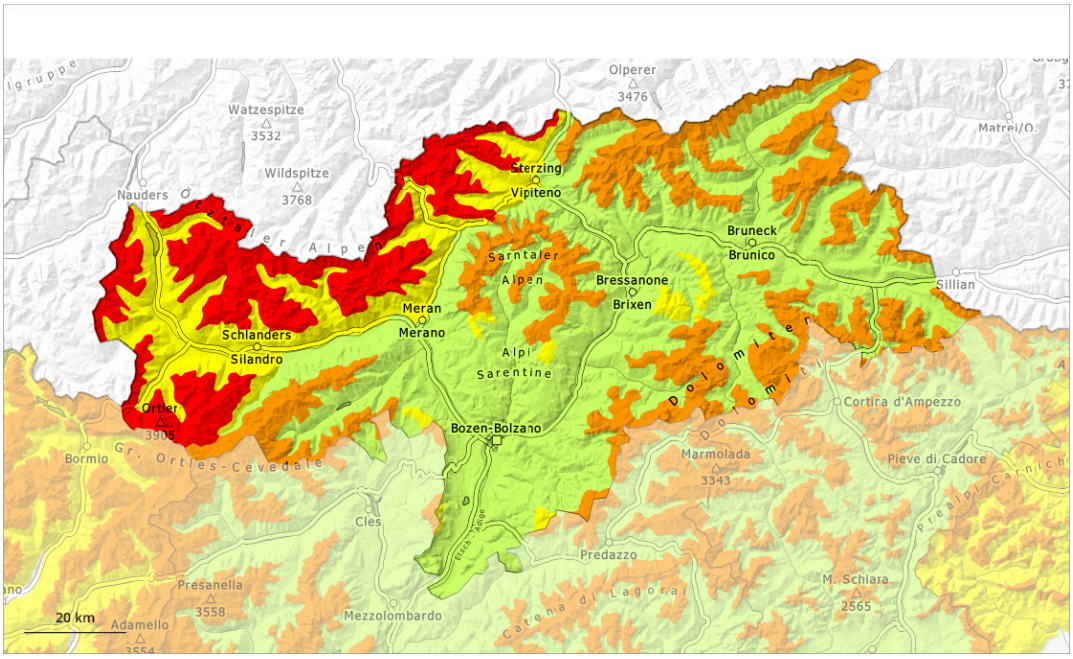

1	2	3	4	5
debole	moderato	marcato	forte	molto forte

Grado di pericolo 4 - Forte

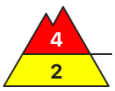

1800m

Tendenza: pericolo valanghe stabile
per Mercoledì il 18.02.2026

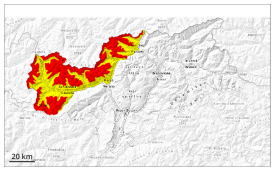

Strati deboli persistenti

1800m

Lastrone da vento

Limite del bosco

Neve fresca

Al di fuori delle piste assicurate, la situazione valanghiva è molto pericolosa. Il pericolo si riferisce principalmente alle zone alpine frequentate dagli appassionati di sport invernali.

La neve fresca e gli accumuli di neve ventata che si formeranno con il vento proveniente da ovest di forte intensità possono facilmente subire un distacco provocato o spontaneo a tutte le esposizioni al di sopra del limite del bosco. I punti pericolosi si trovano anche in prossimità del limite del bosco. Sono possibili distacchi a distanza.

Le valanghe possono in parte coinvolgere gli strati più profondi e raggiungere grandi dimensioni. Ciò sui pendii esposti a ovest, nord ed est. Attenzione soprattutto ai bacini di alimentazione riparati dal vento non ancora scaricati.

Sui pendii molto ripidi, sono possibili valanghe di neve a debole coesione di piccole e, a livello isolato, di medie dimensioni.

Manto nevoso

Situazione tipo st.1: strato debole persistente basale | st.6: neve a debole coesione e vento

Da domenica sono caduti da 15 a 30 cm di neve. Fino a mercoledì cadranno da 15 a 20 cm di neve, localmente anche di più. Il vento sarà da forte a tempestoso.

La neve fresca e soprattutto gli accumuli di neve ventata estesi verranno depositati su un debole manto di neve vecchia soprattutto sui pendii esposti a ovest, nord ed est al di sopra del limite del bosco.

In alcuni punti diversi strati di neve ventata poggiano su brina di superficie.
Nella parte basale del manto nevoso si trovano strati fragili a cristalli sfaccettati.

Tendenza

Per le escursioni e le discese fuori pista, le condizioni sono molto pericolose. Con il vento proveniente da ovest di forte intensità, sono ancora possibili valanghe spontanee.

Grado di pericolo 3 - Marcato

Tendenza: pericolo valanghe stabile
per Mercoledì il 18.02.2026

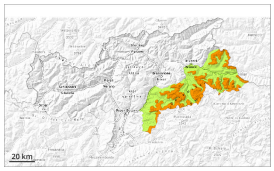

Strati deboli persistenti

1800m

Lastrone da vento

2000m

Gli strati deboli molto pronunciati presenti nella neve vecchia richiedono attenzione.

Gli strati deboli molto pronunciati presenti nella neve vecchia possono distaccarsi già in seguito al passaggio di un singolo appassionato di sport invernali. Le valanghe sono per lo più di dimensioni medie. Attenzione soprattutto sui pendii ripidi esposti a ovest, nord ed est al di sopra dei 1800 m circa. I punti pericolosi sono difficili da individuare. Isolati rumori di "whum" sono possibili segnali di pericolo.

Inoltre soprattutto nelle zone in prossimità delle creste, nelle conche e nei canaloni gli accumuli di neve ventata per lo più di piccole dimensioni sono instabili. Ciò soprattutto al di sopra dei 2000 m circa. Essi sono ben individuabili dall'escursionista esperto.

Manto nevoso

Situazione tipo st.1: strato debole persistente basale | st.8: brina di superficie sepolta

Cadrà un po' di neve. Con vento forte proveniente dai quadranti nord occidentali principalmente nelle conche e nei canaloni si formeranno accumuli di neve ventata instabili. Gli accumuli di neve ventata meno recenti poggiano in parte su brina di superficie.

Al di sopra dei 1800 m circa: Il manto nevoso è instabile. All'interno del manto di neve vecchia si trovano pronunciati strati fragili. Ciò soprattutto sui pendii esposti a ovest, nord ed est.

Tendenza

Gli strati deboli presenti nella neve vecchia rappresentano la principale fonte di pericolo.

Grado di pericolo 3 - Marcato

Limite del bosco

Tendenza: pericolo valanghe stabile
per Mercoledì il 18.02.2026

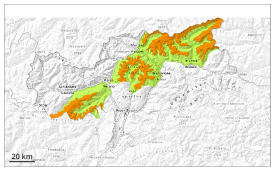

Strati deboli persistenti

Limite del bosco

Lastrone da vento

Limite del bosco

Le condizioni al di fuori delle piste sono pericolose. Attenzione alla neve ventata e alla neve vecchia con strati deboli persistenti.

Principalmente nelle zone poco frequentate, gli strati deboli molto pronunciati presenti nella neve vecchia possono distaccarsi facilmente in seguito al passaggio di un singolo appassionato di sport invernali. Attenzione soprattutto sui pendii ripidi esposti a ovest, nord ed est al di sopra del limite del bosco. Isolati punti pericolosi si trovano anche in prossimità del limite del bosco. I punti pericolosi sono difficili da individuare. I rumori di "whum" e la formazione di fessure quando si calpesta la coltre di neve così come nuove valanghe sono campanelli di allarme che rimandano a questo pericolo. Sono possibili distacchi a distanza. Le valanghe sono per lo più di dimensioni medie.

Con neve fresca e vento forte proveniente da nord ovest soprattutto al di sopra del limite del bosco si formeranno accumuli di neve ventata facilmente distaccabili, principalmente nelle conche, nei canaloni e dietro ai cambi di pendenza. Sono previste isolate valanghe spontanee.

Nelle aree confinanti con quelle interessate dal grado di pericolo 4 "forte" la situazione valanghiva è più pericolosa. È consigliata prudenza.

Manto nevoso

Situazione tipo st.1: strato debole persistente basale | st.8: brina di superficie sepolta

Da domenica sono caduti da 5 a 15 cm di neve, localmente anche di più. Fino a mercoledì cadranno da 5 a 15 cm di neve, localmente anche di più.
Con neve fresca e forte vento, gli accumuli di neve ventata cresceranno ulteriormente. Gli accumuli di neve ventata meno recenti poggiano in parte su brina di superficie.
All'interno del manto di neve vecchia si trovano pronunciati strati fragili. Ciò soprattutto sui pendii esposti a ovest, nord ed est al di sopra del limite del bosco.

Tendenza

Le condizioni rimangono poco critiche. Gli strati deboli presenti nella neve vecchia rappresentano la principale fonte di pericolo. Sono raccomandate attenzione e prudenza.

Grado di pericolo 2 - Moderato

Limite del bosco

Tendenza: pericolo valanghe stabile
per Mercoledì il 18.02.2026

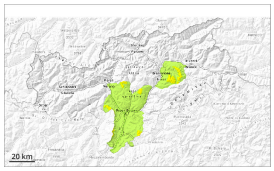

Strati deboli persistenti

Limite del bosco

Lastrone da vento

Limite del bosco

La neve ventata e la neve vecchia con strati deboli persistenti richiedono attenzione.

Le valanghe possono distaccarsi in seguito al passaggio di un singolo appassionato di sport invernali. Ciò specialmente sui pendii ombreggiati ripidi nelle zone in prossimità delle creste, nelle conche e nei canaloni al di sopra del limite del bosco.
Con il vento forte proveniente da nord, si formeranno nuovi accumuli di neve ventata. Questi ultimi sono in parte instabili. Le valanghe sono in parte di dimensioni medie.

Le escursioni richiedono attenzione e prudenza. È presente poca neve rispetto alla media stagionale.

Manto nevoso

Situazione tipo st.6: neve a debole coesione e vento

Cadrà un po' di neve. All'interno del manto di neve vecchia si trovano strati fragili a cristalli sfaccettati. Gli accumuli di neve ventata nuovi e meno recenti poggiano su una sfavorevole superficie del manto di neve vecchia in quota.

Alle quote di bassa e media montagna: Il manto nevoso è umido, con una crosta da rigelo a malapena portante in superficie.

Tendenza

Moderato pericolo di valanghe.