ICGC Institut Cartogràfic i Geològic de Catalunya

Servei Meteorològic de Catalunya meteo.cat

Boletín de peligro de aludes para el Pirineo de Catalunya
Del 16/02/2026 al 17/02/2026

(Válido fuera pistas de esquí y zonas no controladas)

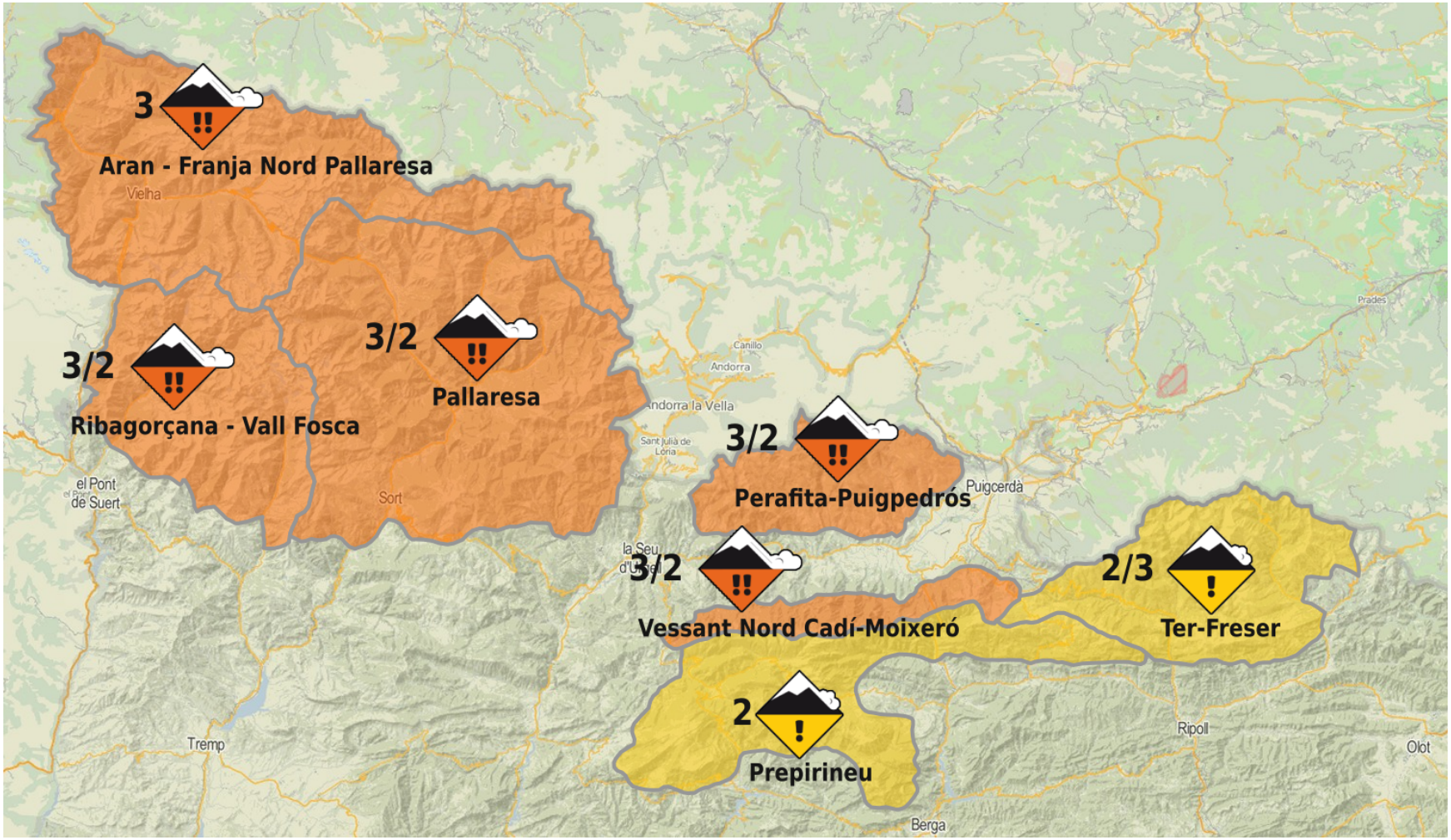

5 MUY FUERTE	4 FUERTE	3 NOTABLE	2 LIMITADO	1 DÉBIL

ICGC Institut Cartogràfic i Geològic de Catalunya

Servei Meteorològic de Catalunya

Boletín de peligro de aludes Aran - Franja Nord Pallaresa Del 16/02/2026 al 17/02/2026

(Válido fuera pistas de esquí y zonas no controladas)

NOTABLE (3).

Situación primaria

Nieve venteada

Distribución

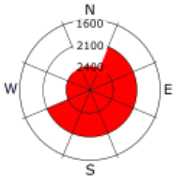

Tamaño

Origen

Tendencia

Situación secundaria

Nieve húmeda

Distribución

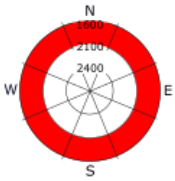

Tamaño

Origen

Tendencia

Estado del manto nivoso

Durante el fin de semana ha habido numerosa actividad, con la caída natural y accidental de placas de viento, de tamaño medio y grande. Los problemas predominantes serán las placas de viento y también los aludes de nieve húmeda, debido a las lloviznas caídas hasta la cota 2.000. El martes, las placas continuarán muy frágiles. Se habrán formado nuevas, con la última nevada del lunes (con viento) y podrán caer de forma natural o al paso de un esquiador y generar aludes de tamaño medio e incluso grande (con capacidad de enterrar a un grupo de personas). Las placas caerán a cualquier orientación, en especial en laderas norte, este y sur. Con el humedecimiento del manto, por debajo de los 2.100 se esperan también aludes de nieve húmeda y de deslizamiento basal que podrán llegar hasta tamaño medio o grande (con capacidad para enterrar uno o más montañeros).

Las condiciones son aún delicadas debido a la estabilidad muy pobre del manto. Se recomienda no circular por terreno de aludes.

Distribución del manto nivoso

Hay nieve en el suelo a 1.400 m en Norte. El manto es esquiable por encima de unos 1.500 m en umbrías. Los espesores a unos 2.200 m son superiores a los normales y rondan los 120-140 cm en el norte de Arán y los 160-200 cm en la Franja Nord Pallaresa y en el sur de Aran.

Tendencia para las próximas 48-72h

Se esperan nuevas nevadas y viento, con cota de nieve entre 1400 y 1800 m. Peligro ESTACIONARIO o EN LEVE DESCENSO.

El próximo boletín será emitido el día 2026-02-17

5 MUY FUERTE	4 FUERTE	3 NOTABLE	2 LIMITADO	1 DÉBIL

EAWS EUROPEAN AVALANCHE WARNING SERVICES

ICGC Institut Cartogràfic i Geològic de Catalunya

meteo.cat Servei Meteorològic de Catalunya

Boletín de peligro de aludes Ribagorçana - Vall Fosca Del 16/02/2026 al 17/02/2026

(Válido fuera pistas de esquí y zonas no controladas)

NOTABLE (3), por encima de 2.200 m.
LIMITADO (2), en el resto.

Situación primaria

Nieve venteada

Distribución

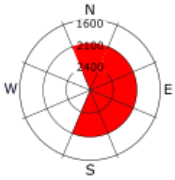

Tamaño

Origen

Tendencia

Situación secundaria

Nieve húmeda

Distribución

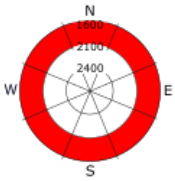

Tamaño

Origen

Tendencia

Estado del manto nivoso

La última nevada con el fuerte viento del noroeste ha transportado la nieve a las laderas a sotavento. Para el martes, el problema predominante será el de las placas de viento y, en cota baja, por nieve húmeda. Encontraremos nuevas placas, muy frágiles y podrán caer de forma natural o al paso de un esquiador y generar aludes de tamaño medio (con capacidad de enterrar a una persona). Los lugares donde se encontrarán en orientación Sur, Este y Norte, por encima del límite del bosque, bajo collados y cordales y en terreno con convexidades. Las placas de viento se mantendrán muy frágiles. En las vertientes muy inclinadas, con el humedecimiento del manto debido a las últimas lloviznas, podrán caer purgas de nieve húmeda, de pequeño tamaño y también medio. Se recomienda mucha prudencia y experiencia si debe circularse por zonas no controladas.

Distribución del manto nivoso

Hay nieve en el suelo a 1.500 m. El manto es esquiable por encima de unos 1500-1600 m. Los grosores alcanzan los 130-160 cm. Estos valores son muy superiores a los normales en la época.

Tendencia para las próximas 48-72h

Se mantendrá el viento en cota alta y caerán nuevos chubascos de nieve. Las placas se mantendrán reactivas. Peligro ESTACIONARIO O EN LEVE DESCENSO.

El próximo boletín será emitido el día 2026-02-17

5 MUY FUERTE	4 FUERTE	3 NOTABLE	2 LIMITADO	1 DÉBIL

EAWS EUROPEAN AVALANCHE WARNING SERVICES

ICGC Institut Cartogràfic i Geològic de Catalunya

meteo.cat Servei Meteorològic de Catalunya

Boletín de peligro de aludes Pallaresa
Del 16/02/2026 al 17/02/2026

(Válido fuera pistas de esquí y zonas no controladas)

NOTABLE (3), por encima de 2.200 m.
LIMITADO (2), en el resto.

Situación primaria

Nieve venteada

Distribución

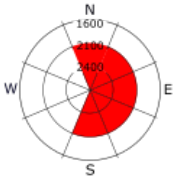

Tamaño

Origen

Tendencia

Situación secundaria

Nieve húmeda

Distribución

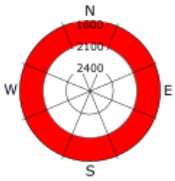

Tamaño

Origen

Tendencia

Estado del manto nivoso

La última nevada con el fuerte viento del noroeste ha transportado la nieve a las laderas a sotavento. Para el martes, el problema predominante será el de las placas de viento y, en cota baja, por nieve húmeda. Encontraremos nuevas placas, muy frágiles y podrán caer de forma natural o al paso de un esquiador y generar aludes de tamaño medio (con capacidad de enterrar a una persona). Los lugares donde se encontrarán en orientación Sur, Este y Norte, por encima del límite del bosque, bajo collados y cordales y en terreno con convexidades. Las placas de viento se mantendrán muy frágiles. En las vertientes muy inclinadas, con el humedecimiento del manto debido a las últimas lloviznas, podrán caer purgas de nieve húmeda, de pequeño tamaño y también medio. Se recomienda mucha prudencia y experiencia si debe circularse por zonas no controladas.

Distribución del manto nivoso

Hay nieve en el suelo a 1.500 m. El manto es esquiable por encima de unos 1500-1600 m. Los grosores alcanzan los 130-160 cm. Estos valores son muy superiores a los normales en la época.

Tendencia para las próximas 48-72h

Se mantendrá el viento en cota alta y caerán nuevos chubascos de nieve. Las placas se mantendrán reactivas. Peligro ESTACIONARIO O EN LEVE DESCENSO.

El próximo boletín será emitido el día 2026-02-17

5 MUY FUERTE	4 FUERTE	3 NOTABLE	2 LIMITADO	1 DÉBIL

EAWS EUROPEAN AVALANCHE WARNING SERVICES

ICGC Institut Cartogràfic i Geològic de Catalunya

Servei Meteorològic de Catalunya

Boletín de peligro de aludes Perafita-Puigpedrós Del 16/02/2026 al 17/02/2026

(Válido fuera pistas de esquí y zonas no controladas)

NOTABLE (3), por encima de 2.200 m.
LIMITADO (2), en el resto.

Situación primaria

Nieve venteada

Distribución

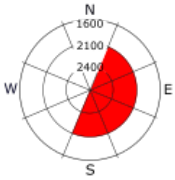

Tamaño

Origen

Tendencia

Situación secundaria

Nieve húmeda

Distribución

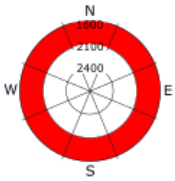

Tamaño

Origen

Tendencia

Estado del manto nivoso

La última nevada con el fuerte viento del noroeste ha transportado la nieve a las laderas a sotavento. Para el martes, el problema predominante será el de las placas de viento y, en cota baja, por nieve húmeda. Encontraremos nuevas placas, muy frágiles y podrán caer de forma natural o al paso de un esquiador y generar aludes de tamaño medio (con capacidad de enterrar a una persona). Los lugares donde se encontrarán en orientación Sur, Este y Norte, por encima del límite del bosque, bajo collados y cordales y en terreno con convexidades. Las placas de viento se mantendrán muy frágiles. En las vertientes muy inclinadas, con el humedecimiento del manto debido a las últimas lloviznas, podrán caer purgas de nieve húmeda, de pequeño tamaño y también medio. Se recomienda mucha prudencia y experiencia si debe circularse por zonas no controladas, sobretodo bajo crestas y collados orientados a Este y Sureste.

Distribución del manto nivoso

Hay nieve en el suelo por encima de 1.400-1500 m. Sin embargo, el manto es esquiable por encima de 1.500-1.600 m. Los grosores alcanzan los 130-150 cm a 2.200 m. Son grosores muy por encima de los habituales por la época.

Tendencia para las próximas 48-72h

Se mantendrá el viento en cota alta y caerán nuevos chubascos de nieve. Las placas se mantendrán reactivas. Peligro ESTACIONARIO O EN LEVE DESCENSO.

El próximo boletín será emitido el día 2026-02-17

5 MUY FUERTE	4 FUERTE	3 NOTABLE	2 LIMITADO	1 DÉBIL

EAWS EUROPEAN AVALANCHE WARNING SERVICES

ICGC Institut Cartogràfic i Geològic de Catalunya

Servei Meteorològic de Catalunya meteo.cat

Boletín de peligro de aludes Vessant Nord Cadí-Moixeró Del 16/02/2026 al 17/02/2026

(Válido fuera pistas de esquí y zonas no controladas)

MODERADO (2). NOTABLE (3), en lo alto de las Canales.

Situación primaria

Nieve venteada

Distribución

Tamaño

Origen

Tendencia

Situación secundaria

Nieve húmeda

Distribución

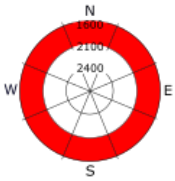

Tamaño

Origen

Tendencia

Estado del manto nivoso

Con los últimos chubascos y el viento, en cota alta, se habrán formado placas, a sotavento del viento predominante. El problema principal será, por tanto, el de las placas de viento, que las encontraremos en vertientes Este, Norte y Sur. Si se rompen las placas, al paso de un montañero, podrán generar aludes de pequeño tamaño, sin capacidad para enterrar a una persona y allí donde haya más acumulación, podrá caer algún alud de tamaño medio (que podría enterrar a un montañero), sobre todo en terreno trampa. Habrá que ir con copto en lo alto de las Canales del Cadí, donde podremos encontrar alguna nueva placa de reciente formación. Con el humedecimiento del manto, por debajo de los 2.100 m, podrá caer alguna purga de nieve húmeda en terreno inclinado. Se recomienda mucha prudencia y experiencia si se debe circular por zonas no controladas, especialmente debajo de collados, cordales oa la salida de las Canales.

Distribución del manto nivoso

Hay nieve desde 1.300 m. Norte y desde 1.400 a 1500 m. Sur, esquiable por encima de unos 1.500 m. Los grosores están alrededor de 150-170 cm a 2.200 m. Estos valores son muy excedentarios para la época del año.

Tendencia para las próximas 48-72h

Se mantendrá el viento en cota alta y caerán nuevos chubascos de nieve. Las placas se mantendrán reactivas. Peligro ESTACIONARIO o EN LEVE DESCENSO.

El próximo boletín será emitido el día 2026-02-17

5 MUY FUERTE	4 FUERTE	3 NOTABLE	2 LIMITADO	1 DÉBIL

EAWS EUROPEAN AVALANCHE WARNING SERVICES

ICGC Institut Cartogràfic i Geològic de Catalunya

meteo.cat Servei Meteorològic de Catalunya

Boletín de peligro de aludes Prepirineu
Del 16/02/2026 al 17/02/2026

(Válido fuera pistas de esquí y zonas no controladas)

LIMITADO (2).

Situación primaria

Nieve venteada

Distribución

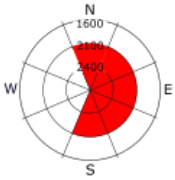

Tamaño

Origen

Tendencia

Situación secundaria

Nieve húmeda

Distribución

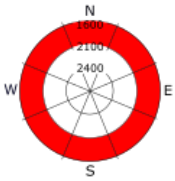

Tamaño

Origen

Tendencia

Estado del manto nivoso

Con los últimos chubascos y el viento, en cota alta, se habrán formado placas, a sotavento del viento predominante. El problema principal será, por tanto, el de las placas de viento, que las encontraremos en vertientes Este, Norte y Sur. Si se rompen las placas, al paso de un montañero, podrán generar aludes de pequeño tamaño, sin capacidad para enterrar a una persona y allí donde haya más acumulación, podrá caer algún alud de tamaño medio (que podría enterrar a un montañero), sobre todo en terreno trampa. Con el humedecimiento del manto, por debajo de los 2.100 m, podrá caer alguna purga de nieve húmeda, en terreno inclinado. Se recomienda mucha prudencia y experiencia si se debe circular por zonas no controladas, especialmente debajo de collados y cordales.

Distribución del manto nivoso

Hay nieve desde 1400-1500 m. El manto es esquiable a partir de 1600 m. Los grosores están alrededor de 110-130 cm a unos 2.200 m y son superiores a los habituales.

Tendencia para las próximas 48-72h

Se mantendrá el viento en cota alta y caerán nuevos chubascos de nieve. Las placas se mantendrán reactivas. Peligro ESTACIONARIO o EN LEVE DESCENSO.

El próximo boletín será emitido el día 2026-02-17

5 MUY FUERTE	4 FUERTE	3 NOTABLE	2 LIMITADO	1 DÉBIL

EAWS EUROPEAN AVALANCHE WARNING SERVICES

ICGC Institut Cartogràfic i Geològic de Catalunya

meteo.cat Servei Meteorològic de Catalunya

Boletín de peligro de aludes Ter-Freser
Del 16/02/2026 al 17/02/2026

(Válido fuera pistas de esquí y zonas no controladas)

LIMITADO (2), por debajo de 2.400 m.
NOTABLE (3), en el resto

Situación primaria

Nieve venteada

Distribución

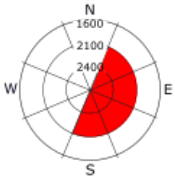

Tamaño

Origen

Tendencia

Situación secundaria

Nieve húmeda

Distribución

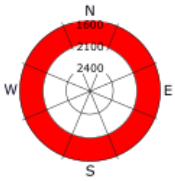

Tamaño

Origen

Tendencia

Estado del manto nivoso

El fuerte viento del noroeste ha transportado la nieve seca de la última nevada, generando nuevas placas. El martes continuaremos con el problema de las placas de viento. Las encontraremos a sotavento del viento predominante del Norte y serán muy frágiles. Podrán caer de forma natural o al paso de un esquiador y generar aludes de hasta tamaño medio (con capacidad de enterrar a una persona). Los lugares donde se formarán serán, sobre todo, en Nordeste, Sudeste y Este, por encima de los 2.400 m. Los lugares peligrosos serán bajo collados y cordales, y terreno con convexidades. En las laderas muy inclinadas, con el reciente humedecimiento del manto, podrán caer purgas de nieve húmeda, de pequeño tamaño y también medio, por debajo de los 2.100 m. Se recomienda mucha prudencia y experiencia si se debe circular por zonas no controladas, en especial bajo collados y cordales.

Distribución del manto nivoso

El manto nivoso presenta grosores muy excedentarios para la época del año. En lugares no afectados por el viento, los espesores oscilan entre 100-140 cm a unos 2.000 m, siendo esquiable a partir de unos 1.500 m.

Tendencia para las próximas 48-72h

Se mantendrá el viento en cota alta y caerán nuevos chubascos de nieve. Las placas se mantendrán reactivas. Peligro ESTACIONARIO o EN LEVE DESCENSO.

El próximo boletín será emitido el día 2026-02-17

5 MUY FUERTE	4 FUERTE	3 NOTABLE	2 LIMITADO	1 DÉBIL

EAWS EUROPEAN AVALANCHE WARNING SERVICES