BUTLLETÍ DEL PERILL D'ALLAUS DEL PRINCIPAT D'ANDORRA

Servei meteorològic nacional
Principat d'Andorra

Elaborado el 16/02/2026 16:00
Proxima actualización 17/02/2026 a las 16h

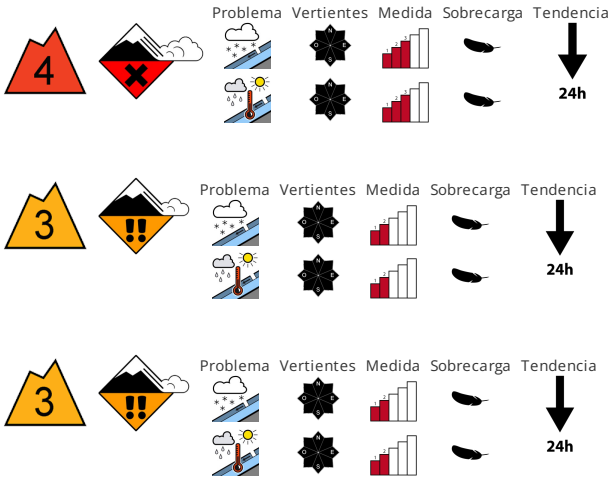

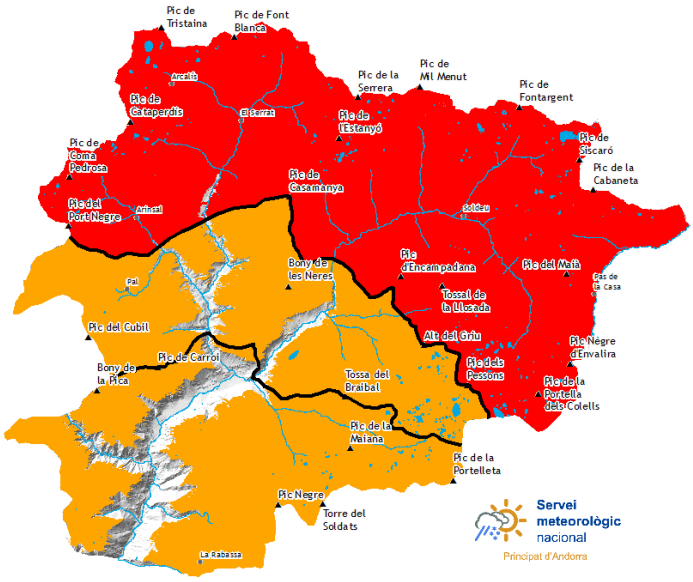

CALIDAD DE LA NIEVE

La nieve reciente y la nieve venteada de los últimos tres días deben ser evaluadas con cautela. Especialmente en los sectores más afectados por las precipitaciones son son probables aludes naturales de tamaño mediano y, locamente, grande. Con el fin de las precipitaciones, progresivo descenso del peligro de aludes de nieve húmeda. Las condiciones son peligrosas para las excursiones y las actividades fuera pista. Se recomienda una elección cuidadosa de la ruta y mantener la distancia de seguridad entre los miembros del grupo. Tras el período de mal tiempo, en este primer día de sol se recomienda prudencia.

ESTABILIDAD DEL MANTO NIVOSO

Con la nieve reciente y el viento las placas de viento han aumentado de tamaño. Esta nieve debe ser evaluada con cautela. Hasta el final de la tarde caerá lluvia hasta en cotas altas especialmente en los norte. La lluvia causará en un área extensa en particular en cotas bajas y medias una humidificación del manto de nieve. El enfriamiento nocturno será bastante bueno. Debido a la costra de hielo hay el peligro de resbalar y caer. En cotas altas :. La nieve reciente se volverá progresivamente más inestable laderas solanas .

ESPESORES DEL MANTO NIVOSO FUERA DE PISTA

Zona norte		Espesor nieve		
Manto Nival		1500m	2000m	2500m
N	1300 m	50 cm	150 cm	200 cm
S	1400 m	30 cm	100 cm	150 cm

zona centro		Espesor nieve		
Manto Nival		1500m	2000m	2500m
N	1300 m	30 cm	150 cm	200 cm
S	1400 m	10 cm	100 cm	150 cm

Zona sur		Espesor nieve		
Manto Nival		1500m	2000m	2500m
N	1300 m	30 cm	120 cm	150 cm
S	1400 m	10 cm	60 cm	100 cm

Govern d'Andorra

EAWS EUROPEAN AVALANCHE WARNING SERVICES

Aquest butlletí ha estat elaborat seguint les normes i recomanacions de l'**European Avalanche Warning Services**, del qual el **Servei meteorològic Nacional** n'és membre

Información detallada por espacios naturales protegidos

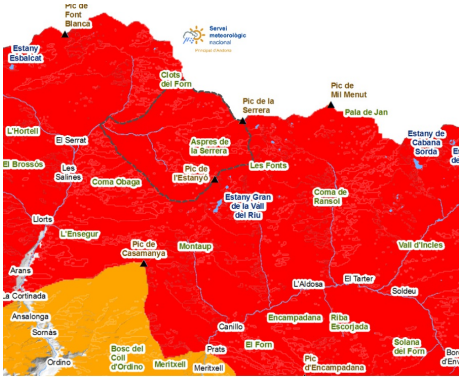

SORTENY

Las nevadas del fin de semana han sido consecuentes y han dejado espesores de nieve nueva superiores a los 50 cm, moldeados por el viento. La lluvia humidificará el manto hasta cotas medias y la sobrecarga puede bajar aludes de manera natural Las actividades fuera de las pistas controladas requieren experiencia y mucho cuidado en la elección del territorio.

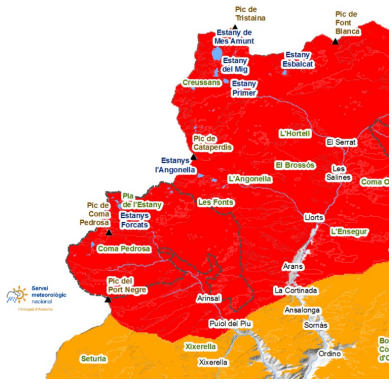

COMAPEDROSA

Las actividades en la montaña son desaconsejables hasta que la nieve reciente se haya estabilizado. Se esperan numerosos aludes naturales.

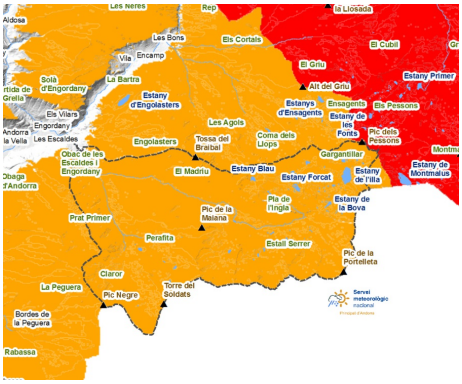

MADRIU-PERAFITA-CLAROR

En la parte alta del Madriu también ha nevado, aunque las nevadas en el sur del país han sido menos intensas, también esperamos la formación de placas de viento. La lluvia humifdificará la nieve reciente en las cotas bajas dificultando los accesos a esquís.

BUTLLETÍ DEL PERILL D'ALLAUS DEL PRINCIPAT D'ANDORRA

Servei meteorològic nacional
Principat d'Andorra

Espesores de nieve nueva de los últimos días (de las ultimas 24h mesurado a las 06:00h UTC)

	12/02/2026	13/02/2026	14/02/2026	15/02/2026
FEDA (Central)	0 cm	0 cm	0 cm	0 cm
Engolasters - FEDA	0 cm	10 cm	3 cm	0 cm
Bony de les Neres	0 cm	14 cm	0 cm	0 cm
Sorteny	0 cm	36 cm	0 cm	2 cm
Les Fonts d'Arinsal	0 cm	18 cm	0 cm	0 cm
Perafita	0 cm	0 cm	12 cm	0 cm
Tossa Espiolets	0 cm	8 cm	3 cm	56 cm
Grau Roig - FEDA	0 cm	10 cm	0 cm	0 cm
Fontverd	0 cm	8 cm	13 cm	0 cm
Ransol - FEDA	0 cm	13 cm	2 cm	0 cm
Setúria	0 cm	8 cm	0 cm	0 cm
Caborreu	0 cm	8 cm	0 cm	4 cm
Envalira Antenes	0 cm	6 cm	8 cm	0 cm