BUTLLETÍ DEL PERILL D'ALLAUS DEL PRINCIPAT D'ANDORRA

Préparé le 16/02/2026 16:00
Prochaine mise à jour le 17/02/2026 à 16h

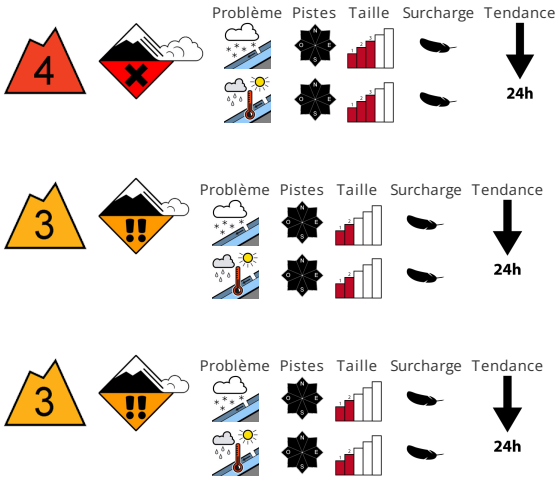

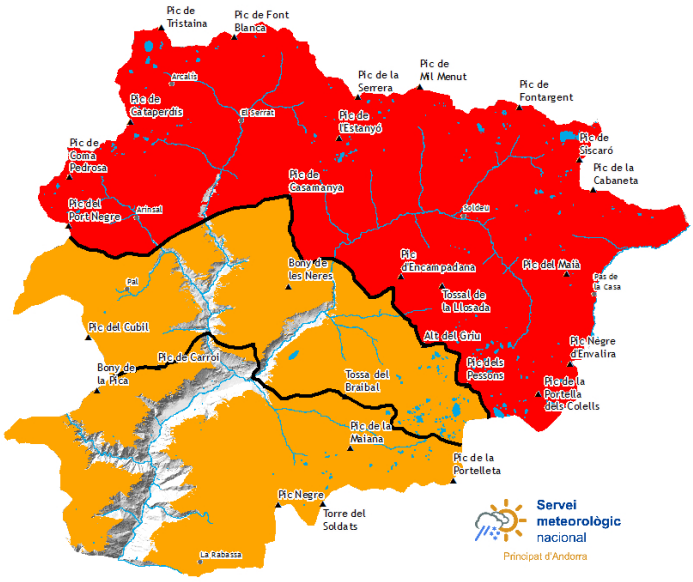

STABILITÉ DU MANTEAU NEIGEUX

La neige fraîche et la neige soufflée des trois derniers jours doivent être évaluées avec précaution. Des avalanches spontanées de moyenne et rarement grande taille sont à attendre spécialement dans les régions concernées par les précipitations principales. Diminution progressive du danger d'avalanches humides avec la fin des précipitations. Pour des randonnées et descentes hors-piste les conditions sont dangereuses. Un choix prudent d'itinéraire et des distances de délestage sont recommandés.. Après une longue période de mauvais temps, la retenue est de mise pour cette première journée ensoleillée..

QUALITÈ DE LA NEIGE

Les accumulations de neige soufflée se sont avec la neige fraîche et le vent. Elle doit être évaluée avec précaution. Jusqu'au soir il tombera de la pluie jusqu'à haute altitude spécialement au nord. La pluie entraîne surtout à basse et moyenne altitude généralement une humidification du manteau neigeux. Le rayonnement nocturne est assez bon.. Sur la croûte glacée il existe un risque de chute.. À haute altitude (-):. La neige fraîche devient de plus en plus fragile ensoleillées.

EPAISSEUR DE NEIGE HORS PISTE

Zone nord		Epaisseur de neige		
Nival manteau		1500m	2000m	2500m
N	1300 m	50 cm	150 cm	200 cm
S	1400 m	30 cm	100 cm	150 cm

Zone centre		Epaisseur de neige		
Nival manteau		1500m	2000m	2500m
N	1300 m	30 cm	150 cm	200 cm
S	1400 m	10 cm	100 cm	150 cm

Zone sud		Epaisseur de neige		
Nival manteau		1500m	2000m	2500m
N	1300 m	30 cm	120 cm	150 cm
S	1400 m	10 cm	60 cm	100 cm

Govern d'Andorra

EAWS EUROPEAN AVALANCHE WARNING SERVICES

Aquest butlletí ha estat elaborat seguint les normes i recomanacions de l'**European Avalanche Warning Services**, del qual el **Servei meteorològic Nacional** n'és membre

BUTLLETÍ DEL PERILL D'ALLAUS DEL PRINCIPAT D'ANDORRA

Servei meteorològic nacional
Principat d'Andorra

Des informations détaillées par espace naturel protégé

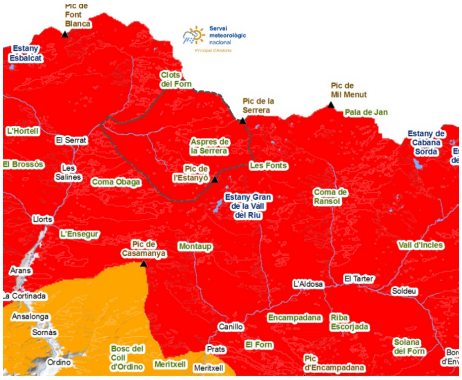

SORTENY

Les chutes de neige du week-end ont été constantes et ont laissé des épaisseurs de neige fraîche supérieures à 50 cm, façonnées par le vent. La pluie humidifiera le manteau jusqu'à des niveaux moyens et la surcharge pourra faire tomber les avalanches de manière naturelle. Les activités en dehors des pistes contrôlées nécessitent de l'expérience et un grand soin dans le choix du territoire. , , ,

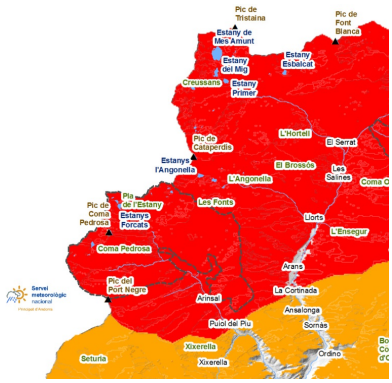

COMAPEDROSA

Les activités de montagne ne sont pas recommandées tant que la neige récente n'est pas stabilisée. De nombreuses avalanches naturelles sont attendues. , , ,

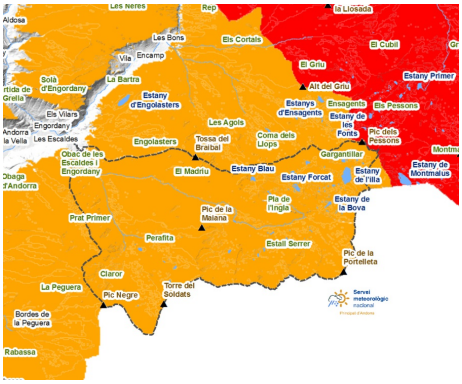

MADRIU-PERAFITA-CLAROR

Il y a aussi de la neige dans la partie supérieure du Madriu, même si les chutes de neige dans le sud du pays ont été moins intenses, on s'attend également à la formation de plaques de vent. La pluie humidifiera la neige récente à basse altitude, rendant l'accès à skis difficile. , , ,

Govern d'Andorra

EAWS
EUROPEAN AVALANCHE WARNING SERVICES

Aquest butlletí ha estat elaborat seguint les normes i recomanacions de l'**European Avalanche Warning Services**, del qual el **Servei meteorològic Nacional** n'és membre

BUTLLETÍ DEL PERILL D'ALLAUS DEL PRINCIPAT D'ANDORRA

Servei meteorològic nacional
Principat d'Andorra

Couche de neige fraiche des derniers jours (De 24 h mesurée à 06:00 h UTC)

	12/02/2026	13/02/2026	14/02/2026	15/02/2026
FEDA (Central)	0 cm	0 cm	0 cm	0 cm
Engolasters - FEDA	0 cm	10 cm	3 cm	0 cm
Bony de les Neres	0 cm	14 cm	0 cm	0 cm
Sorteny	0 cm	36 cm	0 cm	2 cm
Les Fonts d'Arinsal	0 cm	18 cm	0 cm	0 cm
Perafita	0 cm	0 cm	12 cm	0 cm
Tossa Espiolets	0 cm	8 cm	3 cm	56 cm
Grau Roig - FEDA	0 cm	10 cm	0 cm	0 cm
Fontverd	0 cm	8 cm	13 cm	0 cm
Ransol - FEDA	0 cm	13 cm	2 cm	0 cm
Setúria	0 cm	8 cm	0 cm	0 cm
Caborreu	0 cm	8 cm	0 cm	4 cm
Envalira Antenes	0 cm	6 cm	8 cm	0 cm