ALPI GIULIE

Bollettino Valanghe N. 348/2026 del 16/02/2026 ore 14.00
Validità 48 ore prossima emissione 17/02/2026
A cura del Servizio METEOMONT dell'ARMA dei CARABINIERI
In collaborazione con Servizio Meteorologico dell'Aeronautica militare

SITUAZIONE alle 14:00 del 16/02/2026

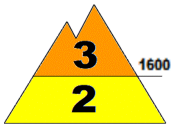

SITUAZIONE TIPO: neve a debole coesione e vento.

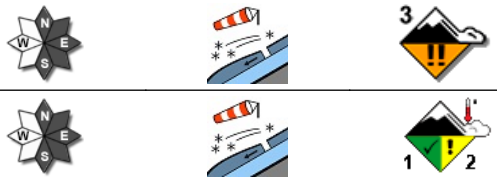

SITUAZIONE TIPO: neve a debole coesione e vento.

Quota neve (mslm)	Nord	Sud
	700 - 900	1000 - 1200

Altezza Neve (cm)	Neve al suolo	Neve Fresca	Quota (mslm)
	120	999	1750
	123	00	1530

VALANGHE OSSERVATE: Nessuna valanga.

PREVISIONI 17/02/2026

GRADO DI PERICOLO: MARCATO 3

SITUAZIONE TIPO: neve a debole coesione e vento.

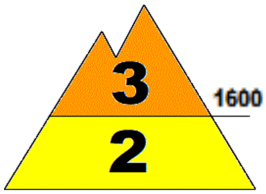

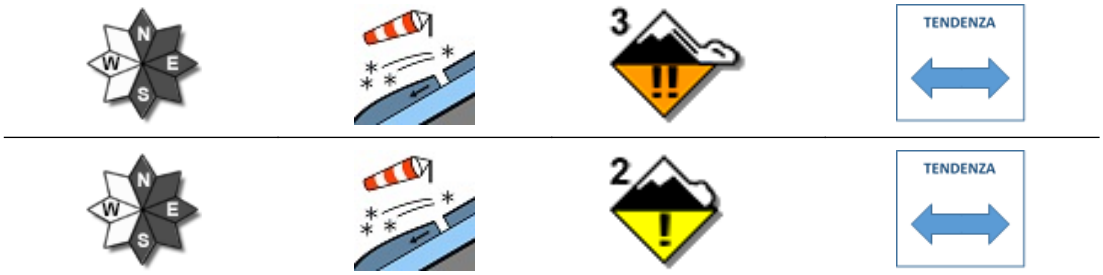

SITUAZIONE TIPO: neve a debole coesione e vento.

MANTO NEVOSO: La stabilità del manto nevoso è scarsa su molti punti (aree) per versanti da nord a sud compresi al di sopra di 1600 mslm, possibili valanghe di dimensioni medie.
La stabilità del manto nevoso è scarsa su pochi punti (aree) per versanti da nord a sud compresi al di sotto di 1600 mslm, possibili valanghe di dimensioni medie.

AVVERTENZE

A seguito dell'attività eolica registrata sono da evitare le zone di accumulo, conche, canaloni, cambi di pendenza e pendii sotto vento in genere.

SCALA EUROPEA DEL GRADO DI PERICOLO VALANGHE

LEGENDA PROBLEMA

Bollettino realizzato su scala sinottica-regionale (standard EAWS). La sua valutazione non può escludere in alcun modo la necessità di una seria e capace valutazione locale del pericolo (singolo pendio) che può essere anche sensibilmente diverso. Le previsioni meteorologiche sono relative all'orario UTC (per l'Italia +1 in inverno e +2 in estate).

MINISTERO DELLA DIFESA

meteomont
Servizio Nazionale di previsione neve e valanghe

EAWS EUROPEAN AVALANCHE WARNING SERVICES

CARABINIERI

ALPI GIULIE

PREVISIONE METEO

Quota		17/02/2026 h6:00	17/02/2026 h12:00	17/02/2026 h18:00
1000	Venti	02 Nodi da Ovest	01 nodi da N-Ovest	01 Nodi da Nord
	Temperature	-01 °C	-01 °C	-01 °C
	Temp.percepita	-1 °C	-1 °C	-1 °C
2000	Venti	06 nodi da N-Ovest	09 nodi da N-Ovest	04 nodi da N-Ovest
	Temperature	-06 °C	-07 °C	-07 °C
	Temp.percepita	-11 °C	-13 °C	-11 °C
3000	Venti	15 nodi da N-Ovest	16 nodi da N-Ovest	15 nodi da N-Ovest
	Temperature	-13 °C	-14 °C	-14 °C
	Temp.percepita	-23 °C	-25 °C	-24 °C
Zero termico		0700-0900 m.	1200-1400 m.	0800-1000 m.
Fenomeno		—	—	—
Stato del cielo				

LEGENDA FENOMENI

— Assenza Fenomeni · Nebbia · Foschia · Pioggia debole · Pioggia moderata · Pioggia forte · Temporali

Nevicata debole · Nevicata moderata · Nevicata forte

STATO DEL CIELO

Sereno · Poco nuvoloso · Nuvoloso · Molto nuvoloso · Coperto

Parametri meteonivometrici registrati presso i campi di rilevamento il 16/02/2026.

Località	Comune	Quota (m.s.l.m.)	Altezza neve (cm)	Neve caduta nelle 24 ore (cm)	Temp. Min (°C)	Temp. Max (°C)	Condizioni del tempo
MALBORGHETTO - VAL SAISERA	Tarvisio (UD)	875	42	0	-4	+7	Assenza di precipitazioni
PASSO PRAMOLLO	Pontebba (UD)	1530	123	Tracce di neve	-9	+5	Assenza di precipitazioni
MONTE LUSSARI	Tarvisio (UD)	1750	120	0	-8	+5	Assenza di precipitazioni
PASSO PREDIL	Tarvisio (UD)	1130	72	Tracce di neve	-5	+1	Rovescio di neve misto a pioggia

(*) Rilievi fuori campo

L'INFORMAZIONE E' PREVENZIONE - LEGGI L'ATTUALE GRADO DI PERICOLO VALANGHE!

IL CAPO DEL CENTRO NAZIONALE METEOMONT
(Ten. Col. RFI Emanuela Gini)
FIRMA AUTOGRAFA OMESSA AI SENSI
DELL'ART.3 DEL D.LGS N.39/1993

Bollettino realizzato su scala sinottica-regionale (standard EAWS). La sua valutazione non può escludere in alcun modo la necessità di una seria e capace valutazione locale del pericolo (singolo pendio) che può essere anche sensibilmente diverso. Le previsioni meteorologiche sono relative all'orario UTC (per l'Italia +1 in inverno e +2 in estate).