MINISTERO DELLA DIFESA

meteomont
Servizio Nazionale di previsione neve e valanghe

EAWS EUROPEAN AVALANCHE WARNING SERVICES

CARABINIERI

ALPI RETICHE

Bollettino Valanghe N. 349/2026 del 16/02/2026 ore 14.00
Validità 48 ore prossima emissione 17/02/2026
A cura del Servizio METEOMONT dell'ARMA dei CARABINIERI
In collaborazione con Servizio Meteorologico dell'Aeronautica militare

SITUAZIONE alle 14:00 del 16/02/2026

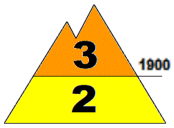

SITUAZIONE TIPO: strato debole persistente basale.

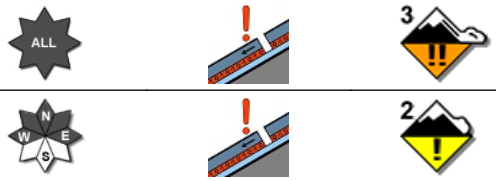

SITUAZIONE TIPO: passaggio da poca a molta neve.

Quota neve (mslm)	Nord	Sud
	700 - 900	700 - 900

Altezza Neve (cm)	Neve al suolo	Neve Fresca	Quota (mslm)
	65	14	2150
	038	2	1580

VALANGHE OSSERVATE: Alcune valanghe di medie dimensioni, Valanghe di neve a debole coesione di superficie.

PREVISIONI 17/02/2026

GRADO DI PERICOLO: MARCATO 3

SITUAZIONE TIPO: strato debole persistente basale.

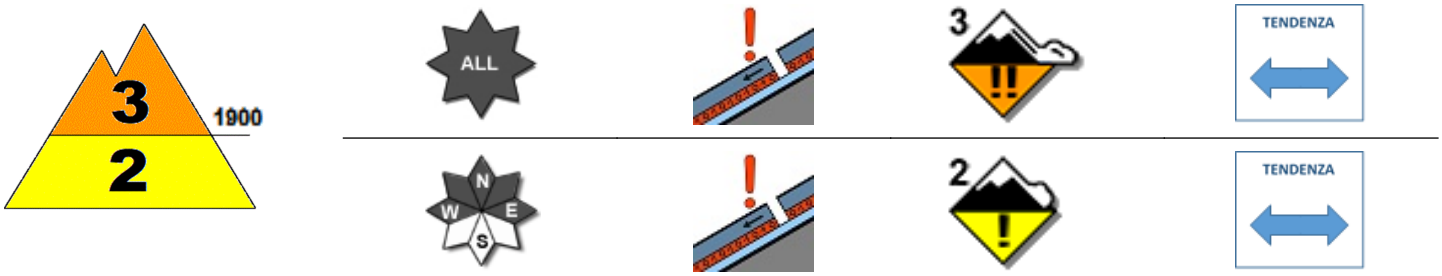

SITUAZIONE TIPO: passaggio da poca a molta neve.

MANTO NEVOSO: La stabilità del manto nevoso è scarsa su molti punti (aree) per tutte le esposizioni al di sopra di 1900 mslm, possibili valanghe di dimensioni medie.
La stabilità del manto nevoso è scarsa su alcuni punti (aree) per versanti da ovest a est al di sotto di 1900 mslm, possibili valanghe di dimensioni medie.

AVVERTENZE

A seguito dell'attività eolica registrata sono da evitare le zone di accumulo, conche, canaloni, cambi di pendenza e pendii sotto vento in genere.

SCALA EUROPEA DEL GRADO DI PERICOLO VALANGHE

LEGENDA PROBLEMA

Bollettino realizzato su scala sinottica-regionale (standard EAWS). La sua valutazione non può escludere in alcun modo la necessità di una seria e capace valutazione locale del pericolo (singolo pendio) che può essere anche sensibilmente diverso. Le previsioni meteorologiche sono relative all'orario UTC (per l'Italia +1 in inverno e +2 in estate).

MINISTERO DELLA DIFESA

meteomont
Servizio Nazionale di previsione neve e valanghe

EAWS EUROPEAN AVALANCHE WARNING SERVICES

CARABINIERI

ALPI RETICHE

PREVISIONE METEO

Quota		17/02/2026 h6:00	17/02/2026 h12:00	17/02/2026 h18:00
1000	Venti	01 nodi da N-Ovest	02 Nodi da Ovest	04 nodi da N-Ovest
	Temperature	-08 °C	-05 °C	-08 °C
	Temp.percepita	-8 °C	-5 °C	-12 °C
2000	Venti	01 nodi da N-Ovest	02 Nodi da Ovest	04 nodi da N-Ovest
	Temperature	-08 °C	-05 °C	-08 °C
	Temp.percepita	-8 °C	-5 °C	-12 °C
3000	Venti	07 nodi da N-Ovest	14 nodi da N-Ovest	20 nodi da N-Ovest
	Temperature	-14 °C	-13 °C	-16 °C
	Temp.percepita	-21 °C	-23 °C	-28 °C
Zero termico		0600-0800 m.	1000-1200 m.	0800-1000 m.
Fenomeno				—
Stato del cielo				

LEGENDA FENOMENI

— Assenza Fenomeni · Nebbia · Foschia · Pioggia debole · Pioggia moderata · Pioggia forte · Temporali

Nevicata debole · Nevicata moderata · Nevicata forte

STATO DEL CIELO

Sereno · Poco nuvoloso · Nuvoloso · Molto nuvoloso · Coperto

Parametri meteonivometrici registrati presso i campi di rilevamento il 16/02/2026.

Località	Comune	Quota (m.s.l.m.)	Altezza neve (cm)	Neve caduta nelle 24 ore (cm)	Temp. Min (°C)	Temp. Max (°C)	Condizioni del tempo
SPONDA	Livigno (SO)	2150	65	14	-7	-1	Nevicata moderata
BORMIO2000-LECCIONA	Valdisotto (SO)	2050	60	9	-6	-1	Nevicata forte
VALAR	Valdidentro (SO)	1930	70	11	-10	+0	Nevicata debole continua
DOSSO DEL VALLONE	Valfurva (SO)	2582	64	2	-13	-6	Nevicata moderata
ALPE PALU'	Chiesa in Valmalenco (SO)	2010	79	8	-7	+1	Nevicata moderata
PREDA	Edolo (BS)	1580	38	2	-5	+4	Assenza di precipitazioni
COLONIA VIGILI	Ponte di Legno (BS)	1640	58	2	-6	+5	Assenza di precipitazioni
PISTA STELVIO *	Valdisotto (SO)	2140	71	10	-6	-1	Nevicata moderata

(*) Rilievi fuori campo

L'INFORMAZIONE E' PREVENZIONE - LEGGI L'ATTUALE GRADO DI PERICOLO VALANGHE!

IL CAPO DEL CENTRO NAZIONALE METEOMONT
(Ten. Col. RFI Emanuela Gini)
FIRMA AUTOGRAFA OMESSA AI SENSI
DELL'ART.3 DEL D.LGS N.39/1993

Bollettino realizzato su scala sinottica-regionale (standard EAWS). La sua valutazione non può escludere in alcun modo la necessità di una seria e capace valutazione locale del pericolo (singolo pendio) che può essere anche sensibilmente diverso. Le previsioni meteorologiche sono relative all'orario UTC (per l'Italia +1 in inverno e +2 in estate).