MINISTERO DELLA DIFESA

meteomont
Servizio Nazionale di previsione neve e valanghe

EAWS EUROPEAN AVALANCHE WARNING SERVICES

CARABINIERI

ALPI COZIE SUD

Bollettino Valanghe N. 346/2026 del 15/02/2026 ore 14.00
Validità 48 ore prossima emissione 16/02/2026
A cura del Servizio METEOMONT dell'ARMA dei CARABINIERI
In collaborazione con Servizio Meteorologico dell'Aeronautica militare

SITUAZIONE alle 14:00 del 15/02/2026

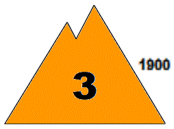

SITUAZIONE TIPO: neve a debole coesione e vento.



SITUAZIONE TIPO: neve a debole coesione e vento.

	Nord	Sud
Quota neve (mslm)	*900 - 1000*	*1200 - 1400*

	Neve al suolo	Neve Fresca	Quota (mslm)
Altezza Neve (cm)	*136*	*000*	*2135*
	86	*013*	*1770*

VALANGHE OSSERVATE: Nessuna valanga.

PREVISIONI 16/02/2026

GRADO DI PERICOLO: MARCATO 3

SITUAZIONE TIPO: neve a debole coesione e vento.



SITUAZIONE TIPO: neve a debole coesione e vento.

MANTO NEVOSO: La stabilità del manto nevoso è scarsa su molti punti (aree) per tutte le esposizioni al di sopra di 1800 mslm, possibili valanghe di dimensioni medie.
La stabilità del manto nevoso è scarsa su alcuni punti (aree) per tutte le esposizioni al di sotto di 1800 mslm, possibili valanghe di dimensioni medie.

AVVERTENZE

In considerazione delle avverse condizioni meteorologiche previste , le attività al di fuori delle piste battute e segnalate sono sconsigliate.

SCALA EUROPEA DEL GRADO DI PERICOLO VALANGHE

5 - MOLTO FORTE | *4 - FORTE* | *3 - MARCATO* | *2 - MODERATO* | *1 - DEBOLE* | NO NEVE *NO NEVE* | *NO INFO*

LEGENDA PROBLEMA

NEVE FRESCA | *LASTRONI DA VENTO* | *STRATI DEBOLI PERSISTENTI* | *NEVE BAGNATA* | *SLITTAMENTO* | *CORNICI* | *NESSUN PROBLEMA VALANGHIVO EVIDENTE* | *NO_INFO*

Bollettino realizzato su scala sinottica-regionale (standard EAWS). La sua valutazione non può escludere in alcun modo la necessità di una seria e capace valutazione locale del pericolo (singolo pendio) che può essere anche sensibilmente diverso. Le previsioni meteorologiche sono relative all'orario UTC (per l'Italia +1 in inverno e +2 in estate).

MINISTERO DELLA DIFESA

meteomont
Servizio Nazionale di previsione neve e valanghe

EAWS EUROPEAN AVALANCHE WARNING SERVICES

CARABINIERI

ALPI COZIE SUD

PREVISIONE METEO

Quota		16/02/2026 h6:00	16/02/2026 h12:00	16/02/2026 h18:00
1000	Venti	03 Nodi da S-Ovest	04 Nodi da Ovest	02 nodi da Ovest
	Temperature	-01 °C	+00 °C	-03 °C
	Temp.percepita	-3 °C	-3 °C	-3 °C
2000	Venti	07 Nodi da S-Ovest	12 nodi da Ovest	07 nodi da N-Ovest
	Temperature	-01 °C	-01 °C	-04 °C
	Temp.percepita	-5 °C	-7 °C	-9 °C
3000	Venti	16 Nodi da Ovest	26 nodi da N-Ovest	25 nodi da N-Ovest
	Temperature	-08 °C	-09 °C	-12 °C
	Temp.percepita	-17 °C	-20 °C	-24 °C
Zero termico		1100-1300 m.	1800-2000 m.	1100-1300 m.
Fenomeno			—	
Stato del cielo				

LEGENDA FENOMENI

Assenza Fenomeni — Nebbia — Foschia — Pioggia debole — Pioggia moderata — Pioggia forte — Temporali

Nevicata debole — Nevicata moderata — Nevicata forte

STATO DEL CIELO

Sereno — Poco nuvoloso — Nuvoloso — Molto nuvoloso — Coperto

Parametri meteonivometrici registrati presso i campi di rilevamento il 15/02/2026.

Località	Comune	Quota (m.s.l.m.)	Altezza neve (cm)	Neve caduta nelle 24 ore (cm)	Temp. Min (°C)	Temp. Max (°C)	Condizioni del tempo
BORGATA CHIESA	Bellino (CN)	1480	78	2	N.P.	N.P.	Assenza di precipitazioni

(*) Rilievi fuori campo

L'INFORMAZIONE E' PREVENZIONE - LEGGI L'ATTUALE GRADO DI PERICOLO VALANGHE!

IL CAPO DEL CENTRO NAZIONALE METEOMONT
(Ten. Col. RFI Emanuela Gini)
FIRMA AUTOGRAFA OMESSA AI SENSI
DELL'ART.3 DEL D.LGS N.39/1993