MINISTERO DELLA DIFESA

meteomont Servizio Nazionale di previsione neve e valanghe

EAWS EUROPEAN AVALANCHE WARNING SERVICES

CARABINIERI

# ALPI MARITTIME

Bollettino Valanghe N. 347/2026 del 16/02/2026 ore 14.00
Validità 48 ore prossima emissione 17/02/2026

**A cura del Servizio METEOMONT dell'ARMA dei CARABINIERI**
**In collaborazione con Servizio Meteorologico dell'Aeronautica militare**

## SITUAZIONE alle 14:00 del 16/02/2026

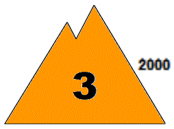


**SITUAZIONE TIPO: neve a debole coesione e vento.**




**SITUAZIONE TIPO: neve da slittamento.**

| Quota neve (mslm) | Nord | Sud |
|---|---|---|
| | 700 - 800 | 800 - 900 |

| Altezza Neve (cm) | Neve al suolo | Neve Fresca | Quota (mslm) |
|---|---|---|---|
| | 178 | 000 | 2020 |
| | 179 | 000 | 1390 |

**VALANGHE OSSERVATE: -.**

## PREVISIONI 17/02/2026

# GRADO DI PERICOLO: MARCATO 3

## SITUAZIONE TIPO: neve a debole coesione e vento.

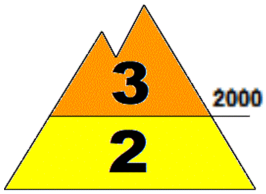


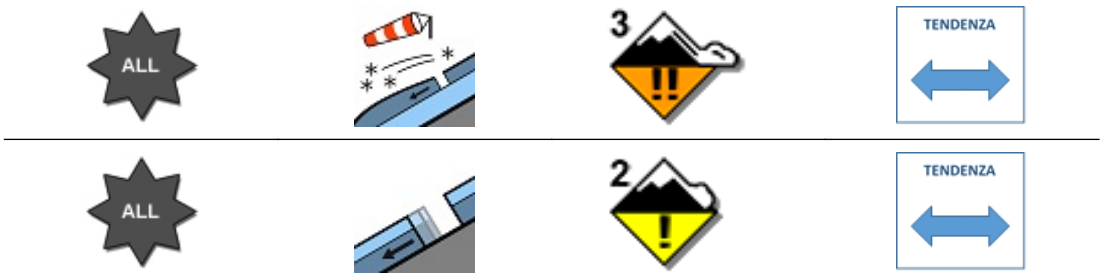


## SITUAZIONE TIPO: neve da slittamento.

**MANTO NEVOSO: La stabilità del manto nevoso è molto scarsa su molti punti (aree) per tutte le esposizioni al di sopra di 2000 mslm, possibili valanghe di dimensioni medie.**
**La stabilità del manto nevoso è scarsa su alcuni punti (aree) per tutte le esposizioni al di sotto di 2000 mslm, possibili valanghe di dimensioni medie.**

## AVVERTENZE

Viste le condizioni del manto nevoso, le attività al di fuori delle piste battute e segnalate richiedono ottime capacità di valutazione del pericolo locale.

## SCALA EUROPEA DEL GRADO DI PERICOLO VALANGHE

## LEGENDA PROBLEMA

**Bollettino realizzato su scala sinottica-regionale (standard EAWS). La sua valutazione non può escludere in alcun modo la necessità di una seria e capace valutazione locale del pericolo (singolo pendio) che può essere anche sensibilmente diverso. Le previsioni meteorologiche sono relative all'orario UTC (per l'Italia +1 in inverno e +2 in estate).**

MINISTERO DELLA DIFESA

meteomont
Servizio Nazionale di previsione neve e valanghe

EAWS EUROPEAN AVALANCHE WARNING SERVICES

CARABINIERI

# ALPI MARITTIME

## PREVISIONE METEO

| Quota | | 17/02/2026 h6:00 | 17/02/2026 h12:00 | 17/02/2026 h18:00 |
|---|---|---|---|---|
| 1000 | Venti | 05 Nodi da Ovest | 02 Nodi da Ovest | 02 Nodi da S-Ovest |
| | Temperature | +02 °C | +05 °C | +03 °C |
| | Temp.percepita | -1 °C | 5 °C | 3 °C |
| 2000 | Venti | 21 nodi da N-Ovest | 09 nodi da N-Ovest | 02 Nodi da S-Ovest |
| | Temperature | -02 °C | -03 °C | -03 °C |
| | Temp.percepita | -10 °C | -8 °C | -3 °C |
| 3000 | Venti | 24 Nodi da Nord | 27 nodi da N-Ovest | 21 nodi da N-Ovest |
| | Temperature | -09 °C | -10 °C | -09 °C |
| | Temp.percepita | -20 °C | -22 °C | -19 °C |
| Zero termico | | 1500-1700 m. | 1600-1800 m. | 1600-1800 m. |
| Fenomeno | | — | — | — |
| Stato del cielo | | | | |

## LEGENDA FENOMENI

— Assenza Fenomeni
Nebbia
Foschia
Pioggia debole
Pioggia moderata
Pioggia forte
Temporali
Nevicata debole
Nevicata moderata
Nevicata forte

## STATO DEL CIELO

Sereno
Poco nuvoloso
Nuvoloso
Molto nuvoloso
Coperto

**(*) Dati meteonivometrici non presenti.**

**L'INFORMAZIONE E' PREVENZIONE - LEGGI L'ATTUALE GRADO DI PERICOLO VALANGHE!**

**IL CAPO DEL CENTRO NAZIONALE METEOMONT**
**(Ten. Col. RFI Emanuela Gini)**
**FIRMA AUTOGRAFA OMESSA AI SENSI**
**DELL'ART.3 DEL D.LGS N.39/1993**