MINISTERO DELLA DIFESA

meteomont Servizio Nazionale di previsione neve e valanghe

EAWS EUROPEAN AVALANCHE WARNING SERVICES

CARABINIERI

APPENNINO EMILIANO CENTRALE

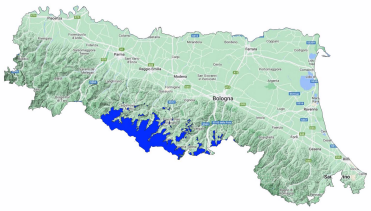

Bollettino Valanghe N. 320/2026 del 16/02/2026 ore 14.00
Validità 48 ore prossima emissione 17/02/2026

A cura del Servizio METEOMONT dell'ARMA dei CARABINIERI
In collaborazione con Servizio Meteorologico dell'Aeronautica militare

SITUAZIONE alle 14:00 del 16/02/2026

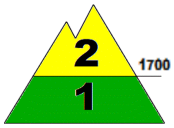

SITUAZIONE TIPO: neve a debole coesione e vento.



SITUAZIONE TIPO: situazione primaverile.

Quota neve (mslm)	Nord	Sud
	1300 - 1400	1400 - 1500

Altezza Neve (cm)	Neve al suolo	Neve Fresca	Quota (mslm)
	130	013	1840
	064	000	1550

VALANGHE OSSERVATE: Nessuna valanga.

PREVISIONI 17/02/2026

GRADO DI PERICOLO: MODERATO 2

SITUAZIONE TIPO: neve a debole coesione e vento.

SITUAZIONE TIPO: situazione primaverile.

MANTO NEVOSO: La stabilità del manto nevoso è scarsa su alcuni punti (aree) per versanti da sud a nord compresi al di sopra di 1700 mslm, possibili valanghe di dimensioni piccole.
La stabilità del manto nevoso è discreta su pochi punti (aree) per tutte le esposizioni al di sotto di 1700 mslm, possibili valanghe di dimensioni piccole.

AVVERTENZE

In considerazione delle avverse condizioni meteorologiche in atto, e della scarsa visibilità, risulterà difficoltosa l'individuazione dell'itinerario e della valutazione del singolo pendio.

SCALA EUROPEA DEL GRADO DI PERICOLO VALANGHE

LEGENDA PROBLEMA

Bollettino realizzato su scala sinottica-regionale (standard EAWS). La sua valutazione non può escludere in alcun modo la necessità di una seria e capace valutazione locale del pericolo (singolo pendio) che può essere anche sensibilmente diverso. Le previsioni meteorologiche sono relative all'orario UTC (per l'Italia +1 in inverno e +2 in estate).

APPENNINO EMILIANO CENTRALE

PREVISIONE METEO

Quota		17/02/2026 h6:00	17/02/2026 h12:00	17/02/2026 h18:00
1000	Venti	04 nodi da N-Ovest	05 nodi da N-Ovest	05 nodi da N-Ovest
	Temperature	+00 °C	+03 °C	+01 °C
	Temp.percepita	-3 °C	0 °C	-2 °C
2000	Venti	17 nodi da N-Ovest	15 nodi da N-Ovest	17 nodi da N-Ovest
	Temperature	-04 °C	-03 °C	-03 °C
	Temp.percepita	-12 °C	-10 °C	-11 °C
3000	Venti	19 Nodi da Nord	18 nodi da N-Ovest	18 nodi da N-Ovest
	Temperature	-11 °C	-10 °C	-11 °C
	Temp.percepita	-22 °C	-20 °C	-21 °C
Zero termico		1200-1400 m.	1400-1600 m.	1500-1700 m.
Fenomeno		—	—	—
Stato del cielo				

LEGENDA FENOMENI

— Assenza Fenomeni · Nebbia · Foschia · Pioggia debole · Pioggia moderata · Pioggia forte · Temporali

Nevicata debole · Nevicata moderata · Nevicata forte

STATO DEL CIELO

Sereno · Poco nuvoloso · Nuvoloso · Molto nuvoloso · Coperto

Parametri meteonivometrici registrati presso i campi di rilevamento il 16/02/2026.

Località	Comune	Quota (m.s.l.m.)	Altezza neve (cm)	Neve caduta nelle 24 ore (cm)	Temp. Min (°C)	Temp. Max (°C)	Condizioni del tempo
MONTE CUSNA	Villa Minozzo (RE)	1164	0	0	N.P.	N.P.	Assenza di precipitazioni
RIFUGIO CAVONE	Lizzano in Belvedere (BO)	1416	55	0	0	+4	Pioggia debole continua
LAGO DELLA NINFA	Sestola (MO)	1550	64	0	+1	+4	Assenza di precipitazioni
PIANCAVALLARO	Riolunato (MO)	1840	130	13	N.P.	N.P.	Nebbia con cielo visibile

(*) Rilievi fuori campo

L'INFORMAZIONE E' PREVENZIONE - LEGGI L'ATTUALE GRADO DI PERICOLO VALANGHE!

IL CAPO DEL CENTRO NAZIONALE METEOMONT
(Ten. Col. RFI Emanuela Gini)
FIRMA AUTOGRAFA OMESSA AI SENSI
DELL'ART.3 DEL D.LGS N.39/1993

Bollettino realizzato su scala sinottica-regionale (standard EAWS). La sua valutazione non può escludere in alcun modo la necessità di una seria e capace valutazione locale del pericolo (singolo pendio) che può essere anche sensibilmente diverso. Le previsioni meteorologiche sono relative all'orario UTC (per l'Italia +1 in inverno e +2 in estate).