MINISTERO DELLA DIFESA

meteomont
Servizio Nazionale di previsione neve e valanghe

EAWS EUROPEAN AVALANCHE WARNING SERVICES

CARABINIERI

AERONAUTICA MILITARE SERVIZIO METEOROLOGICO

TERMINILLO MONTI REATINI E LAGA OVEST

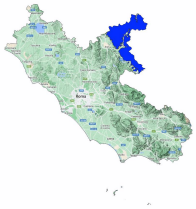

Bollettino Valanghe N. 289/2026 del 16/02/2026 ore 14.00
Validità 48 ore prossima emissione 17/02/2026

A cura del Servizio METEOMONT dell'ARMA dei CARABINIERI
In collaborazione con Servizio Meteorologico dell'Aeronautica militare

SITUAZIONE alle 14:00 del 16/02/2026

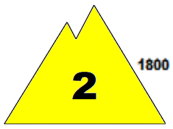

SITUAZIONE TIPO: neve a debole coesione e vento.



SITUAZIONE TIPO: situazione primaverile.

	Nord	Sud
Quota neve (mslm)	1700	1700 - 1800

	Neve al suolo	Neve Fresca	Quota (mslm)
Altezza Neve (cm)	063	000	1770
	003	000	1350

VALANGHE OSSERVATE: Nessuna valanga.

PREVISIONI 17/02/2026

GRADO DI PERICOLO: MODERATO 2

SITUAZIONE TIPO: neve a debole coesione e vento.



SITUAZIONE TIPO: situazione primaverile.

MANTO NEVOSO: La stabilità del manto nevoso è scarsa su alcuni punti (aree) per tutte le esposizioni al di sopra di 1800 mslm, possibili valanghe di dimensioni piccole.
La stabilità del manto nevoso è scarsa su alcuni punti (aree) per tutte le esposizioni al di sotto di 1800 mslm, possibili valanghe di dimensioni piccole.

AVVERTENZE

Viste le condizioni del manto nevoso, le attività al di fuori delle piste battute e segnalate richiedono ottime capacità di valutazione del pericolo locale.

SCALA EUROPEA DEL GRADO DI PERICOLO VALANGHE

LEGENDA PROBLEMA

Bollettino realizzato su scala sinottica-regionale (standard EAWS). La sua valutazione non può escludere in alcun modo la necessità di una seria e capace valutazione locale del pericolo (singolo pendio) che può essere anche sensibilmente diverso. Le previsioni meteorologiche sono relative all'orario UTC (per l'Italia +1 in inverno e +2 in estate).

MINISTERO DELLA DIFESA

meteomont
Servizio Nazionale di previsione neve e valanghe

EAWS EUROPEAN AVALANCHE WARNING SERVICES

CARABINIERI

TERMINILLO MONTI REATINI E LAGA OVEST

PREVISIONE METEO

Quota		17/02/2026 h6:00	17/02/2026 h12:00	17/02/2026 h18:00
1000	Venti	*08 Nodi da Nord*	*05 nodi da N-Ovest*	*04 nodi da N-Ovest*
	Temperature	*-04 °C*	*+00 °C*	*-01 °C*
	Temp.percepita	*-9 °C*	*-3 °C*	*-4 °C*
2000	Venti	*21 Nodi da Nord*	*15 Nodi da Nord*	*11 nodi da N-Ovest*
	Temperature	*-07 °C*	*-04 °C*	*-04 °C*
	Temp.percepita	*-17 °C*	*-11 °C*	*-10 °C*
3000	Venti	*28 Nodi da Nord*	*16 nodi da N-Ovest*	*16 nodi da N-Ovest*
	Temperature	*-12 °C*	*-12 °C*	*-11 °C*
	Temp.percepita	*-25 °C*	*-22 °C*	*-21 °C*
Zero termico		*0800-1000 m.*	*1300-1500 m.*	*1200-1400 m.*
Fenomeno		—	—	—
Stato del cielo				

LEGENDA FENOMENI

Assenza Fenomeni — *Nebbia* — *Foschia* — *Pioggia debole* — *Pioggia moderata* — *Pioggia forte* — *Temporali*

Nevicata debole — *Nevicata moderata* — *Nevicata forte*

STATO DEL CIELO

Sereno — *Poco nuvoloso* — *Nuvoloso* — *Molto nuvoloso* — *Coperto*

Parametri meteonivometrici registrati presso i campi di rilevamento il 16/02/2026.

Località	*Comune*	*Quota (m.s.l.m.)*	*Altezza neve (cm)*	*Neve caduta nelle 24 ore (cm)*	*Temp. Min (°C)*	*Temp. Max (°C)*	*Condizioni del tempo*
PESCHIERE	Amatrice (RI)	1270	0	0	-1	+8	Assenza di precipitazioni
M. CAIDURO	Cittareale (RI)	1300	0	0	-2	+7	Assenza di precipitazioni
VALLONINA	Leonessa (RI)	1350	3	0	-2	+6	Assenza di precipitazioni
GIRO DELL'ANELLO - VILLA CHIGI *	Rieti (RI)	1770	63	0	-2	-1	Assenza di precipitazioni

(*) Rilievi fuori campo

L'INFORMAZIONE E' PREVENZIONE - LEGGI L'ATTUALE GRADO DI PERICOLO VALANGHE!

IL CAPO DEL CENTRO NAZIONALE METEOMONT
(Ten. Col. RFI Emanuela Gini)
FIRMA AUTOGRAFA OMESSA AI SENSI
DELL'ART.3 DEL D.LGS N.39/1993

Bollettino realizzato su scala sinottica-regionale (standard EAWS). La sua valutazione non può escludere in alcun modo la necessità di una seria e capace valutazione locale del pericolo (singolo pendio) che può essere anche sensibilmente diverso. Le previsioni meteorologiche sono relative all'orario UTC (per l'Italia +1 in inverno e +2 in estate).