Bulletin d'estimation du risque d'avalanche

(valable en dehors des pistes balisées et ouvertes)

MASSIF : Aure Louron

Rédigé le lundi 16 février 2026 à 16h

Estimation des risques pour le : MARDI 17 FÉVRIER

COUCHES FRAGILES TEMPORAIRES

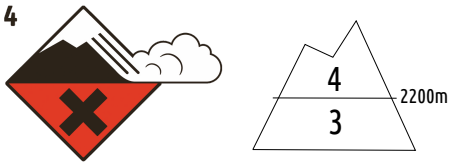

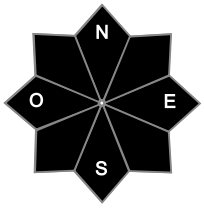

Au-dessus de 2200m indice de risque fort, plus bas indice marqué.

Départs spontanés : Avalanches de fond de neige humide sous 2200 m, plaques fragiles au-dessus.

Déclenchements provoqués : Nombreuses plaques instables au-dessus de 2200 m.

Indices de risque : 5 très fort - 4 fort - 3 marqué - 2 limité - 1 faible -- En noir : les pentes les plus dangereuses

Stabilité du manteau neigeux

Situation avalancheuse typique : neige fraîche neige ventée

Départs spontanés : le redoux et les pluies **jusque vers 2100 à 2200 m** ont humidifié le manteau neigeux en place. Des **avalanches de neige humide et de fond** sont possibles en **toutes orientations** ce lundi, parfois la nuit et demain avec la douceur des nuées en journée mardi. Ces avalanches seront fréquemment de taille 2 voire de taille 3 et, **rarement de taille 4 ,** en partant des secteurs déventés en large Sud-Ouest /Sud à Est, où les accumulations de neige sont les plus importantes. Ces avalanches sont susceptibles d'atteindre quelques routes ou infrastructures.
Au-dessus de 2200 m nombreuses plaques en large sud-ouest à sud et Est, pouvant se déclencher par effet du vent et transport, avalanches de taille 2 à 3 généralement, rares cassures de taille 4 en large Sud-Ouest à Sud et Est (secteurs d'accumulation).

Déclenchements provoqués : Au-dessus de 2200 m de **nombreuses plaques** en large sud-ouest à Sud et Est, peuvent se déclencher facilement par un simple skieur, initiant des avalanches de taille 2 à **3 généralement, rares cassures de taille 4** (> 1 m d'épaisseur) en large Sud-Ouest à Sud et Est ((pentes d'accumulation sur tous les massifs). Quelques plaques formées en pentes Est et Sud, lundi soir et la nuit sous 2200 m avec les chutes neigeuses en refroidissement et par vent assez fort de Nord-Ouest, cassures de 10 à 20 cm.

Autres : Corniches épaisses, secteurs en glace au vent en altitude.

Qualité de la neige

Enneigement : **Cumuls importants en haute montagne,** avec toujours crêtes, cols et sommets en expositions ouest à Nord-Ouest souvent assez pelés, ou en glace. Manteau neigeux débutant vers 1300 m, épais à partir de 1500 m en en zones déventées, mais dernières chutes en moyenne montagne s'humidifiant et se tassant rapidement.

Limites skiables : à partir de 1300 à 1400m lundi matin, mais remontant nettement en journée sous le temps doux et pluvieux.

État de la neige : Sur un manteau humidifié sous 2300/2200 m, présence de quelques centimètres de fraîche mardi matin puis, neige devenant humide sous 2200 m, sous-couche très dense sous 2000 m. Au-dessus de 2200 m neige alourdie en surface en Sud en journée à la faveur de quelques éclaircies, sèche à l'ombre sous la petite humidité de surface.

Aperçu météo pour le mardi 17 février

nuit	matin	après-midi	soir

Qiuelques chutes de neige cette nuit et faiblement mardi matin en ciel bouché, nuages et éclaircies en après-midi, ciel voilé la nuit vers mercredi.

Pluie-Neige	1 300 m	1 800 m	2 000 m	
Iso 0 °C	1 600 m	2 100 m	2 300 m	2 400 m
Vent 1500 m	↓ 65 km/h	↓ 60 km/h	↘ 60 km/h	→ 60 km/h
Vent 3000 m	↘ 90 km/h	↓ 80 km/h	↘ 80 km/h	↘ 85 km/h

Épaisseur de neige hors-piste

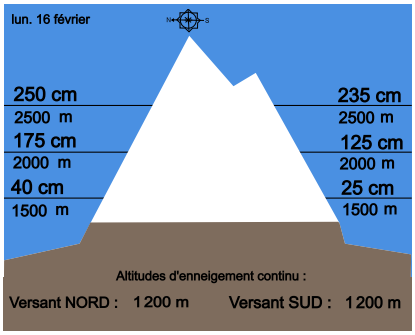

Précipitations à 1800 m

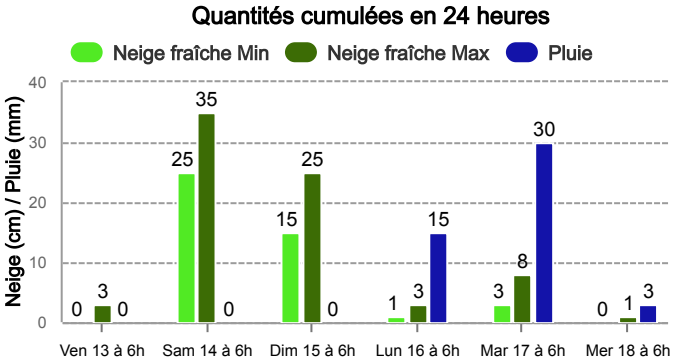

Tendance du mercredi 18 février

Indice de risque marqué

Avalanches de fond ou neige humide par redoux et ensoleillement en Sud.
Nombreuses plaques encore en place.

Pour consulter la vigilance en cours, veuillez vous rendre sur le site https://vigilance.meteofrance.fr/fr

Météo-France - 73 avenue de Paris, 94165 Saint-Mandé cedex - Contact : contact@meteo.fr

Rédigé par Météo-France avec la contribution des observateurs du réseau nivo-météorologiques. Partenariat : ANMSM (Maires de Stations de Montagne), DSF (Domaines Skiables de France), ADSP (Directeurs de Pistes et de la Sécurité des Stations de Sports d'Hiver) et autres acteurs de la montagne.

Bulletin neige & avalanches par téléphone au
0 892 68 10 20 Service 0,35 € / min + prix appel

Bulletin d'estimation du risque d'avalanche

(valable en dehors des pistes balisées et ouvertes)

MASSIF : Aure Louron

Rédigé le lundi 16 février 2026 à 16h

Conditions nivo-météo des 7 derniers jours

	mar. 10/02				mer. 11/02				jeu. 12/02				ven. 13/02				sam. 14/02				dim. 15/02				lun. 16/02			
	03h	09h	15h	21h	03h	09h	15h	21h	03h	09h	15h	21h	03h	09h	15h	21h	03h	09h	15h	21h	03h	09h	15h	21h	03h	09h	15h	21h
Météo																												
Vent (km/h)	75	90	100	100	90	110	110	120	120	120	100	55	100	65	100	115	85	60	65	40	35	40	80	90	90	85	95	100
à 3000m																												
Vent (km/h)	40	50	50	40	30	40	60	90	90	80	60	25	55	35	35	65	55	35	55	15	20	15	25	30	35	40	50	60
à 1500m																												

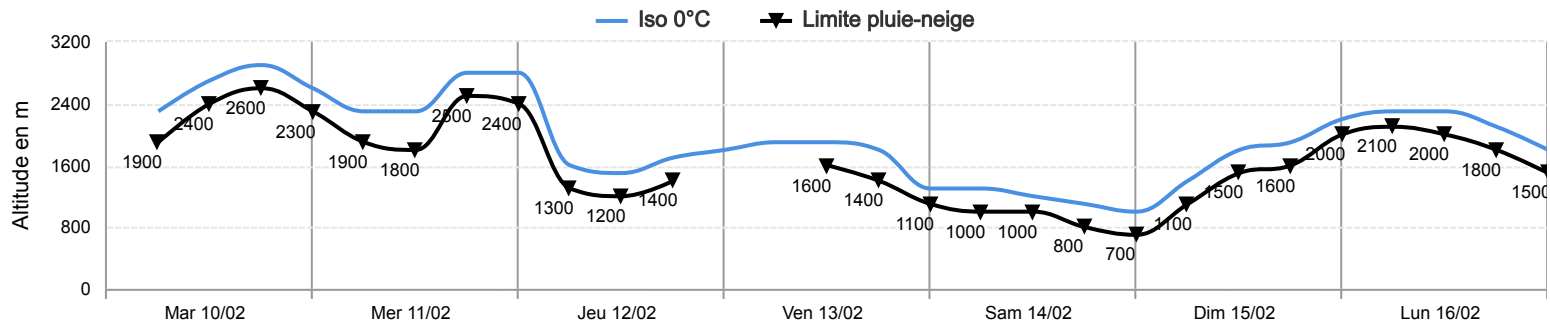

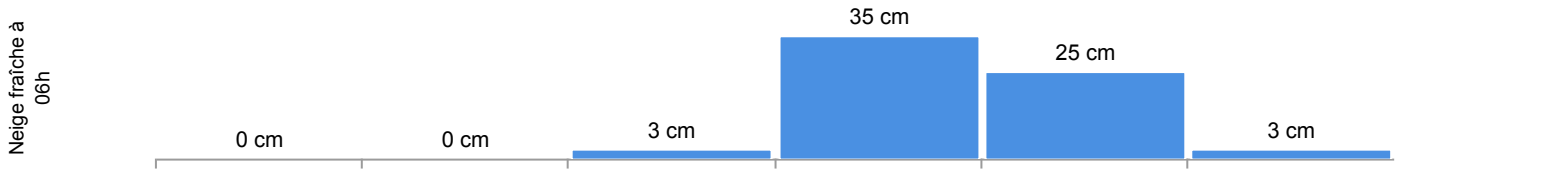

Risque d'avalanche	mar. 10/02	mer. 11/02	jeu. 12/02	ven. 13/02	sam. 14/02	dim. 15/02	lun. 16/02
	3	3	3	2	3	4	4

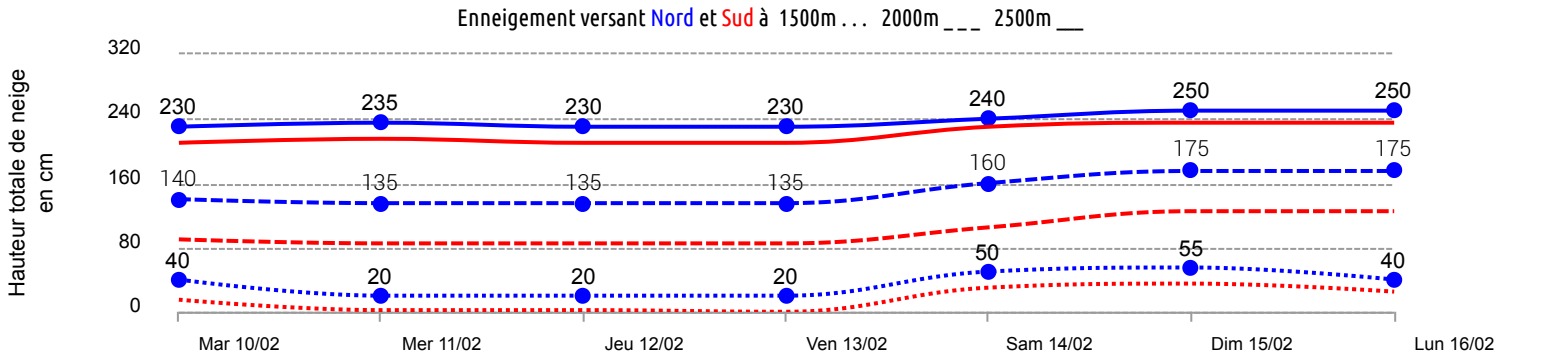

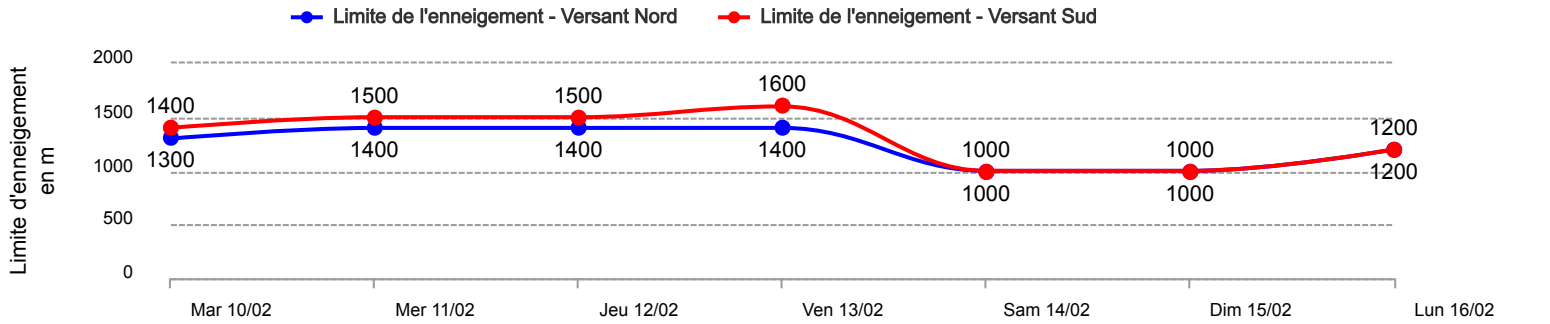

Pour consulter la vigilance en cours, veuillez vous rendre sur le site https://vigilance.meteofrance.fr/fr

Météo-France - 73 avenue de Paris, 94165 Saint-Mandé cedex - Contact : contact@meteo.fr

Bulletin neige & avalanches par téléphone au

0 892 68 10 20 Service 0,35 € / min + prix appel

Rédigé par Météo-France avec la contribution des observateurs du réseau nivo-météorologiques. Partenariat : ANMSM (Maires de Stations de Montagne), DSF (Domaines Skiables de France), ADSP (Directeurs de Pistes et de la Sécurité des Stations de Sports d'Hiver) et autres acteurs de la montagne.