Bulletin d'estimation du risque d'avalanche
(valable en dehors des pistes balisées et ouvertes)
MASSIF : Belledonne

Rédigé le lundi 16 février 2026 à 16h

Estimation des risques pour le : MARDI 17 FÉVRIER

NOUVELLES CHUTES DE NEIGE, ET EN ALTITUDE VENT FORT DE NORD-OUEST

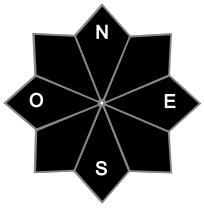

en altitude surtout

Indices de risque : 5 très fort - 4 fort - 3 marqué - 2 limité - 1 faible -- En noir : les pentes les plus dangereuses

Indice de risque fort.

Départs spontanés : avalanches de grande taille, parfois de rares très grandes avalanches (taille 4) sous les chutes de neige et le vent. Ruptures de corniches et plaques sous le vent de NO.

Déclenchements provoqués : risque fort en altitude avec de nombreuses plaques facilement déclenchables.

Vigilance orange avalanches en cours ou prévue sur le massif

Stabilité du manteau neigeux

Situation avalancheuse typique : neige fraîche neige ventée

Départs spontanés :
Entre ce lundi soir et mardi soir, on attend encore 30 cm supplémentaires au-dessus de 1800 m voire 50 cm par endroits plus haut en altitude, et avec le vent fort ce cumul sera comme lundi, très inégal selon les secteurs.Fréquentes avalanches partant naturellement à envisager d'ici mardi soir, sous les chutes de neige, pouvant être de grande taille (taille 3) en divers versants et surtout plus haut que 2000 m où les quantités sont plus significatives. Nombreuses ruptures de corniches et d'accumulations en plaques sous le vent à prévoir, le vent devrait toutefois faiblir surtout vers la mi-journée ce mardi.Enfin il est possible que des très grandes avalanches (taille 4) se déclenchent en présence de sous couches fragiles persistantes assez enfouies dans le manteau neigeux, au-dessus de 2200 m environ, dans un large secteur nord. Certaines de ces avalanches pourraient atteindre routes et infrastructures de montagne, jusqu'en moyenne montagne... méfiance.

Déclenchements provoqués :
Manteau neigeux restant très instable en montagne et les conditions météo prévues n'arrangent pas les choses... Un skieur peut très facilement rompre des plaques dures y compris loin des crêtes, déclenchement en pied de talus aussi. Déclenchement par endroits de plaques friables à l'abri du vent au moindre passage d'un skieur.Dans un large secteur Nord, des sous couches fragiles sont encore enfouies et une première rupture de plaque pourrait entrainer une épaisse et large cassure en contrebas, entrainant un volume de neige conséquent. Plus bas que 1800 m environ, les sous couches sont "un peu mieux stabilisées" si on peut dire, et le risque de présence de plaques se retrouve plutôt à proximité des crêtes.

Qualité de la neige

Qualification de l'enneigement : l'enneigement s'est encore amélioré en altitude, dans les combes, où il devient excellent pour la saison sur l'ensemble du massif. Seules les zones de crêtes et cols soufflés sont moins enneigés.

Limites skiables : vers 1100/1300 m.

Qualité de la neige mardi :
Neige fraîche poudreuse parfois très épaisse et souvent soufflée/chahutée par le vent fort en altitude. Cette poudreuse est présente dès 1500/1600m mais très rapidement travaillée par le vent. Fortes épaisseurs au dessus de 2000 m environ avec plus d'1m50 de neige récente vers 2500 m, de très grosses congères/corniches et des secteurs plus dégarnis/ englacés...

Aperçu météo pour le mardi 17 février

	nuit	matin	après-midi	soir

Chutes de neige avec quelques accalmies jusqu'à mardi fin de journée. Vent de NO fort en altitude jusque mardi midi environ.

Pluie-Neige	800 m	800 m	900 m	
Iso 0 °C	1 200 m	1 200 m	1 400 m	1 400 m
Vent 2000 m	↘ 80 km/h	↘ 60 km/h	↘ 40 km/h	↓ 25 km/h
Vent 3000 m	↘ 95 km/h	↘ 75 km/h	↘ 55 km/h	↘ 40 km/h

Épaisseur de neige hors-piste

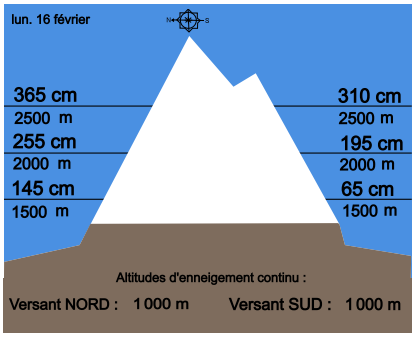

Précipitations à 1800 m

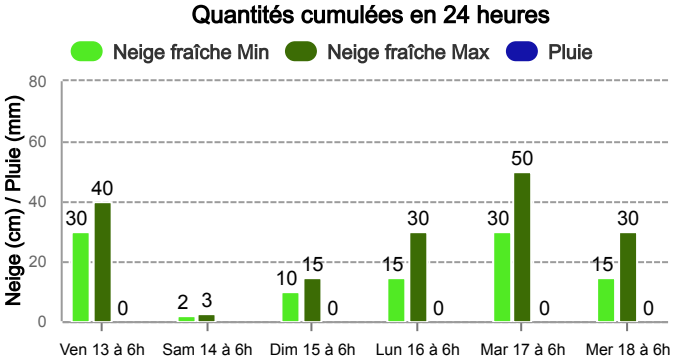

Tendance du mercredi 18 février

Indice de risque marqué

Accalmie ce mercredi avant nouvelle dégradation la nuit suivante. Peut-être un risque en lente diminution, à confirmer.

Pour consulter la vigilance en cours, veuillez vous rendre sur le site https://vigilance.meteofrance.fr/fr

Météo-France - 73 avenue de Paris, 94165 Saint-Mandé cedex - Contact : contact@meteo.fr

Rédigé par Météo-France avec la contribution des observateurs du réseau nivo-météorologiques. Partenariat : ANMSM (Maires de Stations de Montagne), DSF (Domaines Skiables de France), ADSP (Directeurs de Pistes et de la Sécurité des Stations de Sports d'Hiver) et autres acteurs de la montagne.

Bulletin neige & avalanches par téléphone au **0 892 68 10 20** Service 0,35 € / min + prix appel

RÉPUBLIQUE FRANÇAISE
Liberté Égalité Fraternité

METEO FRANCE
À VOS CÔTÉS, DANS UN CLIMAT QUI CHANGE

Bulletin d'estimation du risque d'avalanche

(valable en dehors des pistes balisées et ouvertes)

MASSIF : Belledonne

Rédigé le lundi 16 février 2026 à 16h

Conditions nivo-météo des 7 derniers jours

	mar. 10/02				mer. 11/02				jeu. 12/02				ven. 13/02				sam. 14/02				dim. 15/02				lun. 16/02			
	03h	09h	15h	21h	03h	09h	15h	21h	03h	09h	15h	21h	03h	09h	15h	21h	03h	09h	15h	21h	03h	09h	15h	21h	03h	09h	15h	21h
Météo																												
Vent (km/h)	50	40	50	70	100	85	85	100	100	100	90	50	40	30	35	15	30	15	40	40	50	40	45	65	75	100	110	115
à 3000m																												
Vent (km/h)	35	25	40	50	80	55	55	90	80	85	75	30	25	10	10	15	20	15	25	30	30	20	15	35	50	70	80	85
à 2000m																												

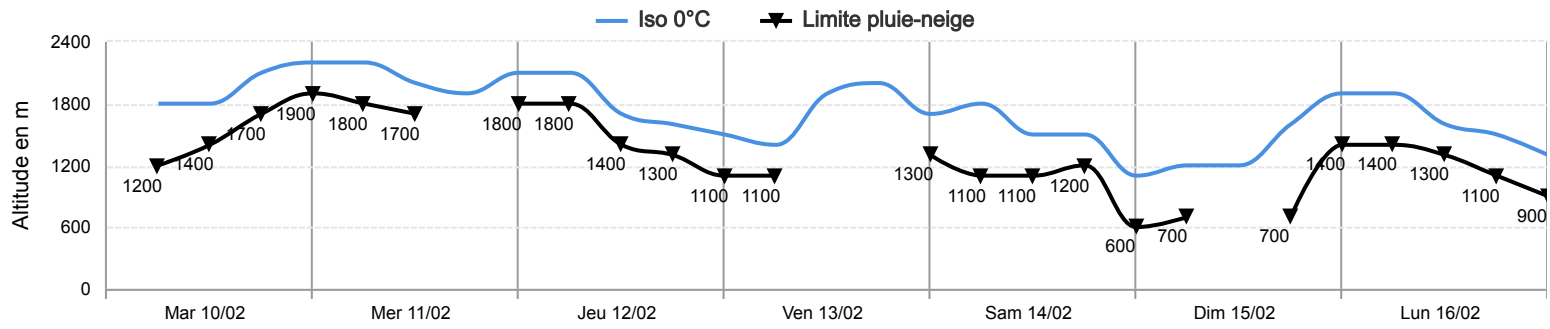

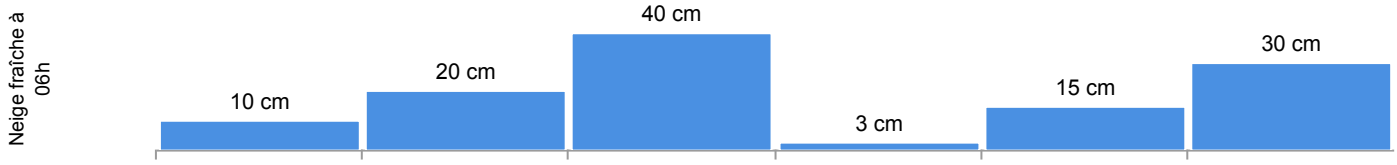

Risque d'avalanche							
	3	4	4	4	3	3	4
	mar. 10/02	mer. 11/02	jeu. 12/02	ven. 13/02	sam. 14/02	dim. 15/02	lun. 16/02

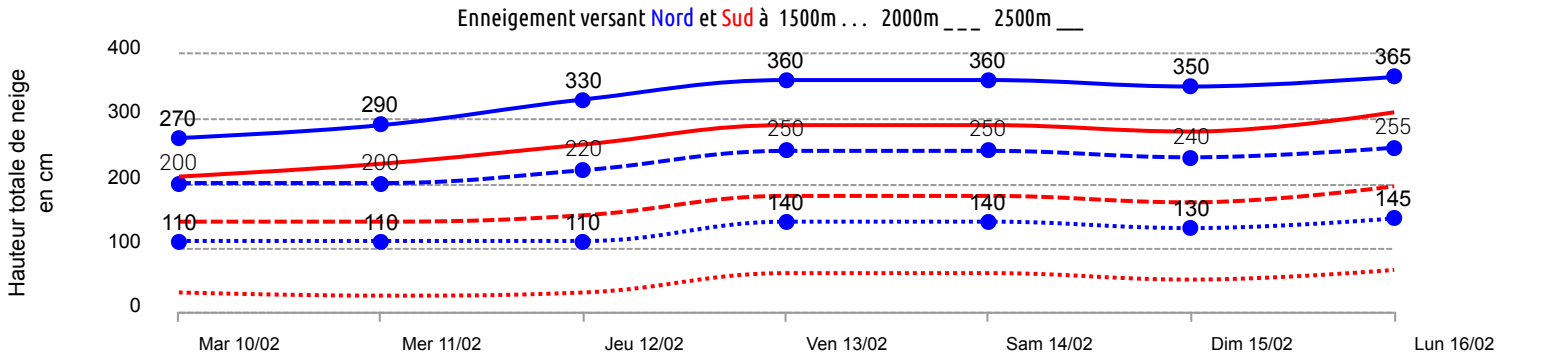

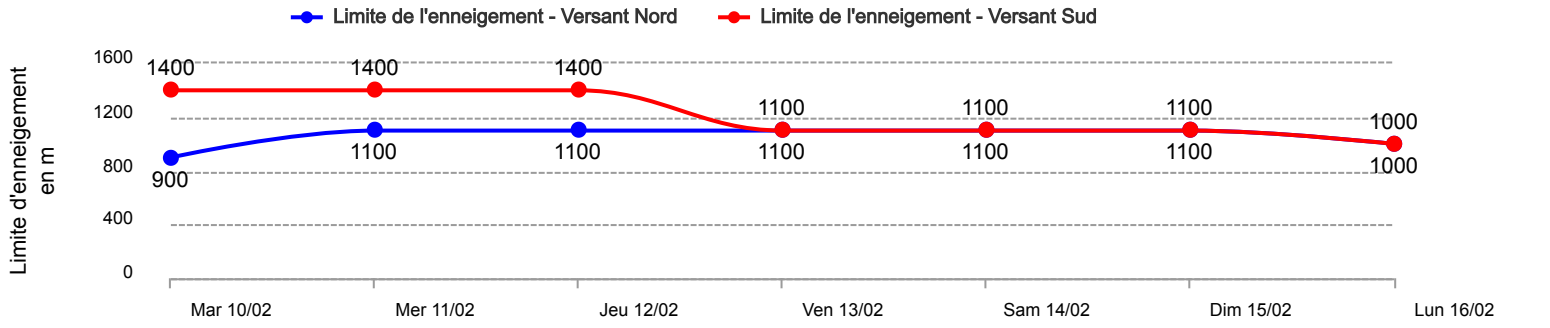

Pour consulter la vigilance en cours, veuillez vous rendre sur le site https://vigilance.meteofrance.fr/fr

Météo-France - 73 avenue de Paris, 94165 Saint-Mandé cedex - Contact : contact@meteo.fr

Rédigé par Météo-France avec la contribution des observateurs du réseau nivo-météorologiques. Partenariat : ANMSM (Maires de Stations de Montagne), DSF (Domaines Skiables de France), ADSP (Directeurs de Pistes et de la Sécurité des Stations de Sports d'Hiver) et autres acteurs de la montagne.

Bulletin neige & avalanches par téléphone au

0 892 68 10 20 Service 0,35 € / min + prix appel