Bulletin d'estimation du risque d'avalanche
(valable en dehors des pistes balisées et ouvertes)

MASSIF : Chartreuse

Rédigé le lundi 16 février 2026 à 16h

Estimation des risques pour le : MARDI 17 FÉVRIER

NOUVELLES CHUTES DE NEIGE, VENTÉES EN ALTITUDE.

3

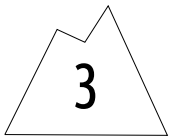

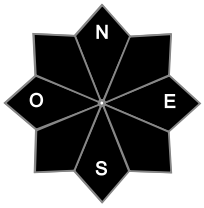

Indice de risque marqué.

Départs spontanés : avalanches naturelles sous les chutes de neige. Rupture de corniches et de plaques sous l'action du vent vers les sommets.

Déclenchements provoqués : nombreuses plaques présentes, et nouvelles en formation vers les sommets du massif.

Indices de risque : 5 très fort - 4 fort - 3 marqué - 2 limité - 1 faible -- En noir : les pentes les plus dangereuses

Stabilité du manteau neigeux

Situation avalancheuse typique : neige fraîche neige ventée

Départs spontanés : des chutes de neige sont encore attendues sur le massif avec environ 15 à 30 cm entre lundi soir et mardi soir plus haut que 1600 m environ, un peu moins plus bas. Ces chutes de neige sont accompagnées d'un vent de nord-ouest soutenu sur les hautes crêtes jusque mardi midi environ.
- Des avalanches naturelles peuvent partir sous les chutes de neige, de taille moyenne à grande (2 à 3), surtout vers les hauts sommets du massif.
- Corniches ou accumulations peuvent céder sous l'effet du vent vers les crêtes, pouvant occasionner des départs assez significatifs.

Déclenchements provoqués : manteau neigeux instable, surtout dans la neige récente et en altitude, vers les hautes crêtes et sommets du massif.
- Déclenchement facile au passage d'un skieur dans divers versants, sous forme de plaque dure pouvant être épaisse et assez large, et parfois en plaque friable en secteurs à l'abri du vent.

Les chutes de neige annoncées sont accompagnées d'un vent de nord-ouest fort favorisant la formation de nouvelles plaques.
Le risque est moins marqué sous 1500 m environ.

Qualité de la neige

Qualification de l'enneigement : l'enneigement s'est récemment dégradé aux basses altitudes, sous les sapins mais il est bon pour la saison dès la moyenne altitude et dans les combes sommitales... Crêtes parfois dégarnies/ congères et corniches...

Limites skiables : vers 1100/1300 m, sur les pistes forestières/clairières...

Qualité de la neige mardi : neige fraîche poudreuse parfois très épaisse en altitude mais souvent soufflée/chahutée vers les hautes crêtes et sommets/ durcie, sculptée parfois. Neige fraîche assez lourde/humide sous 1200/1300 m environ, plus légère au-dessus à l'abri du vent.

Aperçu météo pour le mardi 17 février

	nuit	matin	après-midi	soir

Chutes de neige avec quelques accalmies jusqu'à mardi fin de journée. Vent de NO soutenu vers les sommets jusque mardi midi environ.

Pluie-Neige	800 m	800 m	900 m	
Iso 0 °C	1 100 m	1 100 m	1 300 m	1 400 m
Vent 1500 m	→ 50 km/h	↘ 40 km/h	↘ 30 km/h	↓ 20 km/h
Vent 2000 m	↘ 75 km/h	↘ 60 km/h	↘ 45 km/h	↘ 30 km/h

Épaisseur de neige hors-piste

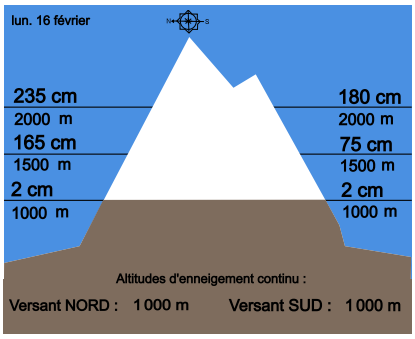

Précipitations à 1800 m

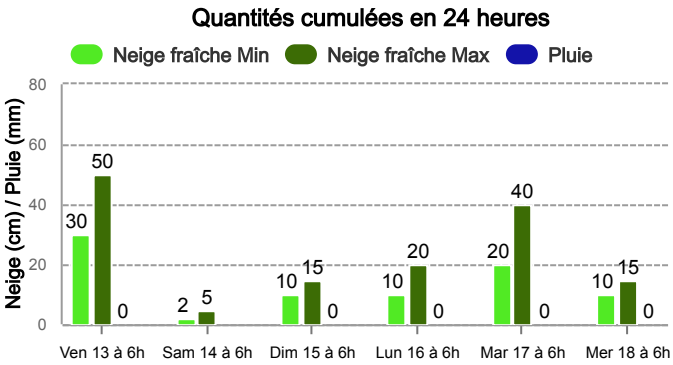

Tendance du mercredi 18 février

3

Indice de risque marqué

Accalmie ce mercredi avant nouvelle dégradation la nuit suivante. Peut-être un risque en lente diminution, mais vers les sommets du massif il semblerait qu'un risque marqué soit toujours d'actualité.

Pour consulter la vigilance en cours, veuillez vous rendre sur le site https://vigilance.meteofrance.fr/fr

Météo-France - 73 avenue de Paris, 94165 Saint-Mandé cedex - Contact : contact@meteo.fr

Rédigé par Météo-France avec la contribution des observateurs du réseau nivo-météorologiques. Partenariat : ANMSM (Maires de Stations de Montagne), DSF (Domaines Skiables de France), ADSP (Directeurs de Pistes et de la Sécurité des Stations de Sports d'Hiver) et autres acteurs de la montagne.

Bulletin neige & avalanches par téléphone au **0 892 68 10 20** Service 0,35 € / min + prix appel

Bulletin d'estimation du risque d'avalanche

(valable en dehors des pistes balisées et ouvertes)

MASSIF : Chartreuse

Rédigé le lundi 16 février 2026 à 16h

Conditions nivo-météo des 7 derniers jours

	mar. 10/02				mer. 11/02				jeu. 12/02				ven. 13/02				sam. 14/02				dim. 15/02				lun. 16/02			
	03h	09h	15h	21h	03h	09h	15h	21h	03h	09h	15h	21h	03h	09h	15h	21h	03h	09h	15h	21h	03h	09h	15h	21h	03h	09h	15h	21h
Météo																												
Vent (km/h)	50	40	50	70	65	65	65	100	85	70	70	35	35	20	15	15	15	25	40	35	45	25	30	55	65	75	80	80
à 2000m																												
Vent (km/h)	40	30	35	50	40	30	35	85	70	50	45	15	15	20	25	10	10	20	30	35	35	10	10	25	35	45	60	60
à 1500m																												

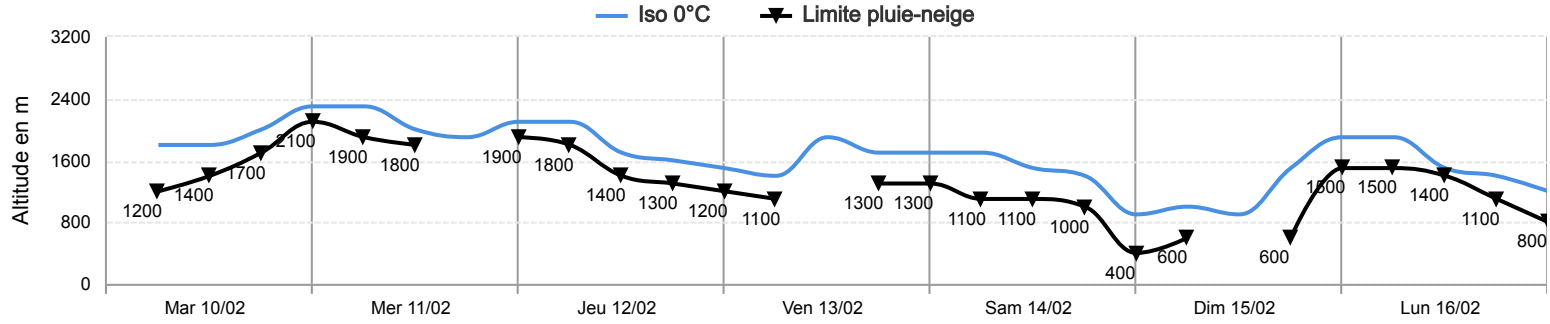

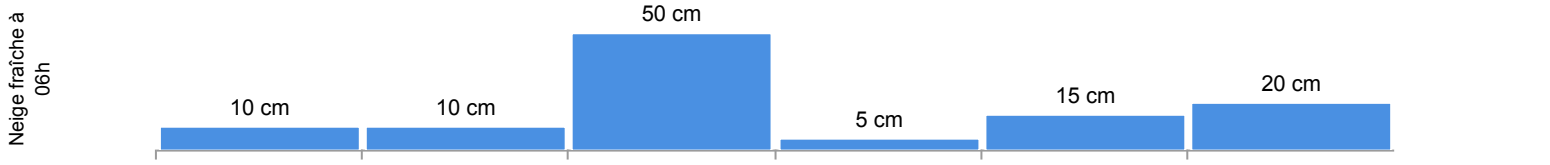

Risque d'avalanche	mar. 10/02	mer. 11/02	jeu. 12/02	ven. 13/02	sam. 14/02	dim. 15/02	lun. 16/02
	3	3	3	3	3	3	3

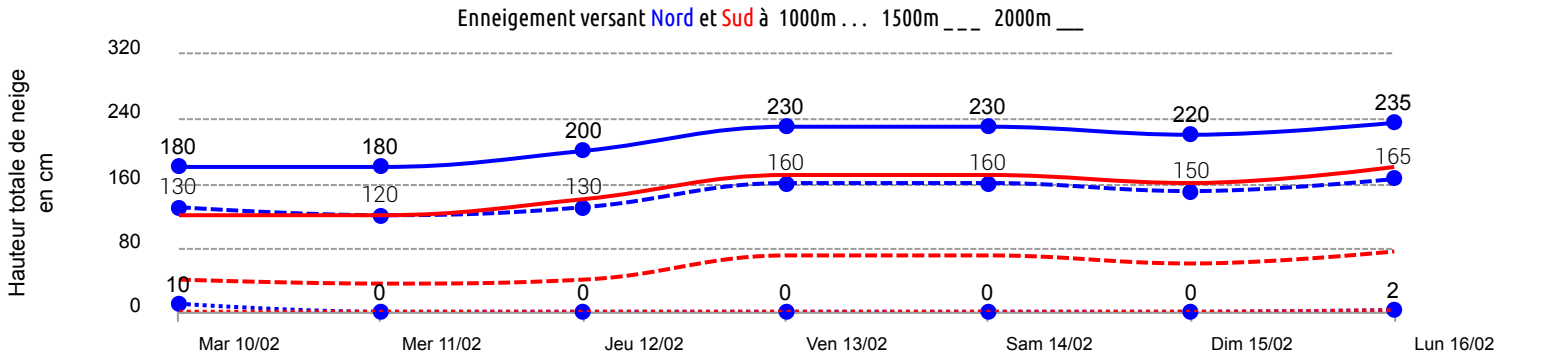

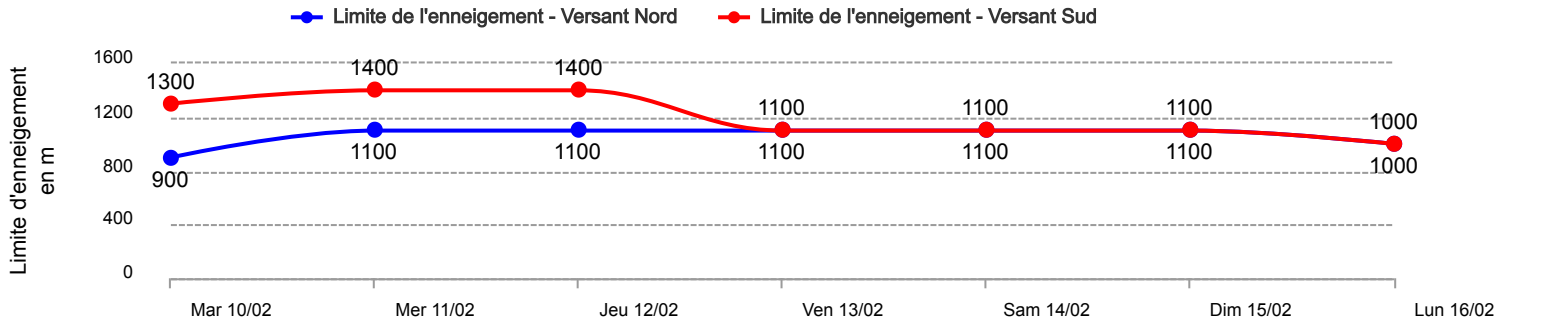

Pour consulter la vigilance en cours, veuillez vous rendre sur le site https://vigilance.meteofrance.fr/fr

Météo-France - 73 avenue de Paris, 94165 Saint-Mandé cedex - Contact : contact@meteo.fr

Bulletin neige & avalanches par téléphone au

0 892 68 10 20 Service 0,35 € / min + prix appel

Rédigé par Météo-France avec la contribution des observateurs du réseau nivo-météorologiques. Partenariat : ANMSM (Maires de Stations de Montagne), DSF (Domaines Skiables de France), ADSP (Directeurs de Pistes et de la Sécurité des Stations de Sports d'Hiver) et autres acteurs de la montagne.