Bulletin d'estimation du risque d'avalanche

(valable en dehors des pistes balisées et ouvertes)

MASSIF : Cinto Rotondo

Rédigé le lundi 16 février 2026 à 16h

Estimation des risques pour le : MARDI 17 FÉVRIER

CHUTES DE NEIGE ET VENT FORT GÉNÈRENT DE NOUVELLES STRUCTURES DE PLAQUES DANS LA NEIGE RÉCENTE.

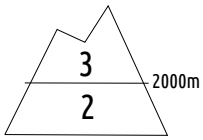

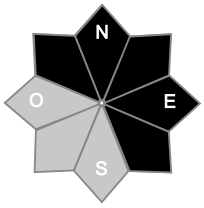

Au-dessus de 2000m indice de risque marqué, plus bas indice limité.

Départs spontanés : Coulées et avalanches en neige fraîche sous les chutes de neige et par surcharge due au transport par le vent

Déclenchements provoqués : Nombreuses instabilités dans la neige récente, présentes en toutes orientations

Indices de risque : 5 très fort - 4 fort - 3 marqué - 2 limité - 1 faible -- En noir : les pentes les plus dangereuses

Stabilité du manteau neigeux

Situation avalancheuse typique : neige ventée

Déclenchements provoqués : Au-dessus de 1800 à 2000m, manteau neigeux instable formé d'**empilement de plaques à vent en tous versants** suivant les vents irréguliers et même tourbillonnants des derniers jours. Vent d'Ouest accompagnant les nouvelles chutes de neige, formant de nombreuses structures de plaques dans la neige récente, au fil des chutes et même après, avec le fort transport de neige par le vent, qui la dépose parfois loin des crêtes. Ces plaques sont fréquentes dans les secteurs orientés à l'Est mais elles peuvent exister en tous versants ; elles sont par endroits dures à cause du vent fort, par endroits friables plus à l'abri du vent. Elles sont parfois difficilement identifiables en gardant un aspect poudreux ou en étant recouvertes d'une couche de neige fraîche. Reposant sur une couche de neige récente plus légère faisant office de sous-couche fragile, ces plaques sont **faciles à déclencher à l'abri des vents** d'Ouest à Nord-Ouest, plus difficilement déclenchables dans les secteurs exposés au vent. Elles engendrent des avalanches de taille petite à moyenne (taille 1 à 2). Une grande avalanche (taille 3) n'est pas exclue dans une zone de forte accumulation par le vent ou en cas de déstabilisation de "vieilles" plaques plus épaisses, présentes en orientations Nord et Est, au-dessus de 2000 m environ.

Départs spontanés : Des départs ponctuels en neige fraîche se produisent dans les pentes raides au fil des chutes de neige, et **par surcharge due au transport par le vent**, déclenchant les plaques formées et en formation décrites ci-dessus. Au vu des volumes de neige récente mobilisable, on peut attendre de **grandes avalanches (taille 3) partant des accumulations** constituées à l'abri des vents d'Ouest à Nord, plutôt de taille 1 à 2 dans les autres secteurs.

Autres : Risque de glissade en neige dure ou glacée aux abords des crêtes et sommets balayés par les vents.

Qualité de la neige

Qualification de l'enneigement : L'enneigement est excellent pour la saison à toutes altitudes. On relève plus de 2 mètres dans les combes abritées. Il est encore tombé 20 à 30 cm de neige fraîche au-dessus de 1700 m dans la haute vallée d'Asco ces dernières 24 heures.

Limite d'enneigement skiable : 1300 à 1500 m suivant le versant.

État de la neige : On trouve en surface une couche de neige fraîche de plus en plus significative en montant mais le vent d'Ouest à Nord-Ouest soutenu rend l'enneigement très hétérogène : les orientations Nord et Est sont souvent plus garnies que les pentes Ouest rapidement pelées ou verglacées dès que l'on se rapproche des crêtes et sommets. La neige est froide et poudreuse à l'abri du vent dès 1800 à 2000 m d'altitude, elle devient plus compacte, voire cartonnée dans les secteurs ventés. On trouve localement des accumulations de neige roulée. Corniches et accumulations parfois volumineuses sont en place.

Aperçu météo pour le mardi 17 février

	nuit	matin	après-midi	soir

Chutes de neige continues en soirée, transportées par le vent fort, faiblissant en deuxième partie de nuit avec abaissement de l'isotherme 0°C, puis devenant plus éparses en journée.

Pluie-Neige	1 000 m		1 000 m	
Iso 0 °C	1 400 m	1 300 m	1 400 m	1 500 m
Vent 1500 m	↘ 80 km/h	↘ 50 km/h	→ 50 km/h	→ 40 km/h
Vent 3000 m	↘ 100 km/h	↘ 80 km/h	↘ 70 km/h	↘ 60 km/h

Épaisseur de neige hors-piste

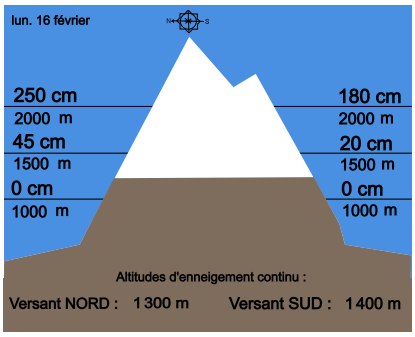

Précipitations à 1800 m

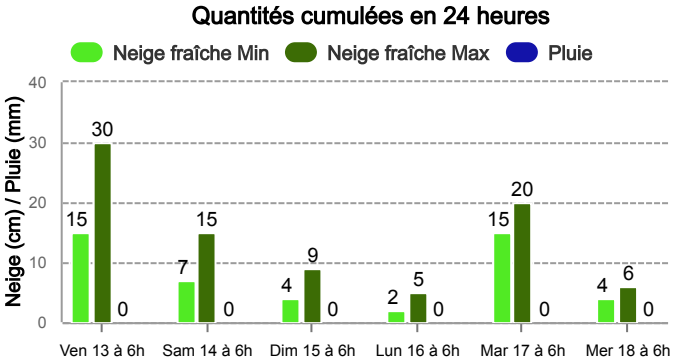

Tendance du mercredi 18 février

Indice de risque marqué

Peu ou pas de précipitations mais le vent d'Ouest à Nord-Ouest souffle encore assez fort, générant de nouvelles instabilités par transport de la neige récente légère. Maintien d'un risque marqué en altitude.

Pour consulter la vigilance en cours, veuillez vous rendre sur le site https://vigilance.meteofrance.fr/fr

Météo-France - 73 avenue de Paris, 94165 Saint-Mandé cedex - Contact : contact@meteo.fr

Rédigé par Météo-France avec la contribution des observateurs du réseau nivo-météorologiques. Partenariat : ANMSM (Maires de Stations de Montagne), DSF (Domaines Skiables de France), ADSP (Directeurs de Pistes et de la Sécurité des Stations de Sports d'Hiver) et autres acteurs de la montagne.

Bulletin neige & avalanches par téléphone au

0 892 68 10 20 Service 0,35 € / min + prix appel

RÉPUBLIQUE FRANÇAISE
Liberté Égalité Fraternité

METEO FRANCE
À VOS CÔTÉS, DANS UN CLIMAT QUI CHANGE

Bulletin d'estimation du risque d'avalanche
(valable en dehors des pistes balisées et ouvertes)

MASSIF : Cinto Rotondo

Rédigé le lundi 16 février 2026 à 16h

Conditions nivo-météo des 7 derniers jours

	mar. 10/02				mer. 11/02				jeu. 12/02				ven. 13/02				sam. 14/02				dim. 15/02				lun. 16/02			
	03h	09h	15h	21h	03h	09h	15h	21h	03h	09h	15h	21h	03h	09h	15h	21h	03h	09h	15h	21h	03h	09h	15h	21h	03h	09h	15h	21h
Météo																												
Vent (km/h)	30	25	40	60	80	100	100	90	80	120	100	100	60	55	35	70	50	20	50	50	40	70	50	50	80	90	120	130
à 3000m																												
Vent (km/h)	10	10	20	30	50	90	90	90	70	80	80	70	50	40	20	40	30	15	30	30	20	30	30	40	70	70	90	90
à 1500m																												

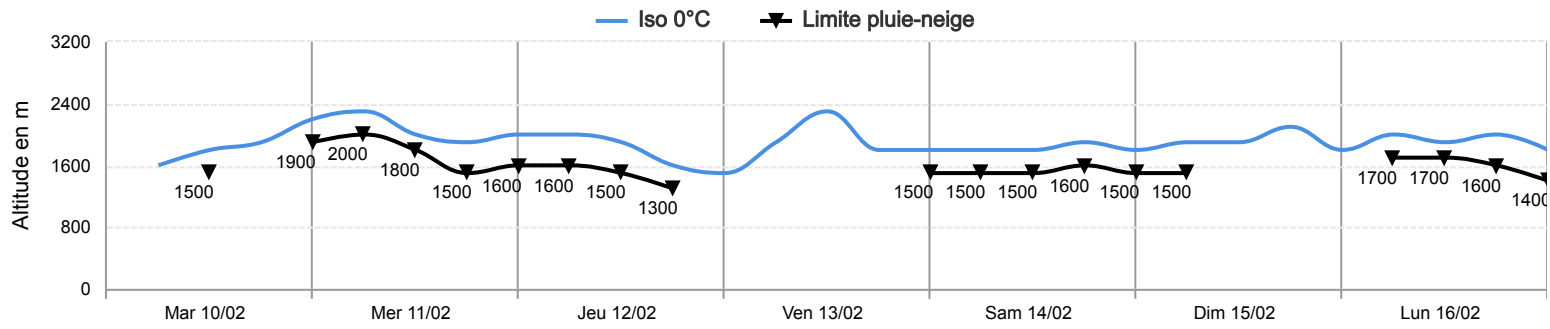

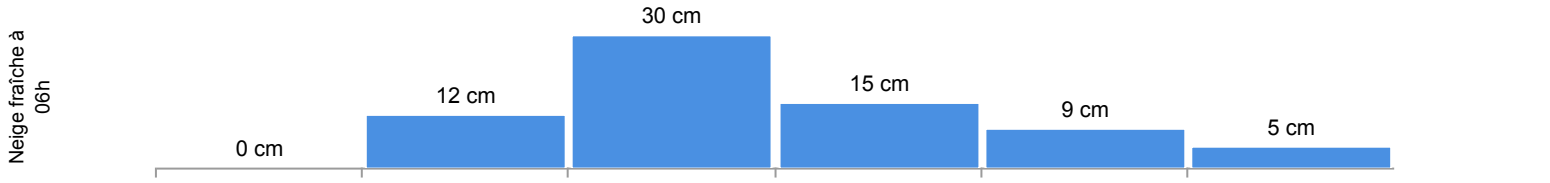

Risque d'avalanche	mar. 10/02	mer. 11/02	jeu. 12/02	ven. 13/02	sam. 14/02	dim. 15/02	lun. 16/02
	2	3	4	3	3	2	3

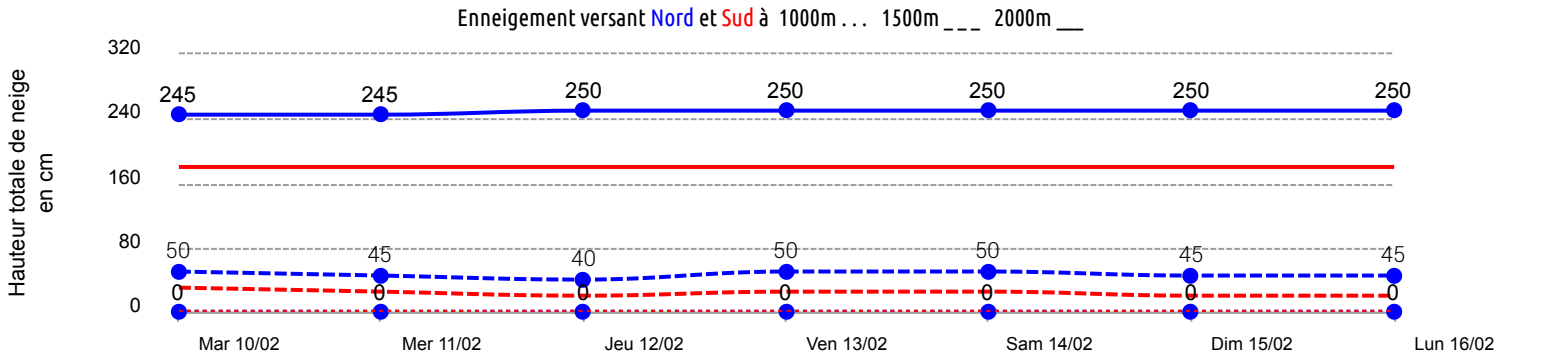

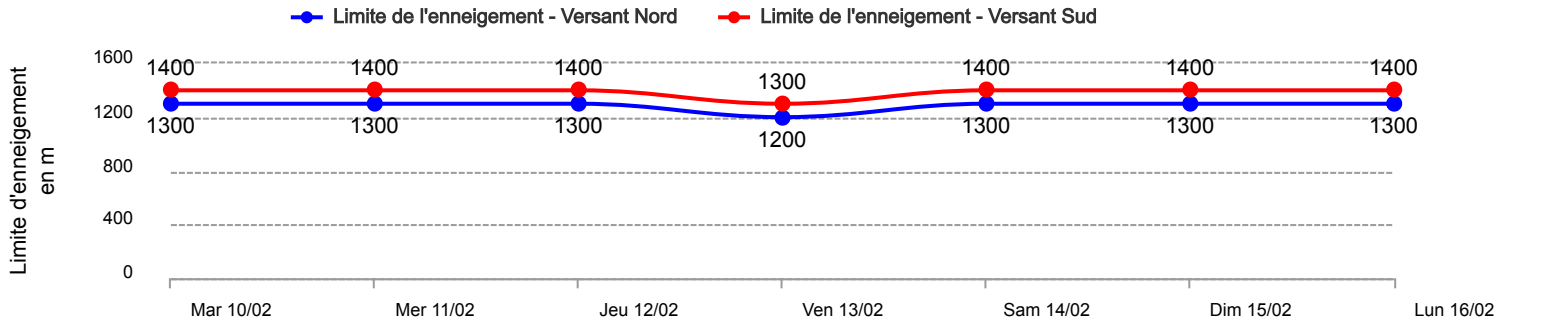

Pour consulter la vigilance en cours, veuillez vous rendre sur le site https://vigilance.meteofrance.fr/fr

Météo-France - 73 avenue de Paris, 94165 Saint-Mandé cedex - Contact : contact@meteo.fr

Rédigé par Météo-France avec la contribution des observateurs du réseau nivo-météorologiques. Partenariat : ANMSM (Maires de Stations de Montagne), DSF (Domaines Skiables de France), ADSP (Directeurs de Pistes et de la Sécurité des Stations de Sports d'Hiver) et autres acteurs de la montagne.

Bulletin neige & avalanches par téléphone au

0 892 68 10 20 Service 0,35 € / min + prix appel