Bulletin d'estimation du risque d'avalanche
(valable en dehors des pistes balisées et ouvertes)

MASSIF : Embrunais Parpaillon

Rédigé le lundi 16 février 2026 à 16h

Estimation des risques pour le : MARDI 17 FÉVRIER

FRÉQUENTES INSTABILITÉS DANS LA NEIGE FRAÎCHE FORTEMENT VENTÉE

3

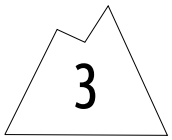

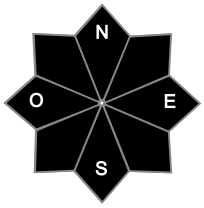

Indice de risque marqué.

Départs spontanés : avalanches de neige fraîche nombreuses en cours de nuit, souvent de grande taille, moins fréquentes en cours de journée mardi.

Déclenchements provoqués : plaques faciles à déclencher, même à moyenne altitude.

Indices de risque : 5 très fort - 4 fort - 3 marqué - 2 limité - 1 faible -- En noir : les pentes les plus dangereuses

Stabilité du manteau neigeux

Situation avalancheuse typique : neige ventée couche fragile persistante

Déclenchements provoqués : de nombreuses plaques sont en place et en formation dans la neige fraîche, fortement ventées jusqu'en basse montagne. Ces instabilités sont plus fréquentes à moyenne altitude, même dans des secteurs plutôt abrités des vents habituellement (forêts peu denses par exemple). Près des crêtes et sommets, ces plaques sont réparties de façon plus hétérogène. Elles sont situées dans des accumulations localement épaisses qui côtoient des secteurs décapés par le vent tempétueux. Avalanches de taille moyenne à grande (taille 2 à 3), une très grande avalanche (taille 4) non exclue, en cas sollicitation d'une couche fragile persistante enfouie en ubac, emportant une grande partie du manteau neigeux en place. Ce type de départ peut être initié par la surcharge liée au passage d'une première avalanche de surface.

Départs spontanés : quelques départs linéaires dans la neige fraîche ventée, générant des avalanches moyennes (taille 2), voire grandes (taille 3) dans les pentes les plus chargées par le vent. Une rare très grande avalanche possible (taille 4) en ubacs d'altitudes.

Qualité de la neige

L'enneigement est excédentaire pour un mois de février. Les chutes de neige se succèdent depuis le début du mois de janvier.
Hauteurs de neige observées : 94 cm à la Nivôse du Parpaillon à 2550 m, secteur soufflé par le vent.

Limite d'enneigement skiable : dès 1200/1400 m en ubacs sur la plupart des itinéraires, plutôt 1400/1500 m en adrets favorables.

État de la neige de surface : petite couche de neige fraiche en surface fortement travaillée par le vent dans la plupart des pentes au-dessus de 1800/2000. Crêtes décapées par le vent de nord-ouest, et grosses accumulations/corniches en formation. Neige restant localement plus légère et froide en toutes orientations dans les secteurs bien abrités du vent.

Aperçu météo pour le mardi 17 février

	nuit	matin	après-midi	soir

Faibles chutes de neige le matin, avant le retour de quelques éclaircies l'après-midi.

Pluie-Neige	800 m	1 000 m		
Iso 0 °C	1 100 m	1 400 m	1 700 m	1 600 m
Vent 2000 m	→ 55 km/h	→ 40 km/h	→ 35 km/h	→ 20 km/h
Vent 3000 m	↘ 95 km/h	↓ 85 km/h	↘ 50 km/h	↘ 55 km/h

Épaisseur de neige hors-piste

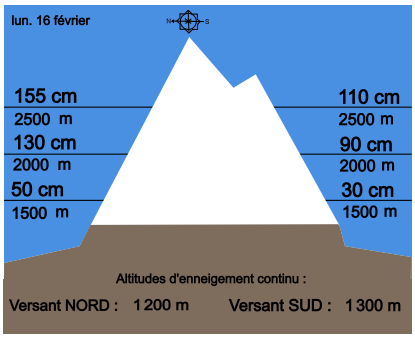

Précipitations à 1800 m

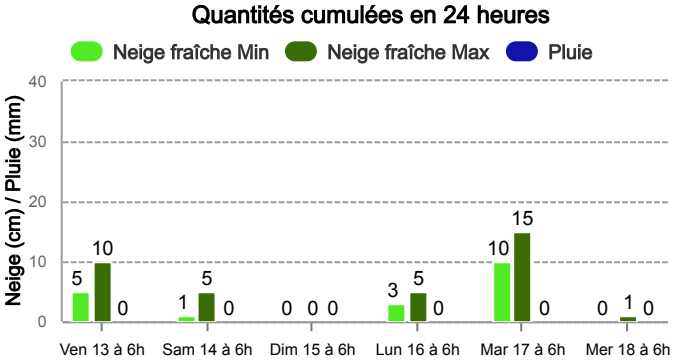

Tendance du mercredi 18 février

3

Indice de risque marqué

Risque restant marqué avec des plaques encore sensibles dans la neige récente, malgré leur stabilisation progressive.

Pour consulter la vigilance en cours, veuillez vous rendre sur le site https://vigilance.meteofrance.fr/fr

Météo-France - 73 avenue de Paris, 94165 Saint-Mandé cedex - Contact : contact@meteo.fr

Rédigé par Météo-France avec la contribution des observateurs du réseau nivo-météorologiques. Partenariat : ANMSM (Maires de Stations de Montagne), DSF (Domaines Skiables de France), ADSP (Directeurs de Pistes et de la Sécurité des Stations de Sports d'Hiver) et autres acteurs de la montagne.

Bulletin neige & avalanches par téléphone au 0 892 68 10 20 Service 0,35 € / min + prix appel

RÉPUBLIQUE FRANÇAISE
Liberté Égalité Fraternité

METEO FRANCE
À VOS CÔTÉS, DANS UN CLIMAT QUI CHANGE

Bulletin d'estimation du risque d'avalanche

(valable en dehors des pistes balisées et ouvertes)

MASSIF : Embrunais Parpaillon

Rédigé le lundi 16 février 2026 à 16h

Conditions nivo-météo des 7 derniers jours

	mar. 10/02				mer. 11/02				jeu. 12/02				ven. 13/02				sam. 14/02				dim. 15/02				lun. 16/02			
	03h	09h	15h	21h	03h	09h	15h	21h	03h	09h	15h	21h	03h	09h	15h	21h	03h	09h	15h	21h	03h	09h	15h	21h	03h	09h	15h	21h
Météo																												
Vent (km/h)	30	45	50	60	70	65	60	40	90	70	90	60	50	30	30	50	60	60	40	70	60	80	50	45	70	110	130	110
à 3000m	→	→	→	→	↘	↘	↘	→	→	↘	↘	↘	↘	↗	↖	←	←	↙	↓	↓	↓	↓	↘	↘	↘	↘	↘	↘
Vent (km/h)	10	15	15	15	20	25	30	25	30	35	45	35	20	10	15	20	25	25	25	30	30	30	20	20	20	60	75	65
à 2000m	→	↗	↗	↗	↗	↘	↗	↗	↗	→	→	→	→	↑	↖	↖	↙	↙	↙	↓	↙	↓	→	→	↘	→	→	→

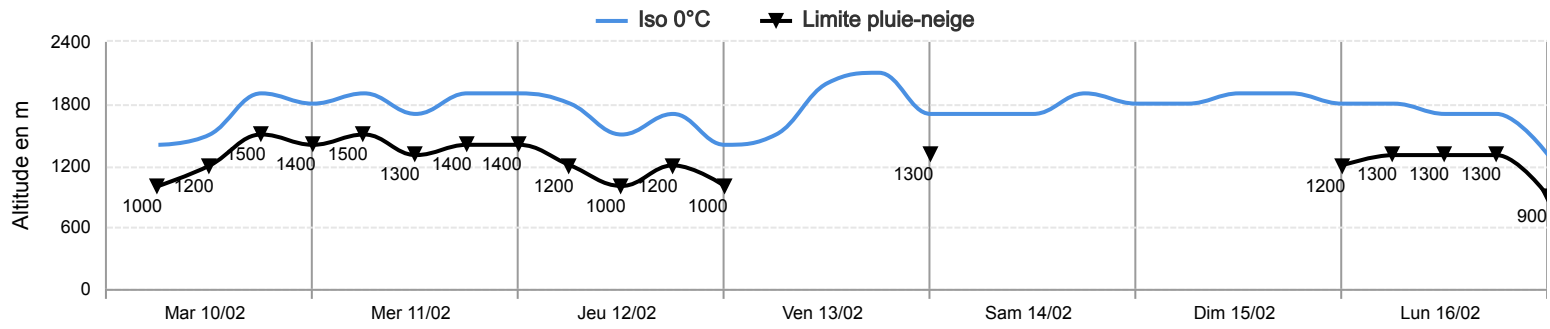

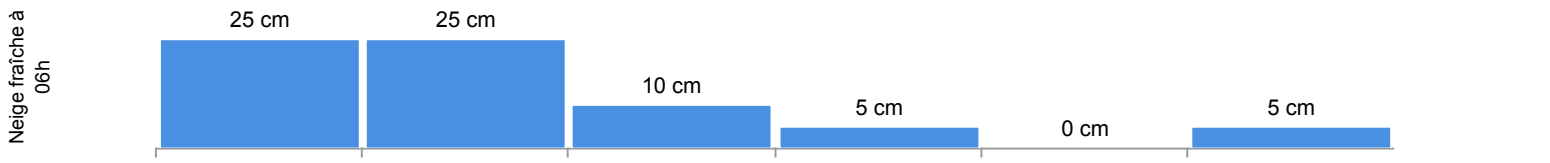

Risque d'avalanche	mar. 10/02	mer. 11/02	jeu. 12/02	ven. 13/02	sam. 14/02	dim. 15/02	lun. 16/02
	3	4	4	4	4	3	3

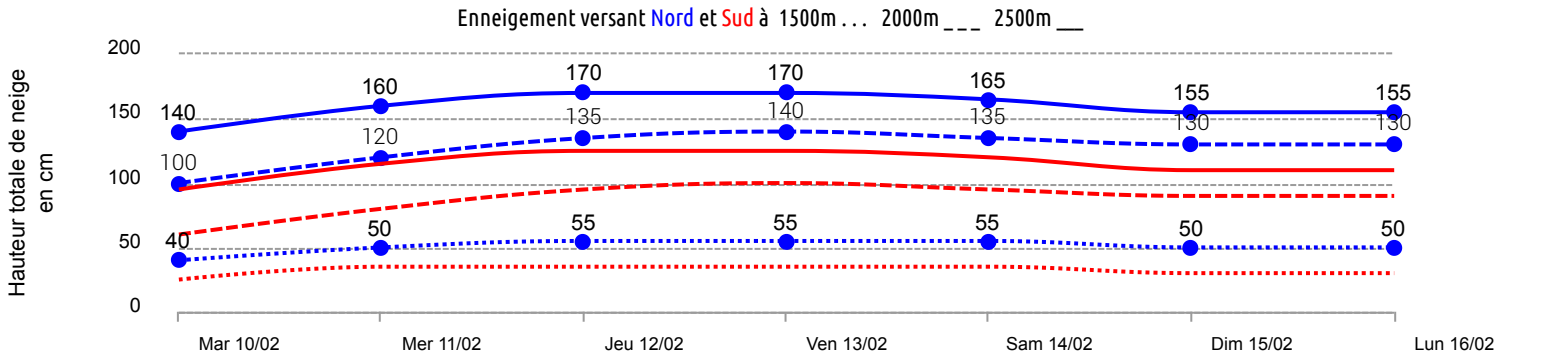

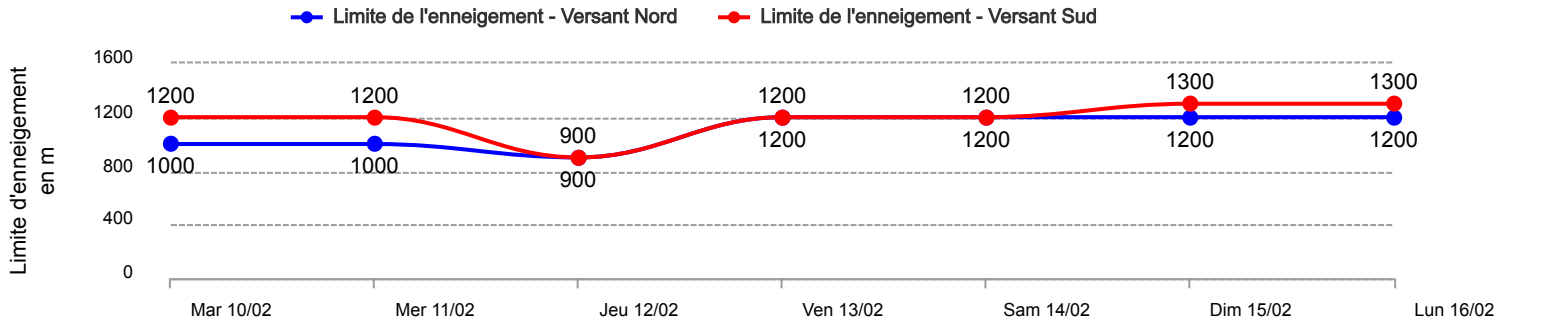

Pour consulter la vigilance en cours, veuillez vous rendre sur le site https://vigilance.meteofrance.fr/fr

Météo-France - 73 avenue de Paris, 94165 Saint-Mandé cedex - Contact : contact@meteo.fr

Rédigé par Météo-France avec la contribution des observateurs du réseau nivo-météorologiques. Partenariat : ANMSM (Maires de Stations de Montagne), DSF (Domaines Skiables de France), ADSP (Directeurs de Pistes et de la Sécurité des Stations de Sports d'Hiver) et autres acteurs de la montagne.

Bulletin neige & avalanches par téléphone au
0 892 68 10 20 Service 0,35 € / min + prix appel