Bulletin d'estimation du risque d'avalanche

(valable en dehors des pistes balisées et ouvertes)

MASSIF : Haut-Var Haut-Verdon

Rédigé le lundi 16 février 2026 à 16h

Estimation des risques pour le : MARDI 17 FÉVRIER

NOMBREUSES INSTABILITÉS DANS LA NEIGE RÉCENTE

3

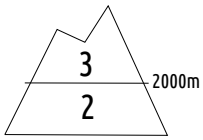

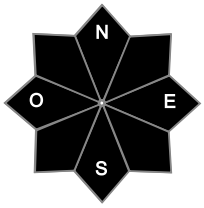

Au-dessus de 2000m indice de risque marqué, plus bas indice limité.

Départs spontanés : avalanches de neige fraîche ventée, parfois de grande taille en Haut Verdon

Déclenchements provoqués : nombreux et facilement déclenchables dans la neige récente

Indices de risque : 5 très fort - 4 fort - 3 marqué - 2 limité - 1 faible -- En noir : les pentes les plus dangereuses

Stabilité du manteau neigeux

Situation avalancheuse typique : neige fraîche couche fragile persistante

Déclenchements provoqués : manteau neigeux faiblement à modérément stabilisé dans de nombreuses pentes d'altitude supérieure à 2000 m environ. Instabilités possibles en toutes orientations, déclenchables par un seul skieur, et engendrant des avalanches de taille petite à moyenne (taille 1 à 2).
Le fort vent d'ouest continue de souffler à haute altitude, favorisant un important transport de neige, et la formation de nombreuses instabilités, même loin des crêtes. Généralement d'aspect dur et plutôt bien identifiables, plus rarement d'aspect poudreux, ces instabilités mobilisent le plus souvent la neige tombée depuis une semaine. Épaisseurs de cassure de l'ordre de 40 à 60 cm en altitude, localement plus dans les zones de forte accumulation par le vent.
En orientation ouest, nord ou est d'altitude supérieure à 2000/2200 m environ, grandes avalanches (taille 3) sont possibles, très grande (taille 4) non exclue dans les pentes d'un large secteur nord de haute altitude du Haut Verdon. La couche fragile persistante enfouie à la base du manteau neigeux est encore localement sollicitable et peut engendrer des départs linéaires de grande largeur. Déclenchement direct peu probable (mais aléatoire) par un skieur isolé, souvent rendu possible, en cascade, par une première avalanche de surface.

Départs spontanés : avalanches de neige fraîche / ventée. Départs parfois linéaires et de taille 2, plus rarement de taille 3 principalement en Haut Verdon, notamment en cas de rupture de corniche en versant froid d'altitude.
L'après-midi, avec le retour du soleil, petits départs ponctuels en neige humide, restant superficiels et de taille 1 à 2.

Qualité de la neige

Enneigement abondant, très excédentaire pour un mois de février.
Données observées : en ubacs, 1 m dès 1600/1700 m, 1m 30 à 1m 90 vers 2000 m, 2 m à 2m 50 vers 2400 m.

Enneigement skiable dès 1200 m en terrains favorables et 1500 m en adrets

État de la neige en surface : 20/40 cm de neige récente souvent fortement travaillée par le vent en altitude, et reposant sur une sous-couche dure, parfois regelée sous 1800 m, et légère et poudreuse en ubacs abrités du vent, notamment en forêts de moyenne altitude.

Aperçu météo pour le mardi 17 février

	nuit	matin	après-midi	soir
	Vent fort et neige en altitude jusqu'en milieu de matinée			
Pluie-Neige	1 000 m			
Iso 0 °C	1 600 m	1 700 m	1 900 m	1 900 m
Vent 2000 m	↘ 65 km/h	↘ 45 km/h	↘ 50 km/h	↘ 40 km/h
Vent 3000 m	↘ 90 km/h	↘ 60 km/h	↘ 60 km/h	↘ 50 km/h

Épaisseur de neige hors-piste

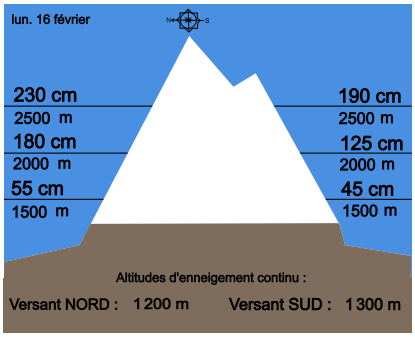

Précipitations à 1800 m

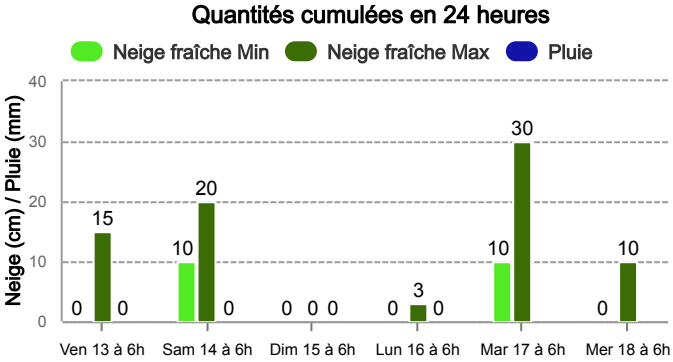

Tendance du mercredi 18 février

3 **Indice de risque marqué**

Temps sec en journée, vent de nord-ouest encore fort en altitude, maintenant une instabilité marquée dans la neige récente

Pour consulter la vigilance en cours, veuillez vous rendre sur le site https://vigilance.meteofrance.fr/fr

Météo-France - 73 avenue de Paris, 94165 Saint-Mandé cedex - Contact : contact@meteo.fr

Rédigé par Météo-France avec la contribution des observateurs du réseau nivo-météorologiques. Partenariat : ANMSM (Maires de Stations de Montagne), DSF (Domaines Skiables de France), ADSP (Directeurs de Pistes et de la Sécurité des Stations de Sports d'Hiver) et autres acteurs de la montagne.

Bulletin neige & avalanches par téléphone au

0 892 68 10 20 Service 0,35 € / min + prix appel

Bulletin d'estimation du risque d'avalanche

(valable en dehors des pistes balisées et ouvertes)

MASSIF : Haut-Var Haut-Verdon

Rédigé le lundi 16 février 2026 à 16h

Conditions nivo-météo des 7 derniers jours

	mar. 10/02				mer. 11/02				jeu. 12/02				ven. 13/02				sam. 14/02				dim. 15/02				lun. 16/02			
	03h	09h	15h	21h	03h	09h	15h	21h	03h	09h	15h	21h	03h	09h	15h	21h	03h	09h	15h	21h	03h	09h	15h	21h	03h	09h	15h	21h
Météo																												
Vent (km/h)	30	35	50	65	100	110	60	70	80	100	140	130	90	30	40	55	70	70	60	40	35	45	45	55	65	85	110	100
à 3000m																												
Vent (km/h)	10	15	20	20	20	20	30	40	80	90	120	115	60	15	20	25	35	45	40	35	5	5	15	35	50	50	80	70
à 2000m																												

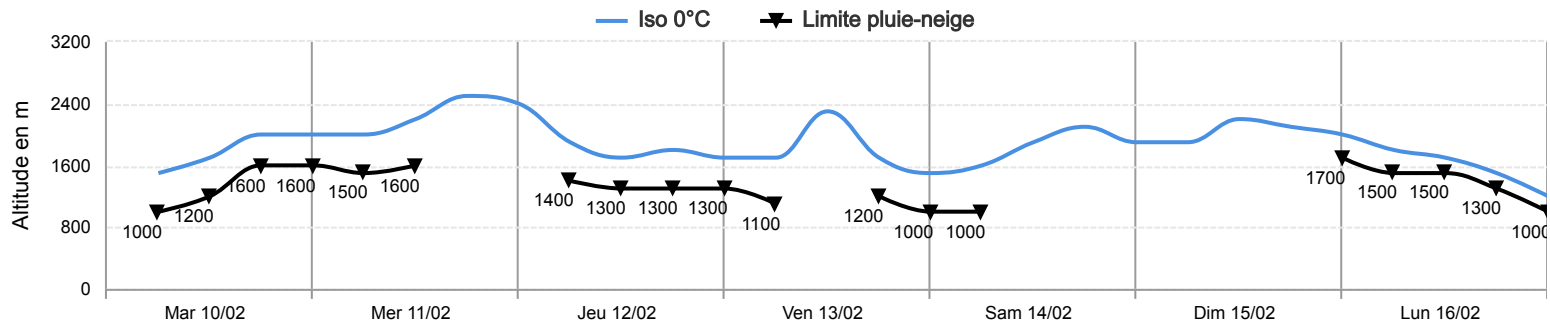

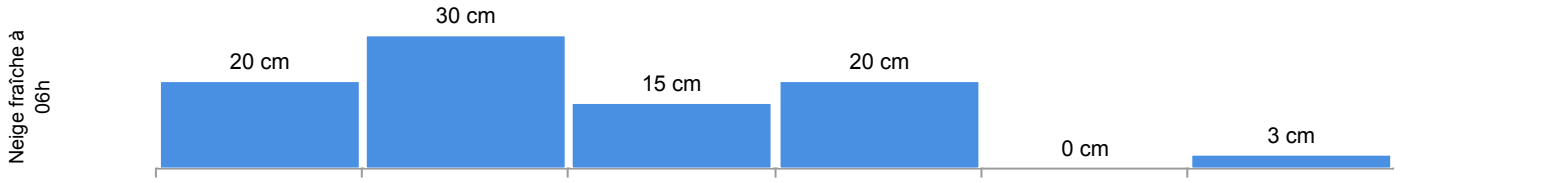

Risque d'avalanche	mar. 10/02	mer. 11/02	jeu. 12/02	ven. 13/02	sam. 14/02	dim. 15/02	lun. 16/02
	3	3	4	4	3	3	3

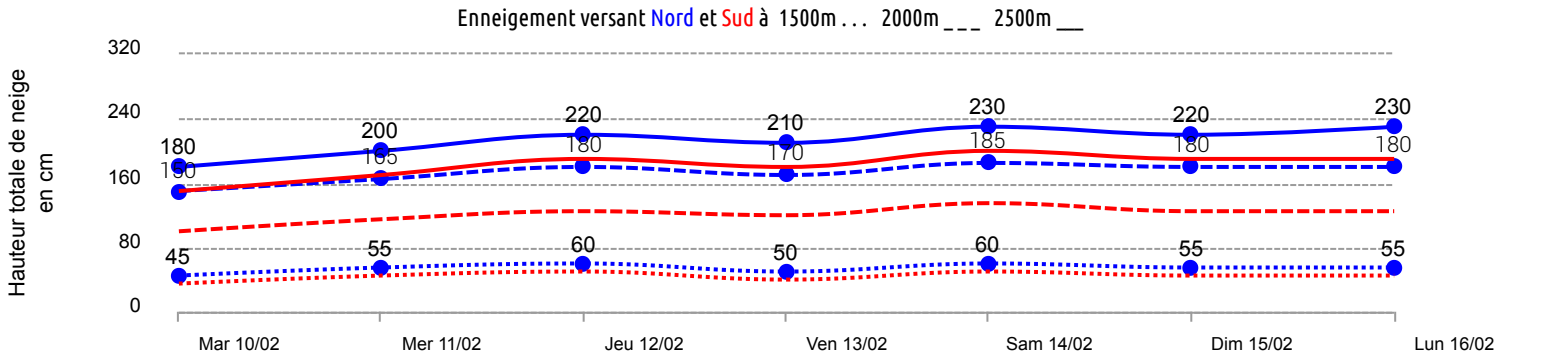

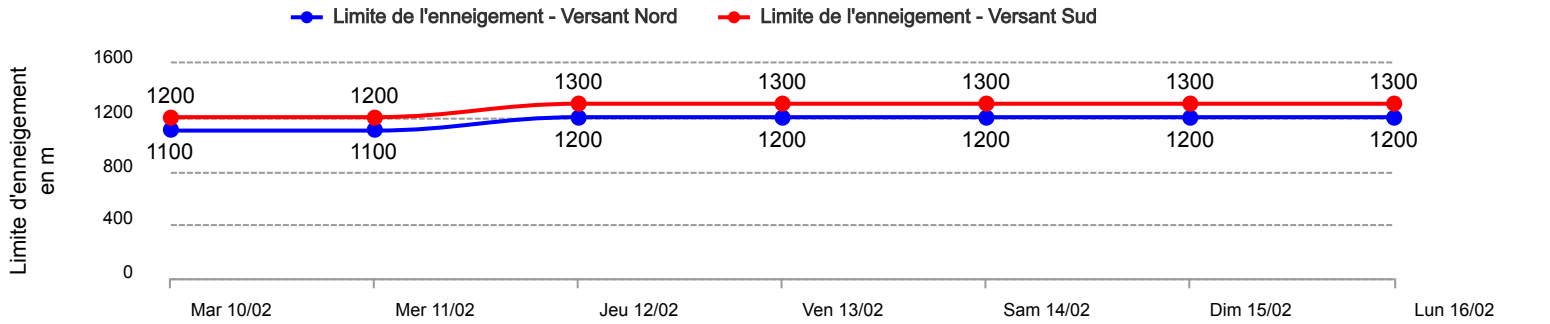

Pour consulter la vigilance en cours, veuillez vous rendre sur le site https://vigilance.meteofrance.fr/fr

Météo-France - 73 avenue de Paris, 94165 Saint-Mandé cedex - Contact : contact@meteo.fr

Rédigé par Météo-France avec la contribution des observateurs du réseau nivo-météorologiques. Partenariat : ANMSM (Maires de Stations de Montagne), DSF (Domaines Skiables de France), ADSP (Directeurs de Pistes et de la Sécurité des Stations de Sports d'Hiver) et autres acteurs de la montagne.

Bulletin neige & avalanches par téléphone au

0 892 68 10 20 Service 0,35 € / min + prix appel