Bulletin d'estimation du risque d'avalanche
(valable en dehors des pistes balisées et ouvertes)

MASSIF : Mercantour

Rédigé le lundi 16 février 2026 à 16h

Estimation des risques pour le : MARDI 17 FÉVRIER

NOMBREUSES INSTABILITÉS DANS LA NEIGE FORTEMENT VENTÉE

3

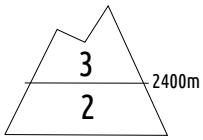

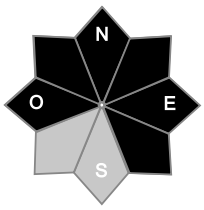

Au-dessus de 2400m indice de risque marqué, plus bas indice limité.

Départs spontanés : sous l'effet du vent, de taille petite à moyenne

Déclenchements provoqués : nombreux et parfois très volumineux dans la neige ventée

Indices de risque : 5 très fort - 4 fort - 3 marqué - 2 limité - 1 faible -- En noir : les pentes les plus dangereuses

Stabilité du manteau neigeux

Situation avalancheuse typique : neige ventée

Déclenchements provoqués : manteau neigeux faiblement à modérément stabilisé dans de nombreuses pentes de haute altitude, généralement au-dessus de 2400 m. Instabilités possibles en toutes orientations, plutôt disséminées en orientations ouest et nord, parfois très épaisses loin des crêtes d'un large secteur est, elles sont plus rares en orientations sud. Parfois déclenchables par un seul skieur, elles engendrent des avalanches de taille petite à moyenne (taille 1 à 2), rarement grandes (taille 3). Le fort vent de nord-ouest continue de souffler à haute altitude, favorisant un important transport de neige, et la formation de nombreuses instabilités, même loin des crêtes. Généralement d'aspect dur et plutôt bien identifiables, plus rarement d'aspect poudreux, ces instabilités mobilisent surtout la neige tombée depuis vendredi soir. Épaisseurs de cassure de l'ordre de 30 à 50 cm en altitude, localement plus dans les zones de forte accumulation par le vent. Le déclenchement des couches fragiles persistantes situées à la base de l'épais manteau neigeux est très peu probable par un seul skieur ; on ne peut cependant l'exclure en cascade, par une avalanche de neige ventée particulièrement volumineuse, ce qui peut engendrer alors une avalanche de très grande taille (taille 4).

Départs spontanés : avalanches de neige ventée. Départs parfois linéaires et de taille 2, plus rarement de taille 3, notamment en cas de rupture de corniche en versant froid d'altitude.
L'après-midi, avec le retour du soleil,rares départs ponctuels en neige humide, restant superficiels et de taille 1.

Qualité de la neige

Enneigement abondant, excédentaire pour un mois de février.
Données observées : 156 cm à la nivôse de Millefonts, 127 cm à Isola 2000.

Enneigement skiable dès 1200 m en terrains favorables et 1500 m en adrets

État de la neige en surface : fortement durcie par le vent en altitude, y compris en Haute Tinée vers la Bonette où il est tombé 10/20 cm de neige lundi. Encore meuble en ubacs forestiers de moyenne altitude, s'humidifiant au soleil ce mardi.

Aperçu météo pour le mardi 17 février

	nuit	matin	après-midi	soir
	bien ensoleillé, mais fort vent de nord / nord-ouest en altitude			
Pluie-Neige				
Iso 0 °C	1 700 m	1 800 m	2 100 m	2 100 m
Vent 2000 m	↓ 60 km/h	↓ 50 km/h	↓ 50 km/h	↘ 20 km/h
Vent 3000 m	↓ 75 km/h	↓ 70 km/h	↓ 70 km/h	↘ 25 km/h

Épaisseur de neige hors-piste

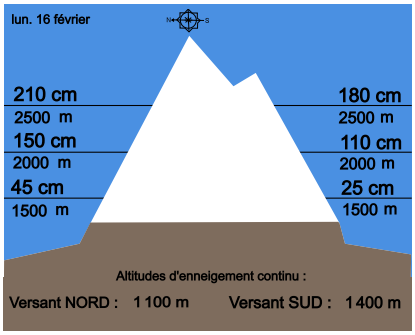

Précipitations à 1800 m

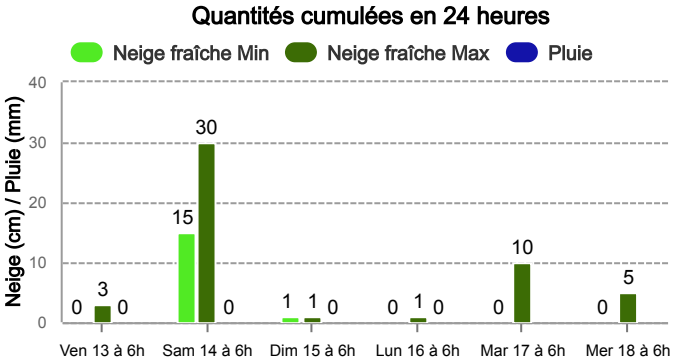

Tendance du mercredi 18 février

3

Indice de risque marqué

Temps sec en journée, vent de nord-ouest encore fort en altitude, maintenant une instabilité marquée

Pour consulter la vigilance en cours, veuillez vous rendre sur le site https://vigilance.meteofrance.fr/fr

Météo-France - 73 avenue de Paris, 94165 Saint-Mandé cedex - Contact : contact@meteo.fr

Rédigé par Météo-France avec la contribution des observateurs du réseau nivo-météorologiques. Partenariat : ANMSM (Maires de Stations de Montagne), DSF (Domaines Skiables de France), ADSP (Directeurs de Pistes et de la Sécurité des Stations de Sports d'Hiver) et autres acteurs de la montagne.

Bulletin neige & avalanches par téléphone au
0 892 68 10 20 Service 0,35 € / min + prix appel

RÉPUBLIQUE FRANÇAISE
Liberté Égalité Fraternité

METEO FRANCE
À VOS CÔTÉS, DANS UN CLIMAT QUI CHANGE

Bulletin d'estimation du risque d'avalanche

(valable en dehors des pistes balisées et ouvertes)

MASSIF : Mercantour

Rédigé le lundi 16 février 2026 à 16h

Conditions nivo-météo des 7 derniers jours

	mar. 10/02				mer. 11/02				jeu. 12/02				ven. 13/02				sam. 14/02				dim. 15/02				lun. 16/02			
	03h	09h	15h	21h	03h	09h	15h	21h	03h	09h	15h	21h	03h	09h	15h	21h	03h	09h	15h	21h	03h	09h	15h	21h	03h	09h	15h	21h
Météo																												
Vent (km/h)	35	40	50	65	80	75	50	70	85	95	90	85	55	30	40	50	80	90	75	65	45	30	40	50	55	75	100	80
à 3000m																												
Vent (km/h)	10	15	20	20	30	40	35	25	40	65	45	40	30	20	25	20	50	75	65	50	30	10	20	30	30	40	65	40
à 2000m																												

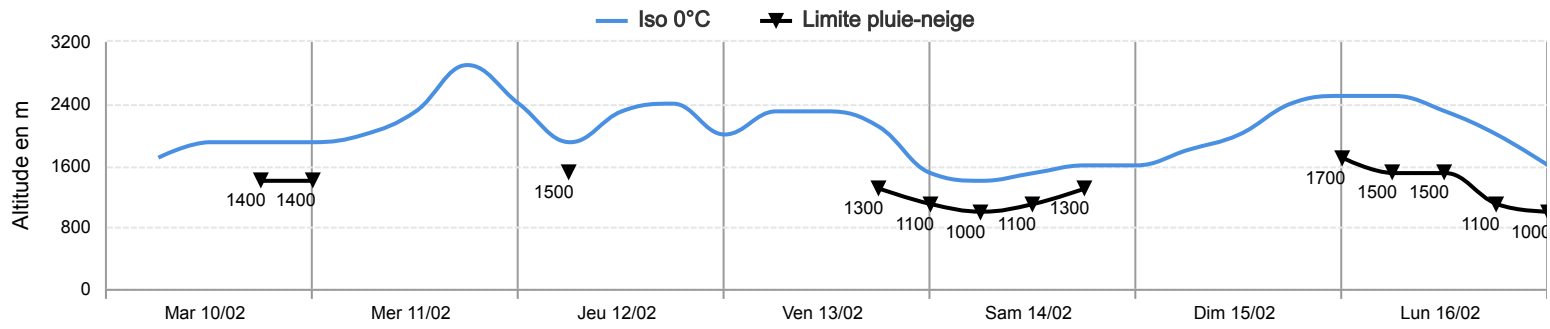

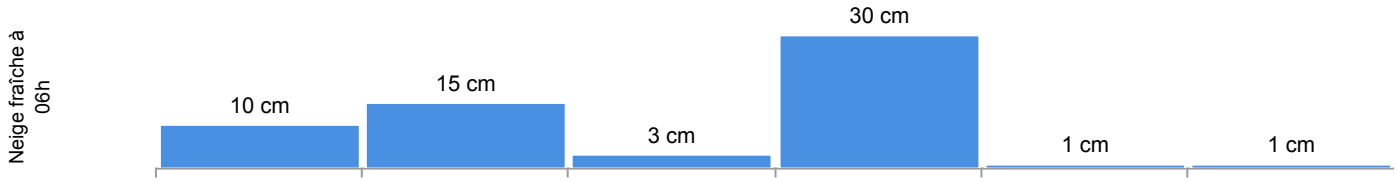

Risque d'avalanche	mar. 10/02	mer. 11/02	jeu. 12/02	ven. 13/02	sam. 14/02	dim. 15/02	lun. 16/02
	3	3	2	2	3	3	3

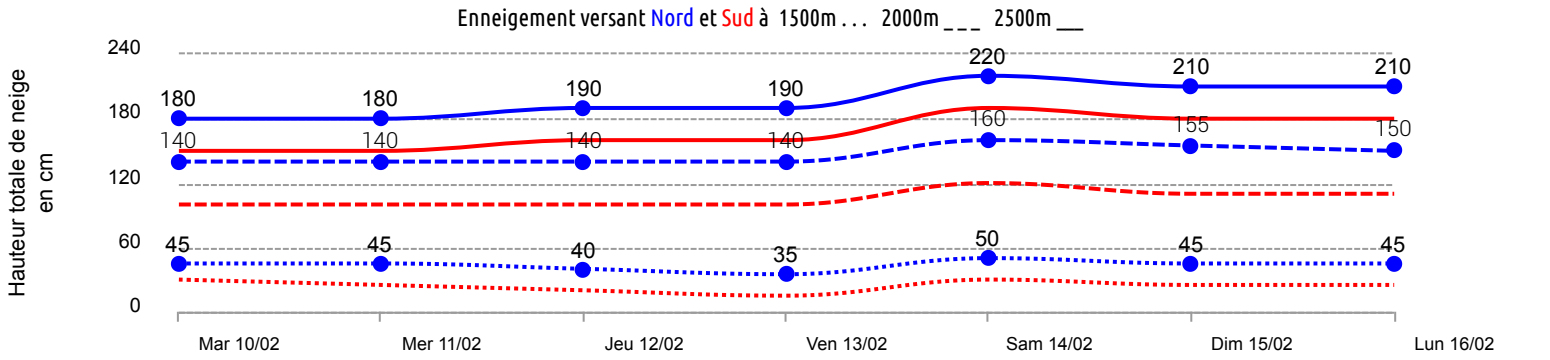

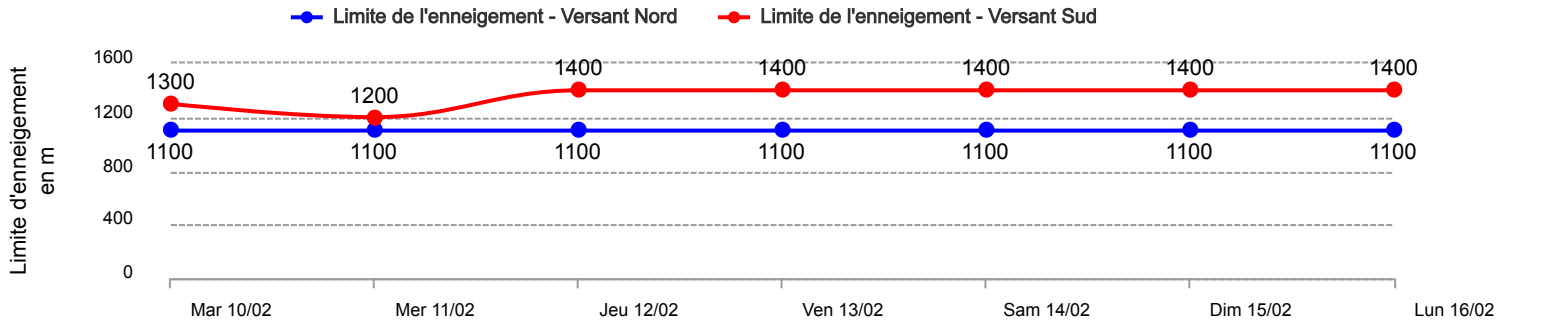

Pour consulter la vigilance en cours, veuillez vous rendre sur le site https://vigilance.meteofrance.fr/fr

Météo-France - 73 avenue de Paris, 94165 Saint-Mandé cedex - Contact : contact@meteo.fr

Rédigé par Météo-France avec la contribution des observateurs du réseau nivo-météorologiques. Partenariat : ANMSM (Maires de Stations de Montagne), DSF (Domaines Skiables de France), ADSP (Directeurs de Pistes et de la Sécurité des Stations de Sports d'Hiver) et autres acteurs de la montagne.

Bulletin neige & avalanches par téléphone au

0 892 68 10 20 Service 0,35 € / min + prix appel