Bulletin d'estimation du risque d'avalanche

(valable en dehors des pistes balisées et ouvertes)

MASSIF : Pays-Basque

Rédigé le lundi 16 février 2026 à 16h

Estimation des risques pour le : MARDI 17 FÉVRIER

HUMIDIFICATION RAPIDE DU MANTEAU NEIGEUX.

3

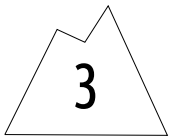

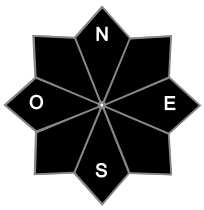

Indice de risque marqué.

Départs spontanés : Nombreux, en neige humide.

Déclenchements provoqués : Quelques plaques.

Indices de risque : 5 très fort - 4 fort - 3 marqué - 2 limité - 1 faible -- En noir : les pentes les plus dangereuses

Stabilité du manteau neigeux

Situation avalancheuse typique : neige ventée avalanches de fond

Départs spontanés : le redoux et les pluies jusque vers 2100 à 2200 m ont humidifié le manteau neigeux en place. Des **avalanches de neige humide et de fond** sont possibles en **toutes orientations** ce lundi, parfois la nuit et demain avec la douceur des nuées en journée mardi. Ces avalanches seront fréquemment de taille 2 voire de taille 3 et, localement, de taille 4 en partant des secteurs déventés en large Sud à Est, où les accumulations de neige sont les plus importantes. Ces avalanches sont susceptibles de s'approcher de quelques routes ou infrastructures.

Déclenchements provoqués : Au-dessus de 2000 m la nuit de lundi à mardi, avec les chutes de neige par refroidissement quelques fines plaques se forment sous le vent de nord-ouest au-dessus de 1800 m puis 1500 m, facilement déclenchables cette nuit en haut du massif vers 2200 m, elles deviennent plus humidifiées mardi en journée jusqu'à 2000 m et tendent à se stabiliser. Quelques avalanches de taille 1 seraient possibles par surchage de'un randonneur.

Qualité de la neige

Enneigement : Enneigement en léger retrait, avec toujours crêtes, cols et sommets en expositions ouest souvent pelés, ou à présent en glace. Manteau neigeux débutant vers 1250 m, épais à partir de 1500 m en en zones déventées, humidifié avec un peu de neige fraîche en surface déposée la nuit vers mardi et se tassant vite, fondant même sous 1800 m en après-midi.
Limites skiables : à partir de 1300 à 1500 m mardi matin, mais remontant fortement en journée sous le temps doux et pluvieux.
État de la neige : Sous-couche humidifiée, neige en surface rapidement humide sous 1900 m, alourdie au-dessus.

Aperçu météo pour le mardi 17 février

nuit	matin	après-midi	soir

Petites chutes de neige cette nuit et faiblement mardi matin en ciel bouché, nuages et éclaircies en après-midi, ciel voilé la nuit vers mercredi.

Pluie-Neige	1 300 m	1 800 m	1 900 m	
Iso 0 °C	1 600 m	2 000 m	2 100 m	2 300 m
Vent 1000 m	↘ 35 km/h	↘ 30 km/h	→ 25 km/h	↗ 20 km/h
Vent 2000 m	↘ 90 km/h	→ 60 km/h	↘ 50 km/h	↗ 50 km/h

Épaisseur de neige hors-piste

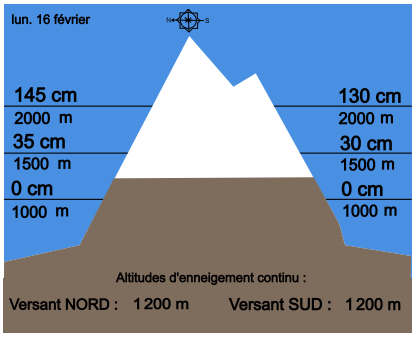

Précipitations à 1800 m

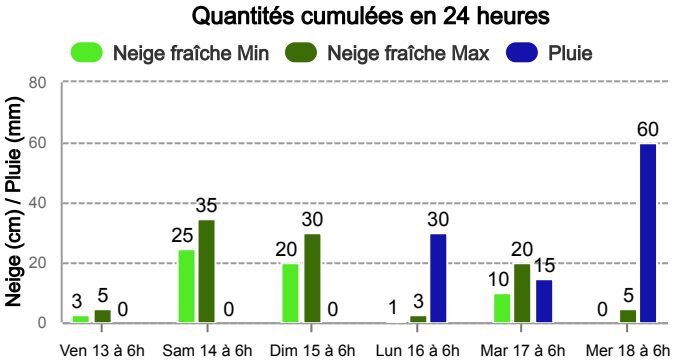

Tendance du mercredi 18 février

3

Indice de risque marqué

Avalanches de neige humide et de fond par redoux et ensoleillement.

Pour consulter la vigilance en cours, veuillez vous rendre sur le site https://vigilance.meteofrance.fr/fr

Météo-France - 73 avenue de Paris, 94165 Saint-Mandé cedex - Contact : contact@meteo.fr

Rédigé par Météo-France avec la contribution des observateurs du réseau nivo-météorologiques. Partenariat : ANMSM (Maires de Stations de Montagne), DSF (Domaines Skiables de France), ADSP (Directeurs de Pistes et de la Sécurité des Stations de Sports d'Hiver) et autres acteurs de la montagne.

Bulletin neige & avalanches par téléphone au

0 892 68 10 20 Service 0,35 € / min + prix appel

Bulletin d'estimation du risque d'avalanche

(valable en dehors des pistes balisées et ouvertes)

MASSIF : Pays-Basque

Rédigé le lundi 16 février 2026 à 16h

Conditions nivo-météo des 7 derniers jours

	mar. 10/02				mer. 11/02				jeu. 12/02				ven. 13/02				sam. 14/02				dim. 15/02				lun. 16/02			
	03h	09h	15h	21h	03h	09h	15h	21h	03h	09h	15h	21h	03h	09h	15h	21h	03h	09h	15h	21h	03h	09h	15h	21h	03h	09h	15h	21h
Météo																												
Vent (km/h)	70	90	90	80	70	80	100	120	120	110	80	75	110	110	85	90	100	75	80	60	40	70	80	85	80	80	90	110
à 2000m	↗	↗	↗	↗	↗	↗	↗	↗	↗	→	↘	↗	↑	↑	→	↘	↓	↓	↘	↓	↘	↘	↘	↘	↘	↘	↘	↘
Vent (km/h)	50	60	65	50	40	50	70	80	80	70	40	35	50	65	55	55	60	40	45	25	15	15	20	25	35	35	45	50
à 1000m	↗	↗	↗	→	→	↑	↑	↗	↗	→	↘	↗	↗	↑	↗	↘	↓	↓	↓	↓	↙	↘	→	↗	↗	→	↓	↓

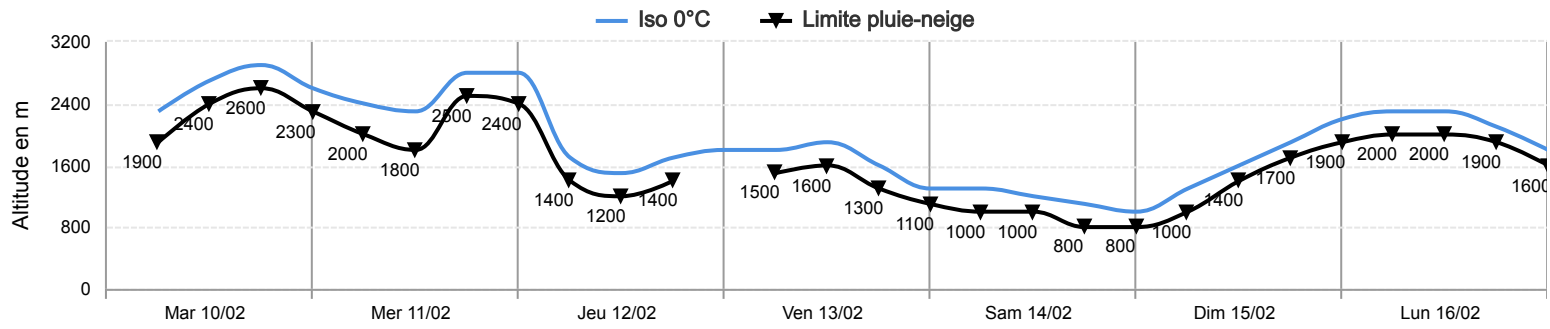

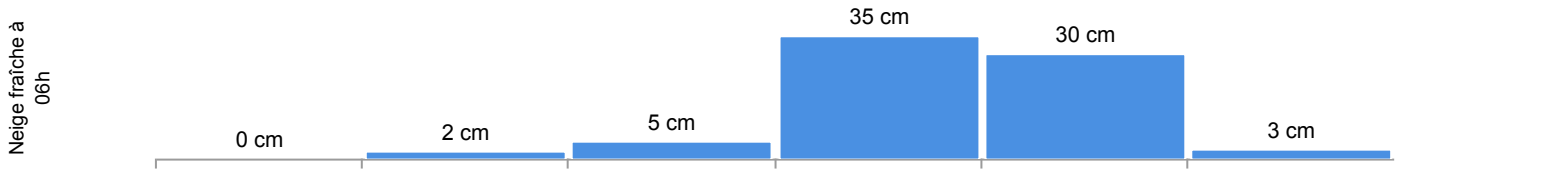

Risque d'avalanche	mar. 10/02	mer. 11/02	jeu. 12/02	ven. 13/02	sam. 14/02	dim. 15/02	lun. 16/02
	3	3	2	2	3	3	3

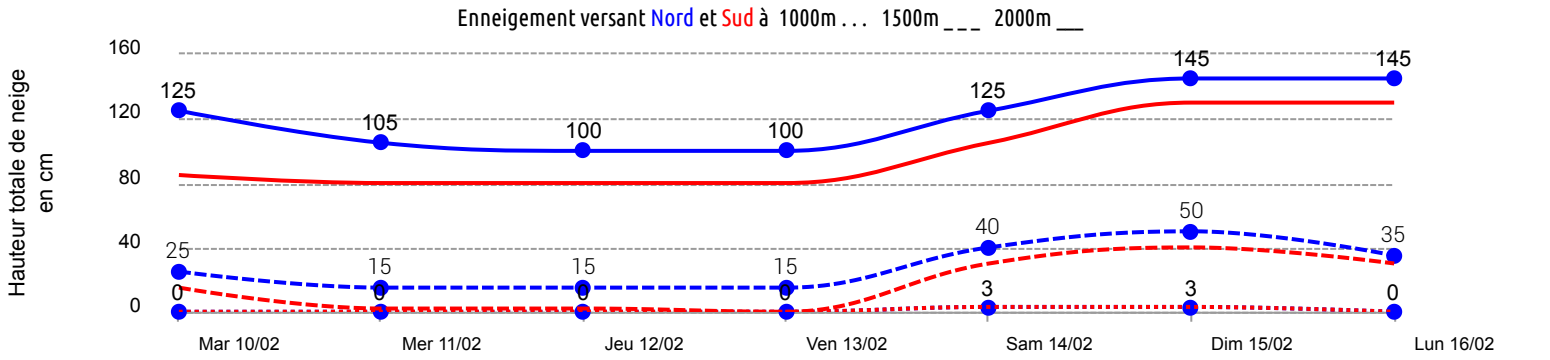

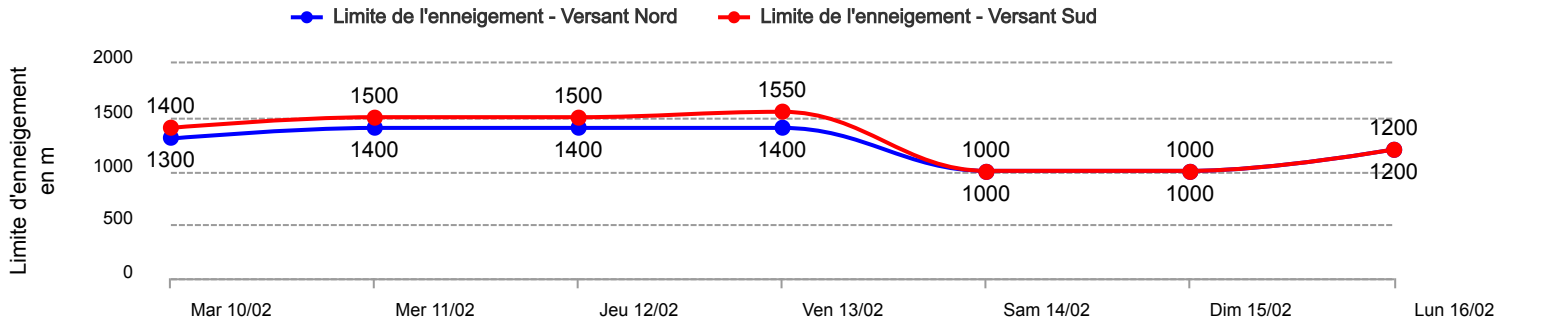

Pour consulter la vigilance en cours, veuillez vous rendre sur le site https://vigilance.meteofrance.fr/fr

Météo-France - 73 avenue de Paris, 94165 Saint-Mandé cedex - Contact : contact@meteo.fr

Bulletin neige & avalanches par téléphone au

0 892 68 10 20 Service 0,35 € / min + prix appel

Rédigé par Météo-France avec la contribution des observateurs du réseau nivo-météorologiques. Partenariat : ANMSM (Maires de Stations de Montagne), DSF (Domaines Skiables de France), ADSP (Directeurs de Pistes et de la Sécurité des Stations de Sports d'Hiver) et autres acteurs de la montagne.