Bulletin d'estimation du risque d'avalanche

(valable en dehors des pistes balisées et ouvertes)

MASSIF : Pelvoux

Rédigé le lundi 16 février 2026 à 16h

Estimation des risques pour le : MARDI 17 FÉVRIER

MANTEAU NEIGEUX TRÈS INSTABLE - CHUTES DE NEIGE ACCOMPAGNÉES D'UN VENT TEMPÉTUEUX

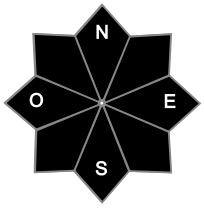

Indice de risque fort.

Départs spontanés : nombreuses avalanches de neige fraîche en cours de nuit, souvent de grande taille, moins fréquentes en cours de journée mardi.

Déclenchements provoqués : nombreuses plaques dans la neige fraiche, même à moyenne altitude.

Indices de risque : 5 très fort - 4 fort - 3 marqué - 2 limité - 1 faible -- En noir : les pentes les plus dangereuses

Stabilité du manteau neigeux

Situation avalancheuse typique : neige fraîche couche fragile persistante

Déclenchements provoqués : de nombreuses plaques très instables sont en place et en formation dans la neige fraîche, fortement ventées jusqu'en basse montagne. Ces instabilités sont plus fréquentes à moyenne altitude, même dans des secteurs plutôt abrités des vents habituellement (forêts peu denses par exemple). Près des crêtes et sommets, ces plaques sont réparties de façon plus hétérogène. Elles sont situées dans des accumulations localement épaisses qui côtoient des secteurs décapés par le vent tempétueux. Avalanches généralement de grande taille (taille 3), une très grande avalanche (taille 4) non exclue, en cas sollicitation d'une couche fragile persistante enfouie en ubac, emportant une grande partie du manteau neigeux en place. Ce type de départ peut être initié par la surcharge liée au passage d'une première avalanche de surface.

Départs spontanés : nombreux départs en cours de nuit de lundi à mardi dans la neige fraîche ventée, générant des avalanches moyennes (taille 2), voire grandes (taille 3) dans les pentes les plus chargées par le vent. Une rare très grande avalanche possible (taille 4) en ubacs d'altitudes. Les départs sont moins fréquents en journée de mardi avec l'affaiblissement du vent et des chutes de neige.

Qualité de la neige

L'enneigement est excédentaire pour un mois de février. Les chutes de neige se succèdent depuis le début du mois de janvier.
Hauteurs de neige observées : 282 cm à la Nivôse de Écrins vers 3000 m, 252 cm au Pré de Mme Carle à 1900 m, 145 cm au hameau de Dormillouse à 1730 m.

Limite d'enneigement skiable : la plupart des itinéraires sont skiables dès les fonds de vallées.
État de la neige de surface : couche de neige fraiche en surface fortement travaillée par le vent dans la plupart des pentes au dessus de 1800/2000. Crêtes décapées par le vent de nord-ouest, et grosses accumulations/corniches en formation. Neige restant localement plus légère et froide en toutes orientations dans les secteurs bien abrités du vent.

Aperçu météo pour le mardi 17 février

	nuit	matin	après-midi	soir

Faibles chutes de neige, avant le retour de quelques éclaircies à partir de la mi-journée.

Pluie-Neige	800 m	1 000 m		
Iso 0 °C	1 100 m	1 400 m	1 700 m	1 900 m
Vent 2000 m	↘ 70 km/h	↘ 55 km/h	↘ 50 km/h	↘ 30 km/h
Vent 3000 m	↘ 90 km/h	↘ 80 km/h	↘ 65 km/h	↘ 55 km/h

Épaisseur de neige hors-piste

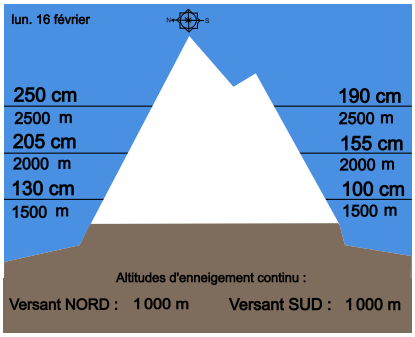

Précipitations à 1800 m

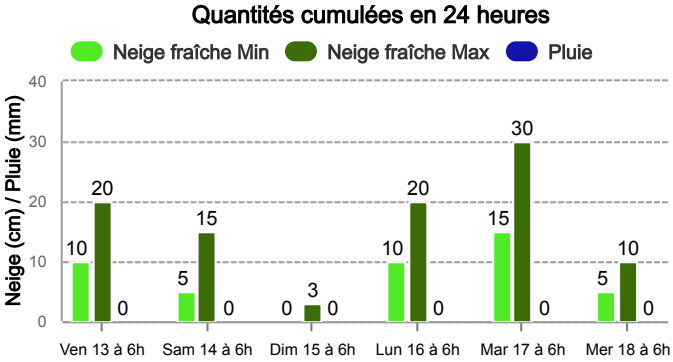

Tendance du mercredi 18 février

Indice de risque marqué

Risque en baisse mais restant marqué avec la stabilisation progressive des plaques en place dans la neige récente.

Pour consulter la vigilance en cours, veuillez vous rendre sur le site https://vigilance.meteofrance.fr/fr

Météo-France - 73 avenue de Paris, 94165 Saint-Mandé cedex - Contact : contact@meteo.fr

Rédigé par Météo-France avec la contribution des observateurs du réseau nivo-météorologiques. Partenariat : ANMSM (Maires de Stations de Montagne), DSF (Domaines Skiables de France), ADSP (Directeurs de Pistes et de la Sécurité des Stations de Sports d'Hiver) et autres acteurs de la montagne.

Bulletin neige & avalanches par téléphone au 0 892 68 10 20 Service 0,35 € / min + prix appel

Bulletin d'estimation du risque d'avalanche

(valable en dehors des pistes balisées et ouvertes)

MASSIF : Pelvoux

Rédigé le lundi 16 février 2026 à 16h

Conditions nivo-météo des 7 derniers jours

	mar. 10/02				mer. 11/02				jeu. 12/02				ven. 13/02				sam. 14/02				dim. 15/02				lun. 16/02			
	03h	09h	15h	21h	03h	09h	15h	21h	03h	09h	15h	21h	03h	09h	15h	21h	03h	09h	15h	21h	03h	09h	15h	21h	03h	09h	15h	21h
Météo																												
Vent (km/h)	30	30	30	80	70	70	50	50	90	80	120	110	65	25	25	30	40	40	60	70	80	80	60	45	70	90	130	110
à 3000m																												
Vent (km/h)	10	15	20	20	20	20	30	25	30	35	65	55	35	15	20	15	15	15	30	45	40	35	30	25	30	60	80	70
à 2000m																												

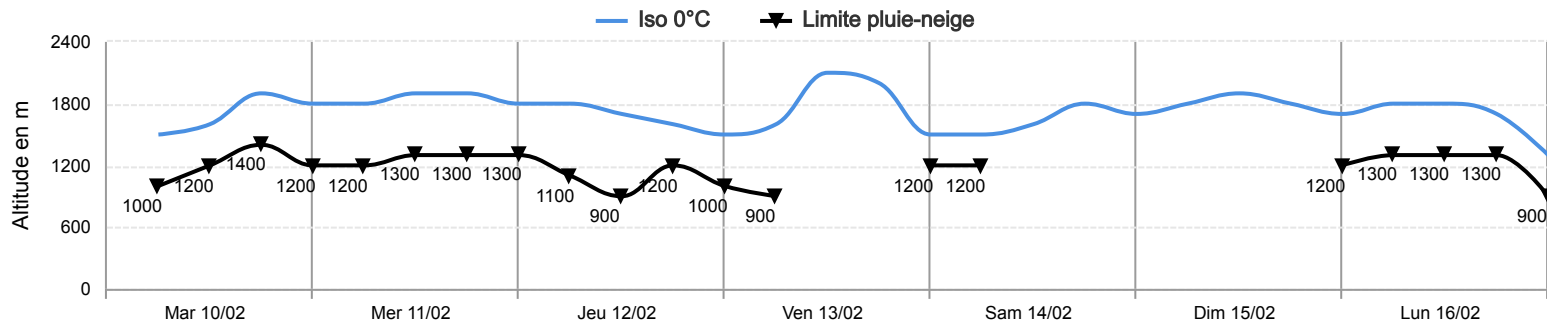

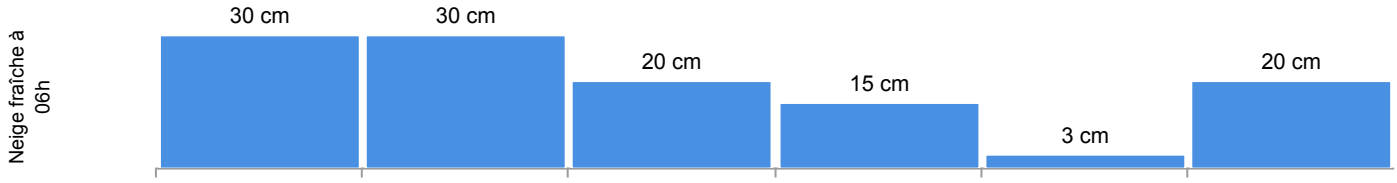

Risque d'avalanche	mar. 10/02	mer. 11/02	jeu. 12/02	ven. 13/02	sam. 14/02	dim. 15/02	lun. 16/02
	3	4	4	4	4	3	4

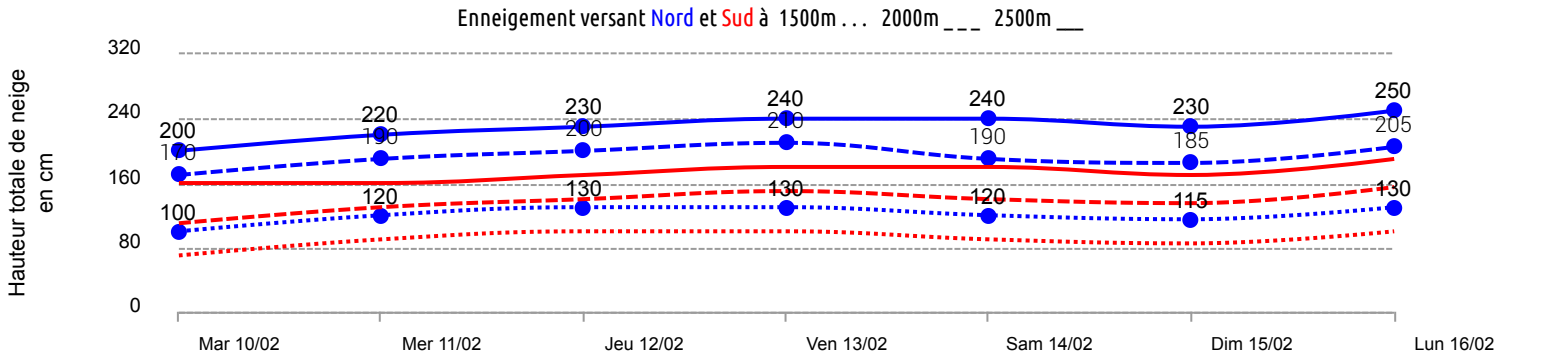

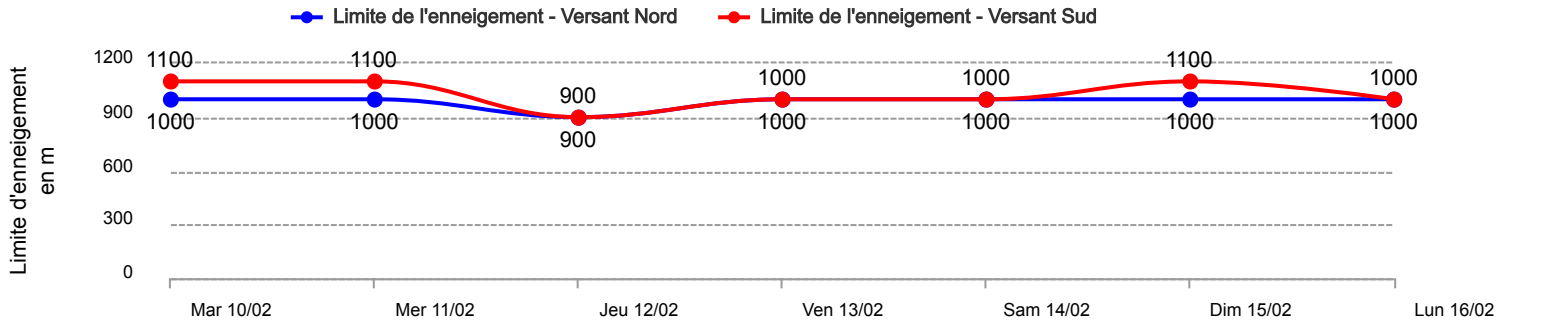

Pour consulter la vigilance en cours, veuillez vous rendre sur le site https://vigilance.meteofrance.fr/fr

Météo-France - 73 avenue de Paris, 94165 Saint-Mandé cedex - Contact : contact@meteo.fr

Bulletin neige & avalanches par téléphone au

0 892 68 10 20 Service 0,35 € / min + prix appel

Rédigé par Météo-France avec la contribution des observateurs du réseau nivo-météorologiques. Partenariat : ANMSM (Maires de Stations de Montagne), DSF (Domaines Skiables de France), ADSP (Directeurs de Pistes et de la Sécurité des Stations de Sports d'Hiver) et autres acteurs de la montagne.