RÉPUBLIQUE FRANÇAISE
Liberté Égalité Fraternité

METEO FRANCE
À VOS CÔTÉS, DANS UN CLIMAT QUI CHANGE

Bulletin d'estimation du risque d'avalanche

(valable en dehors des pistes balisées et ouvertes)

MASSIF : Capcir Puymorens

Rédigé le lundi 16 février 2026 à 17h

Estimation des risques pour le : MARDI 17 FÉVRIER

RISQUE FORT EN ALTITUDE DE DÉCLENCHEMENTS PROVOQUÉS PAR FAIBLE SURCHARGE DANS LA NEIGE FRAÎCHE

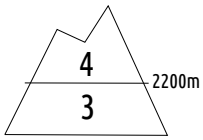

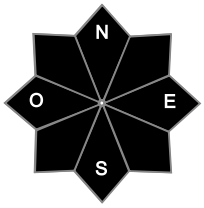

Toutes orientations

Au-dessus de 2200m indice de risque fort, plus bas indice marqué.

Départs spontanés : Départs ponctuels ou linéaires dans la neige fraîche

Déclenchements provoqués : Instabilité temporaire dans la neige fraîche et ventée d'altitude, cassures importantes avec propagation

Indices de risque : 5 très fort - 4 fort - 3 marqué - 2 limité - 1 faible -- En noir : les pentes les plus dangereuses

Stabilité du manteau neigeux

Situation avalancheuse typique : neige fraîche neige humide

Départs spontanés :

Neige humide

Sous 18002000m le manteau neigeux est fortement humidifié même si en surface on pourra trouver un peu de neige fraîche. Des avalanches de taille 3 emportant l'ensemble du manteau neigeux jusqu'au sol dans les couloirs qui ne se seraient pas encore purgés sont de moins en moins probable au fur et à mesure du refroidissement de la soirée et de la nuit. Demain la remontée de l'isotherme 0 °C vers 2300 et les éclaircies devraient favoriser la reprise de quelques avalanches en neige humide surtout au soleil emportant toute la neige récente, plutôt de taille 1 à rarement 3.

Neige fraîche

En altitude, 10 à 30 cm de neige fraîche en 24h mardi au lever du jour s'ajoutent aux cumuls des jours précédents ; les cumuls de 5 à localement 10 cm en journée et/ou la neige transportée par le vent suffisent par surcharge à provoquer des avalanches pouvant emporter l'ensemble des chutes de neige récente avec des tailles moyenne à grande (taille 2 à 3) voire très grande (T4) dans dans un vaste secteur Est où de grosses accumulations se sont produites par le vent de Nord-Ouest.

Déclenchements provoqués :

En tous versants, en général au-dessus de 2200m où le manteau neigeux est resté froid et sec, de nombreuses plaques friables se sont formées et se forment encore avec les chutes de neige. Elles sont facilement déclenchables au passage d'un simple skieur ou randonneur. Le vent favorise lui aussi la formation de plaques à vent parfois loin des crêtes. Les avalanches sont avec des cassures pouvant dépasser les 70 cm, voire 1m dans les pentes d'un large secteur EST d'altitude, favorables aux accumulations.
Observables : quantité de neige fraiche critique (>50 cm), fissures sous les skis, "Whoumf", couverture de neige hétérogène en surface, corniches.

Qualité de la neige

Enneigement :

Enneigement très bon sur nos massifs, au-dessus des normales et nettement supérieur à celui des cinq dernières années. L'enneigement débute vers 1300m devient conséquent dès 1500m. La barre des 2m de neige est souvent atteinte dès 2000m d'altitude.

Qualité de la neige : Dégradation importante à basse altitude

Mardi matin on trouvera un peu de neige fraîche reposant sur un manteau plus ou moins humidifié jusqu'à 2200m.
A partir de 2200m environ on trouve une neige poudreuse dans les vallons et secteurs abrités du vent, une neige travaillée par le vent ailleurs.
Les plus hauts sommets peuvent se retrouver décapés par le vent violent.

Aperçu météo pour le mardi 17 février

	nuit	matin	après-midi	soir
	Journée très nuageuse en ventée			
Pluie-Neige	1 500 m			
Iso 0 °C	2 100 m	2 000 m	2 300 m	2 400 m
Vent 2000 m	90 km/h	60 km/h	45 km/h	35 km/h
Vent 3000 m	95 km/h	75 km/h	60 km/h	50 km/h

Épaisseur de neige hors-piste

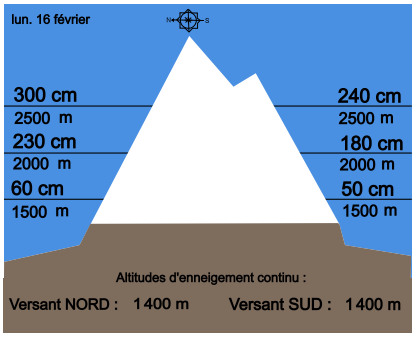

Précipitations à 1800 m

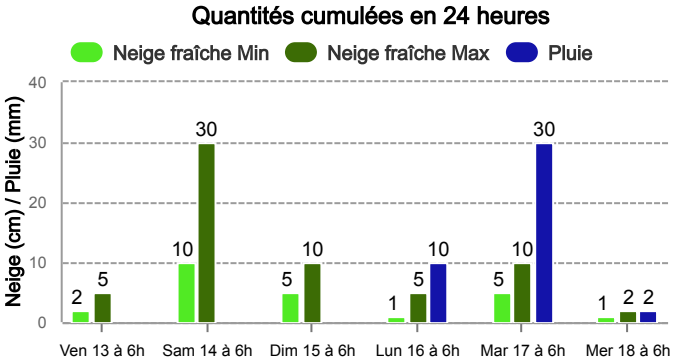

Tendance du mercredi 18 février

Indice de risque marqué

Avalanches au soleil avec la remontée de l'isotherme 0 °C, déclenchements possibles par faible surcharge dans de nombreuses pentes

Pour consulter la vigilance en cours, veuillez vous rendre sur le site https://vigilance.meteofrance.fr/fr

Météo-France - 73 avenue de Paris, 94165 Saint-Mandé cedex - Contact : contact@meteo.fr

Rédigé par Météo-France avec la contribution des observateurs du réseau nivo-météorologiques. Partenariat : ANMSM (Maires de Stations de Montagne), DSF (Domaines Skiables de France), ADSP (Directeurs de Pistes et de la Sécurité des Stations de Sports d'Hiver) et autres acteurs de la montagne.

Bulletin neige & avalanches par téléphone au
0 892 68 10 20 Service 0,35 € / min + prix appel

RÉPUBLIQUE FRANÇAISE
Liberté Égalité Fraternité

METEO FRANCE
À VOS CÔTÉS, DANS UN CLIMAT QUI CHANGE

Bulletin d'estimation du risque d'avalanche

(valable en dehors des pistes balisées et ouvertes)

MASSIF : Capcir Puymorens

Rédigé le lundi 16 février 2026 à 17h

Conditions nivo-météo des 7 derniers jours

	mar. 10/02				mer. 11/02				jeu. 12/02				ven. 13/02				sam. 14/02				dim. 15/02				lun. 16/02			
	03h	09h	15h	21h	03h	09h	15h	21h	03h	09h	15h	21h	03h	09h	15h	21h	03h	09h	15h	21h	03h	09h	15h	21h	03h	09h	15h	21h
Météo																												
Vent (km/h)	70	70	80	85	65	60	55	65	90	110	105	85	55	60	50	90	80	100	110	90	105	80	70	70	65	80	90	100
à 3000m																												
Vent (km/h)	35	40	50	60	50	50	35	45	55	85	80	60	50	50	40	75	75	85	100	80	80	45	50	60	60	60	80	90
à 2000m																												

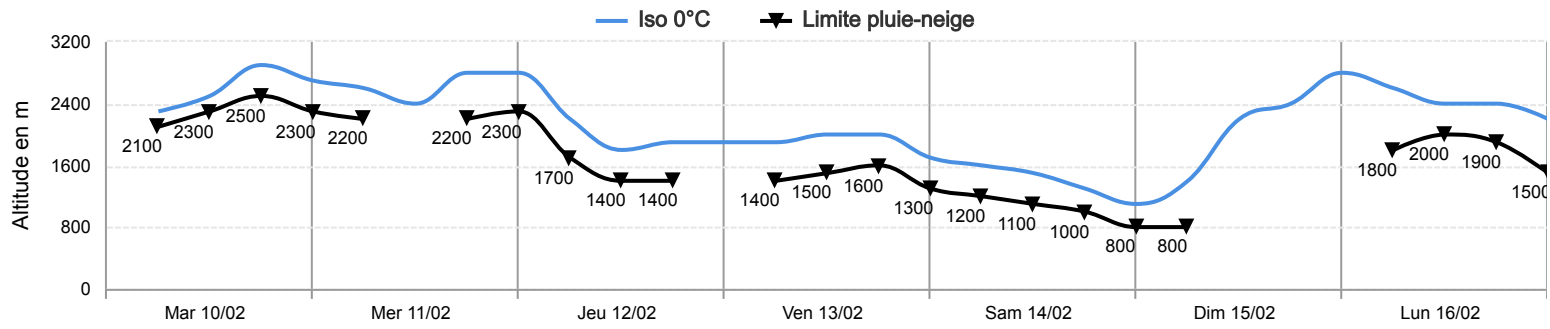

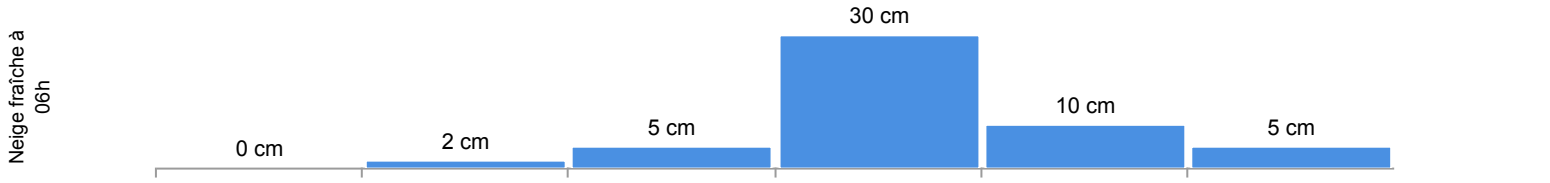

Risque d'avalanche	mar. 10/02	mer. 11/02	jeu. 12/02	ven. 13/02	sam. 14/02	dim. 15/02	lun. 16/02
	4	4	3	2	3	4	4

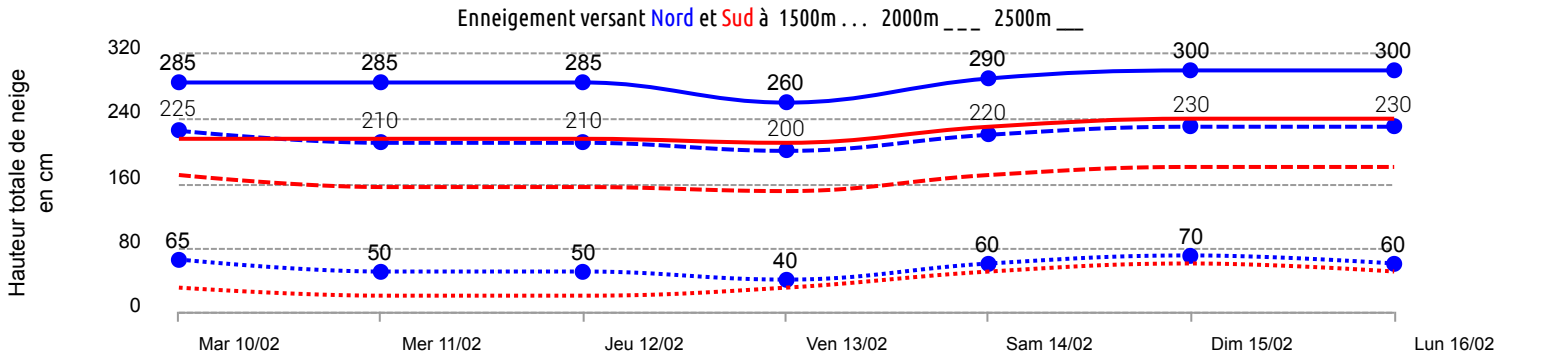

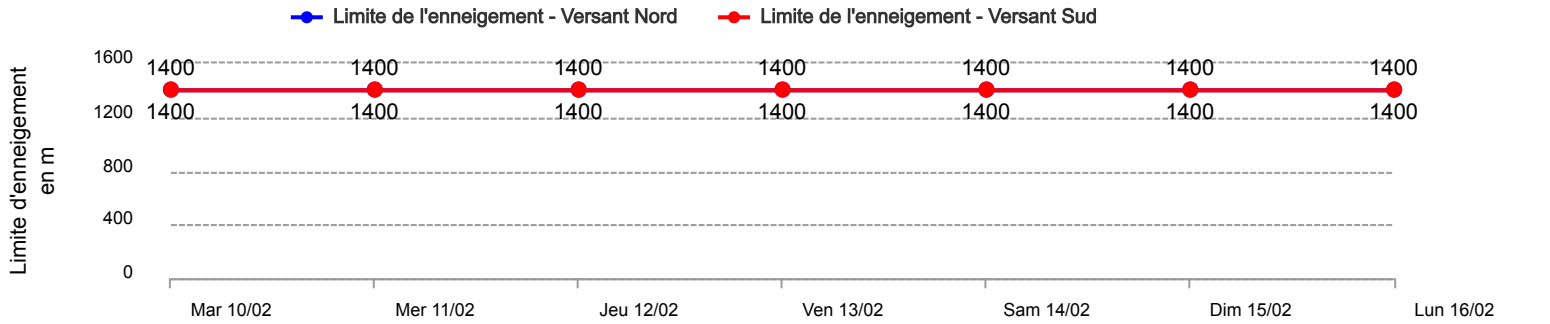

Pour consulter la vigilance en cours, veuillez vous rendre sur le site https://vigilance.meteofrance.fr/fr

Météo-France - 73 avenue de Paris, 94165 Saint-Mandé cedex - Contact : contact@meteo.fr

Rédigé par Météo-France avec la contribution des observateurs du réseau nivo-météorologiques. Partenariat : ANMSM (Maires de Stations de Montagne), DSF (Domaines Skiables de France), ADSP (Directeurs de Pistes et de la Sécurité des Stations de Sports d'Hiver) et autres acteurs de la montagne.

Bulletin neige & avalanches par téléphone au

0 892 68 10 20 Service 0,35 € / min + prix appel