GOBIERNO DE ESPAÑA
VICEPRESIDENCIA TERCERA DEL GOBIERNO
MINISTERIO PARA LA TRANSICIÓN ECOLÓGICA Y EL RETO DEMOGRÁFICO

Boletín de información nivológica y de peligro de aludes

Pirineo Catalán

aemet Agencia Estatal de Meteorología

martes, 17 de febrero de 2026

Pronóstico hasta las 24 horas del miércoles, día 18 de febrero

(Válido fuera de pistas de esquí balizadas y abiertas)

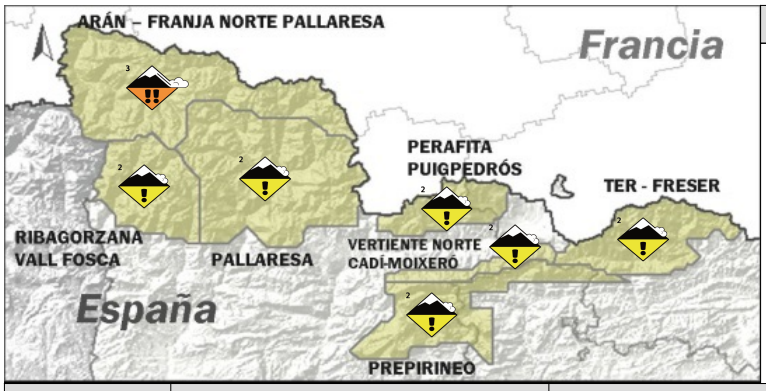

Problemas de aludes

Placas de viento

Nieve húmeda

Macizo	Peligro	Problemas de aludes, cota, orientación, tamaño	Innivación observada (m)
Arán - Franja norte Pallaresa	3 / 3 / 2 / 2100 **Notable**	**Placas de viento**: 2100, N O E S, 3 **Nieve húmeda**: 2500, N O E S, 2	2026-02-17 N S Cotas bajas
Ribagorzana - Vall Fosca	2 / 2 **Limitado**	**Placas de viento**: 2100, N O E S, 2 **Nieve húmeda**: 2500, N O E S, 2	2026-02-17 N S Cotas bajas
Pallaresa	2 / 2 **Limitado**	**Placas de viento**: 2100, N O E S, 2 **Nieve húmeda**: 2500, N O E S, 2	2026-02-17 N S Cotas bajas

AEMET. Se autoriza la reproducción de su contenido citando la fuente.

Boletín de información nivológica y de peligro de aludes

Pirineo Catalán

Perafita - Puigpedrós	2 **Limitado**	**Placas de viento** 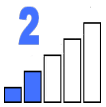 **Nieve húmeda** 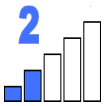	2026-02-17 Cotas bajas
Ter - Freser	2 **Limitado**	**Placas de viento** 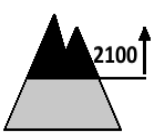 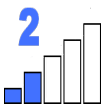 **Nieve húmeda** 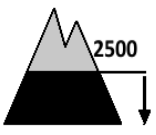 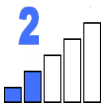	2026-02-17 Cotas bajas
Vertiente norte Cadí - Moixeró	2 **Limitado**	**Placas de viento** 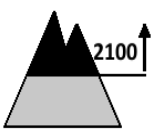 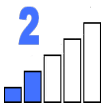 **Nieve húmeda** 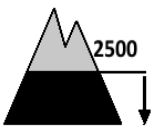 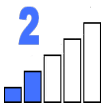	2026-02-17 Cotas bajas
Prepirineo	2 **Limitado**	**Placas de viento** 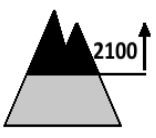 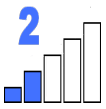 **Nieve húmeda** 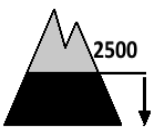 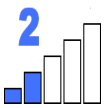	2026-02-17 Cotas bajas

Estado del manto y observaciones recientes

La nieve superficial se humidificó ayer hasta cotas altas a causa de las lluvias en la mayoría de zonas. Por encima de unos 2200 metros, la precipitación fue enteramente en forma de nieve, húmeda primero y luego más seca cuanta mayor altitud. Los mayores acumulados se midieron en el Arán-F.N.Pallaresa, con 10-20 mm, mientras que en el resto de zonas no se superaron los 10 mm.

AEMET. Se autoriza la reproducción de su contenido citando la fuente.

Las cotas medias y bajas constan de un perfil bastante humedecido, en algunos sectores hasta la base, y con costra de rehielo en superficie. En cotas altas también se ha formado costra en muchos puntos, confiriéndole una importante estabilización. Más arriba, en la alta montaña, la nieve permanece más seca y muy venteada, con una distribución muy irregular a causa de los intensos vientos. Además, las antiguas capas débiles persistentes todavía pueden estar presentes en niveles subyacentes en las umbrías.

El manto es continuo desde cotas bajas, con espesores que en la mayor parte de la cordillera se encuentran en máximos, muy por encima de lo que cabría esperar a estas alturas de la temporada, superándose los 150 a 200 cm por encima de 2.200 metros en numerosas áreas.

Evolución del manto y peligro de aludes para el miércoles, día 18

Problema de placas de viento en cotas altas. Problema de nieve húmeda.

En cotas altas, se han formado placas de viento en todas las orientaciones aunque con predominio de los sectores este y sur. Hasta unos 2500 metros, podremos encontrar costra superficial lo suficientemente gruesa como para desactivarlas completamente. En zonas sin costra, las placas podrán permanecer frágiles y serán susceptibles de romper al paso de una sola persona desencadenando aludes de tamaño mediano, localmente grande. Estas placas son más frecuentes en el Arán-F.N.Pallaresa, mientras que en el resto se distribuyen de manera más aislada.

Se prevé que las cotas medias y bajas amanezcan con costra de rehielo superficial que se vaya ablandando debido a la insolación a medida que avance el día. A consecuencia, serán probables los aludes de nieve húmeda de tamaño pequeño o mediano en laderas con la suficiente inclinación, especialmente en solanas. Asimismo, no se descarta la ocurrencia de algún deslizamiento basal.

Predicción meteorológica para el miércoles, día 18

Intervalos nubosos a primeras horas, aumentando a muy nuboso o cubierto al final del día. Precipitaciones débiles o localmente moderadas, al final del día, principalmente en los macizos occidentales. Cota de nieve bajando de unos 1800 a 1400 metros aproximadamente. Temperaturas mínimas sin cambios o en ligero descenso. Máximas en ligero o moderado ascenso. Heladas débiles, moderadas en cotas altas, donde podrán ser localmente fuertes. Viento moderado de componente oeste, aumentando a fuerte, con rachas muy fuertes en cotas altas y zonas expuestas.

Datos en la atmósfera libre:

Altitud de la isoterma de 0 ºC: 2600 m
Altitud de la isoterma de -10 ºC: 4500 m

Viento a 1500 m: SW 15 km/h
Viento a 3000 m: SW 70 km/h

AEMET. Se autoriza la reproducción de su contenido citando la fuente.

Evolución para el jueves día 19

Nivel de peligro en ligero ascenso, con el aumento de los problemas de nieve seca.

Escala europea de peligro de aludes

Débil | Limitado | Notable | Fuerte | Muy Fuerte

Problemas de aludes

Nieve reciente | Placas de viento | Capas débiles persistentes | Nieve húmeda | Deslizamientos basales | Sin problema evidente

Nota1: Se recuerda que, siempre que haya nieve, la ausencia total de peligro no existe. Hay que tener presente que en circunstancias desfavorables, con aludes de tamaño 1 (alud pequeño o colada) y tamaño 2 (alud mediano), se pueden sufrir severos daños personales.

Nota2: Los BPA se elaboran en base a información meteorológica así como al estado del manto nivoso a través de sondeos puntuales. Se advierte a los usuarios de la variabilidad de esta información al extrapolarla a zonas extensas de montaña. Por ello, AEMET no se hace responsable de su uso para la toma de decisiones que conciernen a la seguridad personal, ni de los riesgos físicos o materiales de ellas derivadas.

AEMET. Se autoriza la reproducción de su contenido citando la fuente.