GOBIERNO DE ESPAÑA
VICEPRESIDENCIA TERCERA DEL GOBIERNO
MINISTERIO PARA LA TRANSICIÓN ECOLÓGICA Y EL RETO DEMOGRÁFICO

Boletín de información nivológica y de peligro de aludes

Pirineo Navarro y Aragonés

aemet Agencia Estatal de Meteorología

martes, 17 de febrero de 2026

Pronóstico hasta las 24 horas del miércoles, día 18 de febrero

(Válido fuera de pistas de esquí balizadas y abiertas)

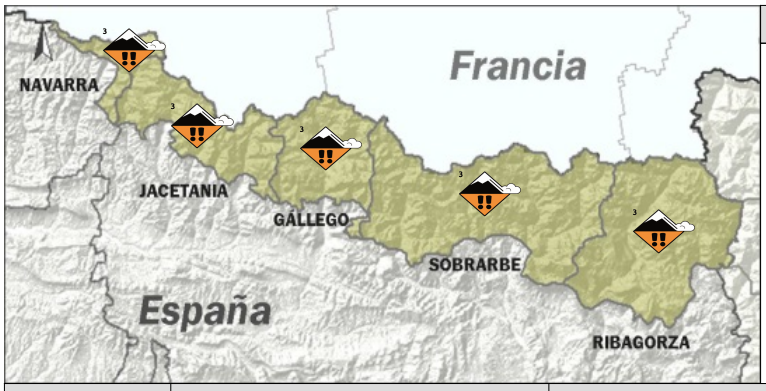

Problemas de aludes

Placas de viento

Nieve húmeda

Macizo	Peligro	Problemas de aludes, cota, orientación, tamaño	Innivación observada (m)
Navarra	3 / 3 2100 / 2 Notable	Placas de viento: 2100; N O E S; 3 Nieve húmeda: 2500; N O E S; 2	2026-02-17 N S Cotas bajas
Jacetania	3 / 3 2100 / 2 Notable	Placas de viento: 2100; N O E S; 3 Nieve húmeda: 2500; N O E S; 2	2026-02-17 N S Cotas bajas
Gállego	3 / 3 2100 / 2 Notable	Placas de viento: 2100; N O E S; 3 Nieve húmeda: 2500; N O E S; 2	2026-02-17 N S Cotas bajas

AEMET. Se autoriza la reproducción de su contenido citando la fuente.

Boletín de información nivológica y de peligro de aludes

Pirineo Navarro y Aragonés

Sobrarbe	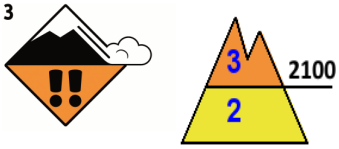 **Notable**	**Placas de viento** 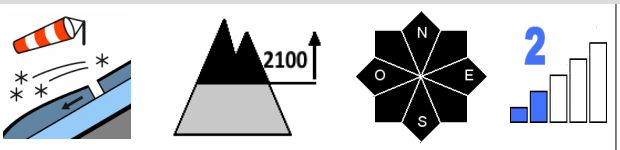 **Nieve húmeda** 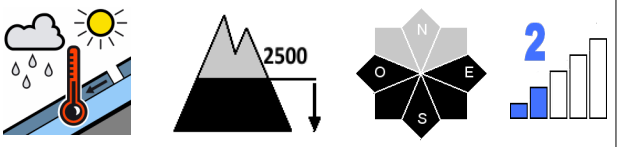	2026-02-17
Ribagorza	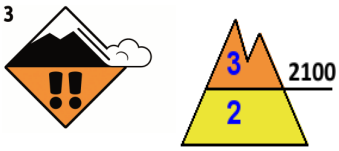 **Notable**	**Placas de viento** 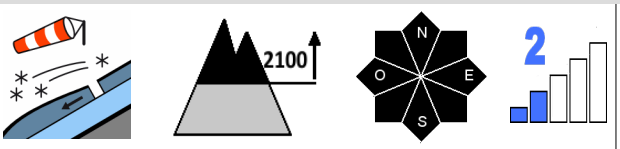 **Nieve húmeda** 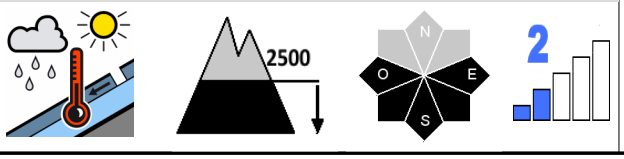	2026-02-17

Estado del manto y observaciones recientes

La nieve superficial se humidificó ayer hasta cotas altas a causa de las lluvias. Por encima de unos 2200 metros, la precipitación fue enteramente en forma de nieve, húmeda primero y luego más seca cuanta mayor altitud. Los mayores acumulados se midieron del Valle de Tena hacia el oeste, con 20-40 mm, mientras que hacia el este estos fueron inferiores a 15 mm.

Las cotas medias y bajas constan de un perfil húmedo hasta la base con costra de rehielo en superficie. En cotas altas también se ha observado costra esta mañana en muchos puntos, al menos hasta los 2500 metros, confiriéndole una importante estabilización. Más arriba, en la alta montaña, la nieve permanece más seca y muy venteada, con una distribución muy irregular a causa de los intensos vientos. Además, las antiguas capas débiles persistentes todavía pueden estar presentes en niveles subyacentes en las umbrías.

Las mermas de espesor se han notado más en las cotas bajas de los macizos occidentales. Aun así, el manto sigue siendo continuo desde fondos de valle y presenta espesores muy por encima del promedio habitual a estas alturas de la temporada. En torno a 2.100 metros se superan fácilmente los 150-200 cm, aún más en ventisqueros, hoyas y otras zonas propensas a la acumulación.

Evolución del manto y peligro de aludes para el miércoles, día 18

Problema de placas de viento en cotas altas. Problema de nieve húmeda.

En cotas altas, se han formado numerosas placas de viento en todas las orientaciones aunque con predominio de los sectores este y sur. Hasta unos 2500 metros, podremos encontrar costra superficial lo suficientemente gruesa como para desactivarlas completamente. En zonas sin costra, las placas podrán permanecer frágiles y serán susceptibles de romper al paso de una sola persona desencadenando aludes de tamaño mediano, localmente grande.

AEMET. Se autoriza la reproducción de su contenido citando la fuente.

En el Sobrarbe y la Ribagorza, el peligro será algo inferior en los macizos más alejados de la divisoria fronteriza.

Se prevé que las cotas medias y bajas amanezcan con costra de rehielo superficial que se vaya ablandando debido a la insolación a medida que avance el día. A consecuencia, serán probables los aludes de nieve húmeda de tamaño pequeño o mediano en laderas con la suficiente inclinación, especialmente en solanas. Asimismo, no se descarta la ocurrencia de algún deslizamiento basal.

Predicción meteorológica para el miércoles, día 18

Pirineo navarro:
Intervalos nubosos durante la mañana, aumentando a muy nuboso o cubierto por la tarde. Precipitaciones débiles o moderadas durante la segunda mitad del día, que podrán ser en forma de chubascos. Cota de nieve bajando de 1800 a 1100 metros aproximadamente. No se descarta alguna tormenta ocasional al final del día. Temperaturas mínimas sin cambios o en ligero descenso, pudiendo darse al final del día. Máximas en ligero o moderado ascenso. Heladas débiles, moderadas en cotas altas. Viento moderado de componente sur, tendiendo a fuerte del suroeste, con rachas muy fuertes en cotas altas y zonas expuestas, donde se podrán superar los 100 km/h en algunos puntos, y girando a noroeste al final del día.

Pirineo aragonés:
Intervalos nubosos durante la mañana, aumentando a muy nuboso o cubierto por la tarde. Precipitaciones débiles o localmente moderadas, durante la segunda mitad del día, que podrán ser en forma de chubascos. Cota de nieve bajando de 1800 a 1200 metros aproximadamente. No se descarta alguna tormenta ocasional al final del día, en la Jacetania y zonas próximas. Temperaturas mínimas sin cambios o en ligero descenso. Máximas en ligero o moderado ascenso. Heladas débiles, moderadas en cotas altas, donde podrán ser localmente fuertes. Viento moderado de componente oeste, aumentando a fuerte, con rachas muy fuertes en cotas altas y zonas expuestas, donde se podrán superar los 100 km/h en algunos puntos.

Datos en la atmósfera libre:

Altitud de la isoterma de 0 ºC: 2400 m
Altitud de la isoterma de -10 ºC: 4500 m

Viento a 1500 m: S 25 km/h
Viento a 3000 m: SW 80 km/h

Evolución para el jueves día 19

Nivel de peligro en ligero ascenso, con el aumento de los problemas de nieve seca.

(Información elaborada a partir de los datos recibidos de los refugios de Linza, Lizara, Panticosa, Bachimaña, Góriz, Pineta, Estós, Angel Orús, Cap de Llauset y Belagua, de las estaciones de esquí de Formigal y Panticosa (lagos) y de la estación de esquí de fondo de Llanos del Hospital)

Escala europea de peligro de aludes

Débil | Limitado | Notable | Fuerte | Muy Fuerte

Problemas de aludes

Nieve reciente | Placas de viento | Capas débiles persistentes | Nieve húmeda | Deslizamientos basales | Sin problema evidente

AEMET. Se autoriza la reproducción de su contenido citando la fuente.

Nota1: Se recuerda que, siempre que haya nieve, la ausencia total de peligro no existe. Hay que tener presente que en circunstancias desfavorables, con aludes de tamaño 1 (alud pequeño o colada) y tamaño 2 (alud mediano), se pueden sufrir severos daños personales.

Nota2: Los BPA se elaboran en base a información meteorológica así como al estado del manto nivoso a través de sondeos puntuales. Se advierte a los usuarios de la variabilidad de esta información al extrapolarla a zonas extensas de montaña. Por ello, AEMET no se hace responsable de su uso para la toma de decisiones que conciernen a la seguridad personal, ni de los riesgos físicos o materiales de ellas derivadas.

AEMET. Se autoriza la reproducción de su contenido citando la fuente.