Mittwoch 18.02.2026

Veröffentlicht am 17.02.2026 um 17:00

Vormittag

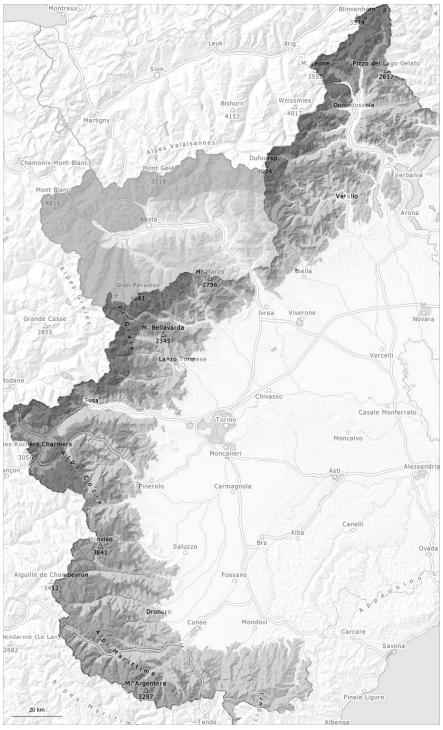

Nachmittag

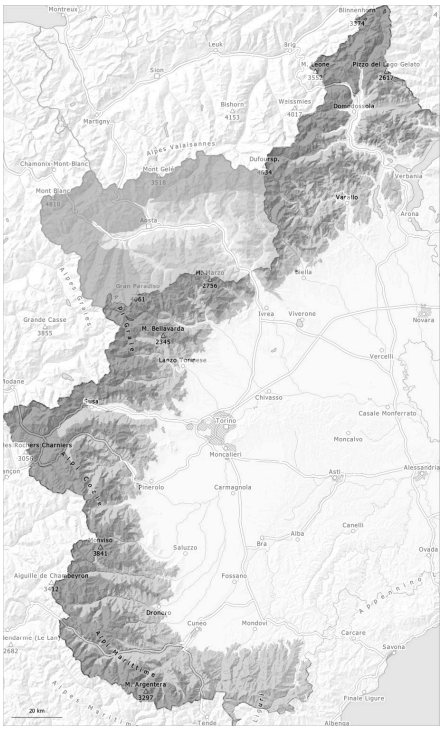

1	2	3	4	5
gering	mäßig	erheblich	groß	sehr groß

Gefahrenstufe 4 - Groß

AM:

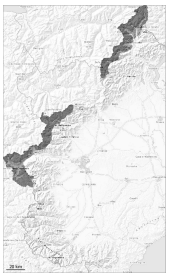

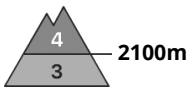

Tendenz: Lawinengefahr nimmt ab
am Donnerstag, den 19.02.2026

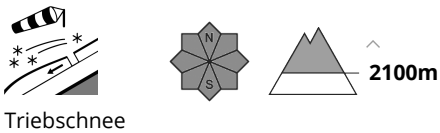

Triebschnee

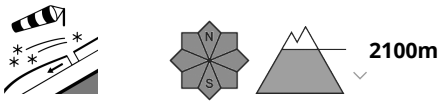

Triebschnee

PM:

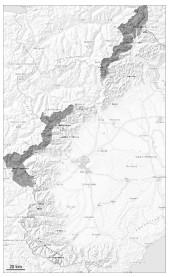

Tendenz: Lawinengefahr nimmt ab
am Donnerstag, den 19.02.2026

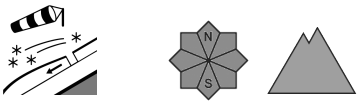

Triebschnee

Mit Neuschnee und Sturm gebietsweise noch gefährliche Lawinensituation.

Mit Schneefall und teils stürmischem Nordwestwind entstanden in den letzten drei Tagen frische Triebschneeansammlungen. Dies vor allem in den Föhngebieten und im Bereich der Waldgrenze und in Rinnen, Mulden und hinter Geländekanten.
Die störanfälligen Triebschneeansammlungen können schon von einzelnen Wintersportlern leicht ausgelöst werden.

Die Spitze der Lawinenaktivität wird in den Föhngebieten am Vormittag erreicht. An Triebschneehängen und aus noch nicht entladenen Einzugsgebieten sind mit der tageszeitlichen Erwärmung und der Sonneneinstrahlung große und vereinzelt sehr große trockene und feuchte Lawinen möglich.

Schneedecke

Gefahrenmuster gm.6: lockerer schnee und wind

Seit Montag fielen gebietsweise verbreitet 40 bis 80 cm Schnee, lokal auch mehr.
Der teilweise stürmische Wind hat viel Schnee verfrachtet.
V.a. in Gipfellagen liegen je nach Windeinfluss sehr unterschiedliche Schneehöhen.

In der Altschneedecke sind vor allem an steilen Nordwest-, Nord- und Osthängen Schwachschichten vorhanden. Vor allem kammfern,: Verschiedene Triebschneeschichten liegen stellenweise auf Oberflächenreif.

Gefahrenstufe 3 - Erheblich

AM:

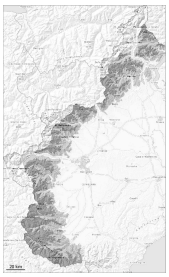

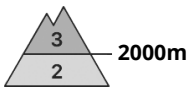

Tendenz: Lawinengefahr bleibt gleich
am Donnerstag, den 19.02.2026

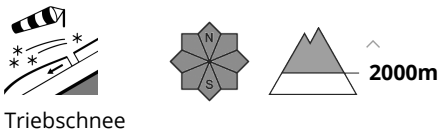

Triebschnee

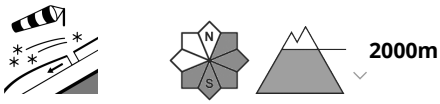

Triebschnee

PM:

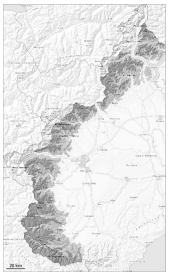

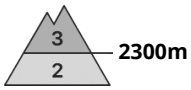

Tendenz: Lawinengefahr bleibt gleich
am Donnerstag, den 19.02.2026

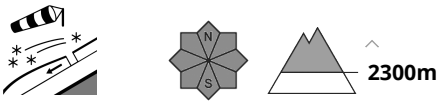

Triebschnee

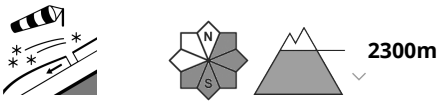

Triebschnee

Der Wind blies verbreitet stark bis stürmisch. Triebschnee ist die Hauptgefahr.

Der teilweise starke Wind hat Neu- und Altschnee intensiv verfrachtet. Mit starkem Nordwestwind entstehen bis am Morgen Triebschneeansammlungen. Diese liegen vor allem zwischen etwa 2100 und 2500 m.

Vor allem mittlere und hohe Lagen sowie in windgeschützten Lagen: Weiche Triebschneeansammlungen können im Bereich der Waldgrenze von einzelnen Wintersportlern ausgelöst werden.

Zudem sind die harten Triebschneeansammlungen der letzten Tage in Passlagen aller Expositionen und allgemein in der Höhe weiterhin auslösbar. Dies vor allem mit großer Belastung.

Mit der tageszeitlichen Erwärmung und der Sonneneinstrahlung sind kaum kleine und mittlere trockene und feuchte Lawinen möglich.

Schneedecke

Gefahrenmuster gm.6: lockerer schnee und wind

> Seit Montag fielen oberhalb von rund 1700 m 10 bis 20 cm Schnee, lokal auch weniger. Der starke Wind hat viel Schnee verfrachtet.
> V.a. in Gipfellagen liegen je nach Windeinfluss sehr unterschiedliche Schneehöhen.
>
> In der Altschneedecke sind vor allem an steilen Nordwest-, Nord- und Osthängen kaum Schwachschichten vorhanden.

Gefahrenstufe 2 - Mäßig

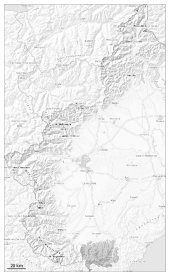

Tendenz: Lawinengefahr bleibt gleich
am Donnerstag, den 19.02.2026

Triebschnee

Der Wind blies verbreitet stark bis stürmisch. Triebschnee ist die Hauptgefahr.

Der teilweise stürmische Wind hat viel Schnee verfrachtet. Mit starkem Nordwestwind entstanden in den letzten Tagen frische Triebschneeansammlungen. Sie liegen vor allem zwischen etwa 1900 und 2300 m. Zudem sind die harten Triebschneeansammlungen der letzten Tage in Passlagen aller Expositionen und allgemein in der Höhe weiterhin auslösbar. Dies vor allem mit großer Belastung.

Vor allem mittlere Lagen sowie in windgeschützten Lagen: Die weichen Triebschneeansammlungen können vereinzelt von einzelnen Wintersportlern ausgelöst werden.

Schneedecke

Der starke Wind hat viel Schnee verfrachtet.
V.a. in Gipfellagen liegen je nach Windeinfluss sehr unterschiedliche Schneehöhen.

Vor allem in mittleren und hohen Lagen liegt für die Jahreszeit viel Schnee.