Mittwoch 18.02.2026

Veröffentlicht am 17.02.2026 um 17:00

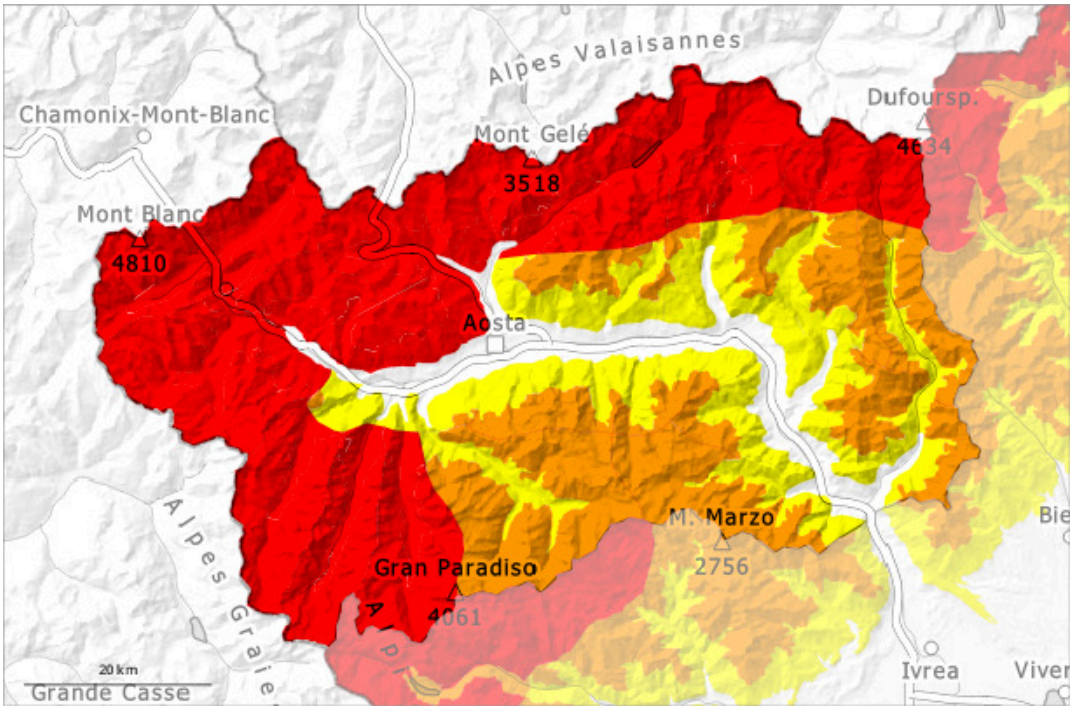

1	2	3	4	5
gering	mäßig	erheblich	groß	sehr groß

Gefahrenstufe 4 - Groß

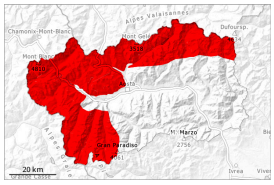

Tendenz: Lawinengefahr bleibt gleich
am Donnerstag, den 19.02.2026

Triebschnee

1800m

Neuschnee

Die Schneedecke bleibt allgemein instabil. Nachmittag: Leichter Rückgang der Lawinengefahr mit dem Abklingen der Schneefälle.

Bis am Mittag fällt etwas Schnee. Mit Schneefall und starkem Nordwestwind wachsen die Triebschneeansammlungen am Vormittag an.
Besonders an sehr steilen Hängen und an Triebschneehängen sind mittlere und große spontane trockene Lawinen möglich. Die Lawinen können stellenweise in tiefen Schichten ausgelöst werden und teils sehr groß werden.
Die Lawinen können in diesen Gebieten in den typischen Lawinenzügen weiterhin bis in Tallagen vorstoßen.

Für Touren und Variantenabfahrten abseits gesicherter Pisten sind die Verhältnisse heimtückisch. Fernauslösungen sind möglich. Einzelne Wintersportler können Lawinen auslösen, auch große. Vorsicht an steilen Hängen und in Rinnen, Mulden und hinter Geländekanten.

Schneedecke

Gefahrenmuster gm.6: lockerer schnee und wind | gm.1: bodennahe schwachschicht

Seit Sonntag fielen oberhalb von rund 1500 m verbreitet 50 bis 80 cm Schnee, lokal auch mehr. Am Mittwoch fallen oberhalb von rund 1300 m verbreitet 5 bis 15 cm Schnee. Bis Mittwoch bläst der Wind verbreitet verbreitet stark.
Der Neuschnee sowie die teils großen Triebschneeansammlungen sind teils noch störanfällig.
Die Schneedecke ist ungünstig geschichtet.
In Kamm- und Passlagen liegen je nach Windeinfluss sehr unterschiedliche Schneehöhen.
Im Tagesverlauf sind einige große Staublawinen abgegangen. In den letzten Tagen wurden mehrere Schneebrettlawinen ausgelöst.

Tendenz

Neu- und Triebschnee: Die Lawinengefahr bleibt bestehen.

Gefahrenstufe 3 - Erheblich

Tendenz: Lawinengefahr bleibt gleich
am Donnerstag, den 19.02.2026

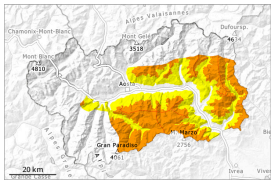

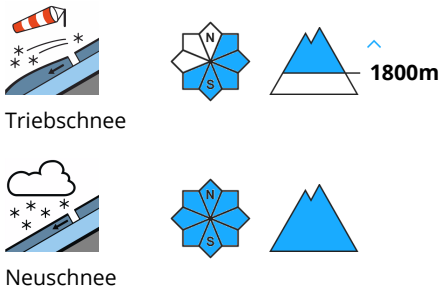

Die Schneedecke ist verbreitet instabil. Der Wind bläst zeitweise stark bis stürmisch. Triebschnee ist die Hauptgefahr.

Mit dem starken Nordwestwind nimmt die Größe der Gefahrenstellen am Vormittag zu.
Besonders an sehr steilen Hängen und an Triebschneehängen sind mittlere spontane Lawinen möglich. Die Lawinen können stellenweise im Altschnee ausgelöst werden und recht groß werden. Die Lawinen können in den typischen Lawinenzügen vereinzelt bis in mittlere Lagen vorstoßen.
Schwachschichten im Altschnee erfordern Vorsicht. Fernauslösungen sind möglich. Wummgeräusche und Risse beim Betreten der Schneedecke sind Alarmzeichen.
Einzelne Wintersportler können Lawinen auslösen. Vorsicht an sehr steilen Hängen und in Rinnen, Mulden und hinter Geländekanten.

Schneedecke

Gefahrenmuster gm.6: lockerer schnee und wind | gm.1: bodennahe schwachschicht

Seit Sonntag fielen oberhalb von rund 1600 m verbreitet 15 bis 40 cm Schnee. Am Mittwoch fallen oberhalb von rund 1300 m verbreitet 5 bis 10 cm Schnee. Bis Mittwoch bläst der Wind lokal stark bis stürmisch.
In Kamm- und Passlagen liegen je nach Windeinfluss sehr unterschiedliche Schneehöhen. Die Schneedecke ist ungünstig geschichtet.
In der Altschneedecke sind v.a. an West-, Nord- und Osthängen kantig aufgebaute Schwachschichten vorhanden.
Im Tagesverlauf sind mehrere mittlere bis große spontane trockene Lawinen abgegangen.

Tendenz

Neu- und Triebschnee: Die Lawinengefahr bleibt bestehen.