Mercoledì 18.02.2026

Pubblicato il 17.02.2026 alle ore 17:00

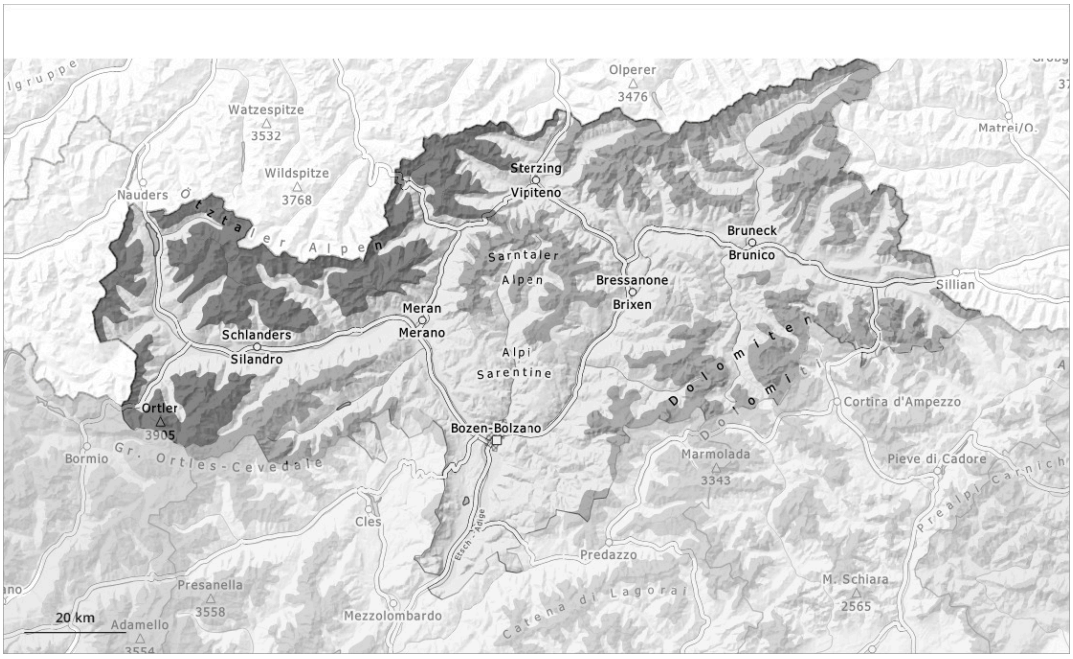

1	2	3	4	5
debole	moderato	marcato	forte	molto forte

Grado di pericolo 4 - Forte

Limite del bosco

Tendenza: pericolo valanghe stabile
per Giovedì il 19.02.2026

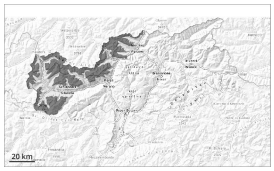

Strati deboli persistenti

Limite del bosco

Lastrone da vento

Limite del bosco

Gli strati deboli presenti nella neve vecchia possono distaccarsi molto facilmente. La neve ventata recente deve essere valutata con spirito critico.

Gli strati deboli molto pronunciati presenti nella neve vecchia possono distaccarsi facilmente in seguito al passaggio di un singolo appassionato di sport invernali. Ciò sui pendii esposti a ovest, nord ed est al di sopra del limite del bosco.
Le valanghe possono raggiungere grandi dimensioni a livello isolato. Attenzione soprattutto sui pendii esposti a nord ed est al di sopra dei 2200 m circa. Qui, tali punti pericolosi sono più diffusi.
I rumori di "whum" e la formazione di fessure quando si calpesta la coltre di neve così come nuove valanghe sono campanelli di allarme che rimandano a questo pericolo. Sono possibili distacchi a distanza.

Inoltre nelle conche, nei canaloni e dietro ai cambi di pendenza gli accumuli di neve ventata di più recente formazione degli ultimi giorni sono localmente instabili. Tali punti pericolosi si trovano sui pendii esposti a nord, est e sud est al di sopra del limite del bosco. Isolati punti pericolosi si trovano in prossimità del limite del bosco. I punti pericolosi e la probabilità di distacco aumenteranno con l'altitudine.

Nelle zone molto frequentate, la situazione valanghiva è leggermente meno critica.

Manto nevoso

Situazione tipo st.1: strato debole persistente basale | st.6: neve a debole coesione e vento

Da domenica sono caduti diffusamente da 20 a 40 cm di neve, localmente anche di più. Il vento è stato a tratti da forte a tempestoso.

Il manto nevoso è instabile. La neve fresca e la neve ventata si legheranno solo lentamente con la neve vecchia. In alcuni punti diversi strati di neve ventata poggiano su brina di superficie. Sui pendii esposti a ovest, nord ed est, nella parte basale del manto nevoso si trovano pronunciati strati fragili.

Tendenza

Gli strati deboli presenti nella neve vecchia rappresentano la principale fonte di pericolo.

Giovedì:
Cadranno sino a 10 cm di neve, localmente anche di più. Il vento sarà a tratti da forte a tempestoso. La neve fresca e la neve ventata in molti punti non si legheranno bene con la neve vecchia a tutte le esposizioni.

Grado di pericolo 3 - Marcato

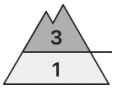

Limite del bosco

Tendenza: pericolo valanghe in aumento
per Giovedì il 19.02.2026

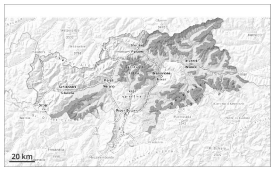

Strati deboli persistenti

Limite del bosco

Lastrone da vento

Limite del bosco

Gli strati deboli molto pronunciati presenti nella neve vecchia rappresentano la principale fonte di pericolo. Attenzione alla neve ventata recente.

Principalmente nelle zone poco frequentate, gli strati deboli presenti nella neve vecchia possono distaccarsi facilmente in seguito al passaggio di un singolo appassionato di sport invernali. Attenzione soprattutto sui pendii ripidi esposti a ovest, nord ed est al di sopra del limite del bosco. I punti pericolosi sono difficili da individuare. I rumori di "whum" e la formazione di fessure quando si calpesta la coltre di neve così come nuove valanghe sono campanelli di allarme che rimandano a questo pericolo. Sono possibili distacchi a distanza. Le valanghe sono per lo più di dimensioni medie.

Inoltre nelle conche, nei canaloni e dietro ai cambi di pendenza gli accumuli di neve ventata di più recente formazione degli ultimi giorni sono in parte ancora instabili. Tali punti pericolosi si trovano sui pendii esposti a nord, est e sud est al di sopra del limite del bosco. Isolati punti pericolosi si trovano in prossimità del limite del bosco.

È consigliata prudenza.

Manto nevoso

Situazione tipo st.1: strato debole persistente basale | st.8: brina di superficie sepolta

In alcune aree da domenica sono caduti da 10 a 20 cm di neve, localmente anche di più. Il vento è stato a tratti forte.

Il manto nevoso è instabile. Gli accumuli di neve ventata poggiano in parte su brina di superficie. Nella parte basale del manto di neve vecchia si trovano strati fragili a cristalli sfaccettati. Ciò soprattutto sui pendii esposti a ovest, nord ed est al di sopra del limite del bosco.

Tendenza

Gli strati deboli presenti nella neve vecchia rappresentano la principale fonte di pericolo.

Giovedì:
Cadranno da 10 a 30 cm di neve, localmente anche di più. Il vento sarà a tratti da forte a tempestoso. La neve fresca e la neve ventata in molti punti non si legheranno bene con la neve vecchia a tutte le esposizioni. Nelle aree più colpite dalle precipitazioni il pericolo di valanghe aumenterà.

Grado di pericolo 2 - Moderato

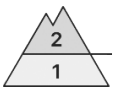

Limite del bosco

Tendenza: pericolo valanghe stabile
per Giovedì il 19.02.2026

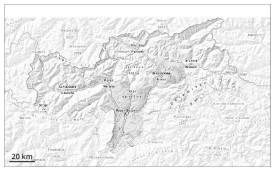

Strati deboli persistenti

Limite del bosco

Lastrone da vento

Limite del bosco

La neve ventata e la neve vecchia con strati deboli persistenti richiedono attenzione.

Le valanghe possono distaccarsi in seguito al passaggio di un singolo appassionato di sport invernali. Ciò specialmente sui pendii ombreggiati ripidi nelle zone in prossimità delle creste, nelle conche e nei canaloni al di sopra del limite del bosco.
Con il vento forte proveniente da nord, si sono formati nuovi accumuli di neve ventata. Questi ultimi sono in parte instabili. Le valanghe sono in parte di dimensioni medie.

Le escursioni richiedono attenzione e prudenza. È presente poca neve rispetto alla media stagionale.

Manto nevoso

Situazione tipo st.6: neve a debole coesione e vento

È caduta un po' di neve. All'interno del manto di neve vecchia si trovano strati fragili a cristalli sfaccettati. Gli accumuli di neve ventata nuovi e meno recenti poggiano su una sfavorevole superficie del manto di neve vecchia in quota.

Alle quote di bassa e media montagna: Il manto nevoso è umido, con una crosta da rigelo a malapena portante in superficie.

Tendenza

Moderato pericolo di valanghe.