ICGC Institut Cartogràfic i Geològic de Catalunya

Servei Meteorològic de Catalunya meteo.cat

Boletín de peligro de aludes para el Pirineo de Catalunya
Del 17/02/2026 al 18/02/2026

(Válido fuera pistas de esquí y zonas no controladas)

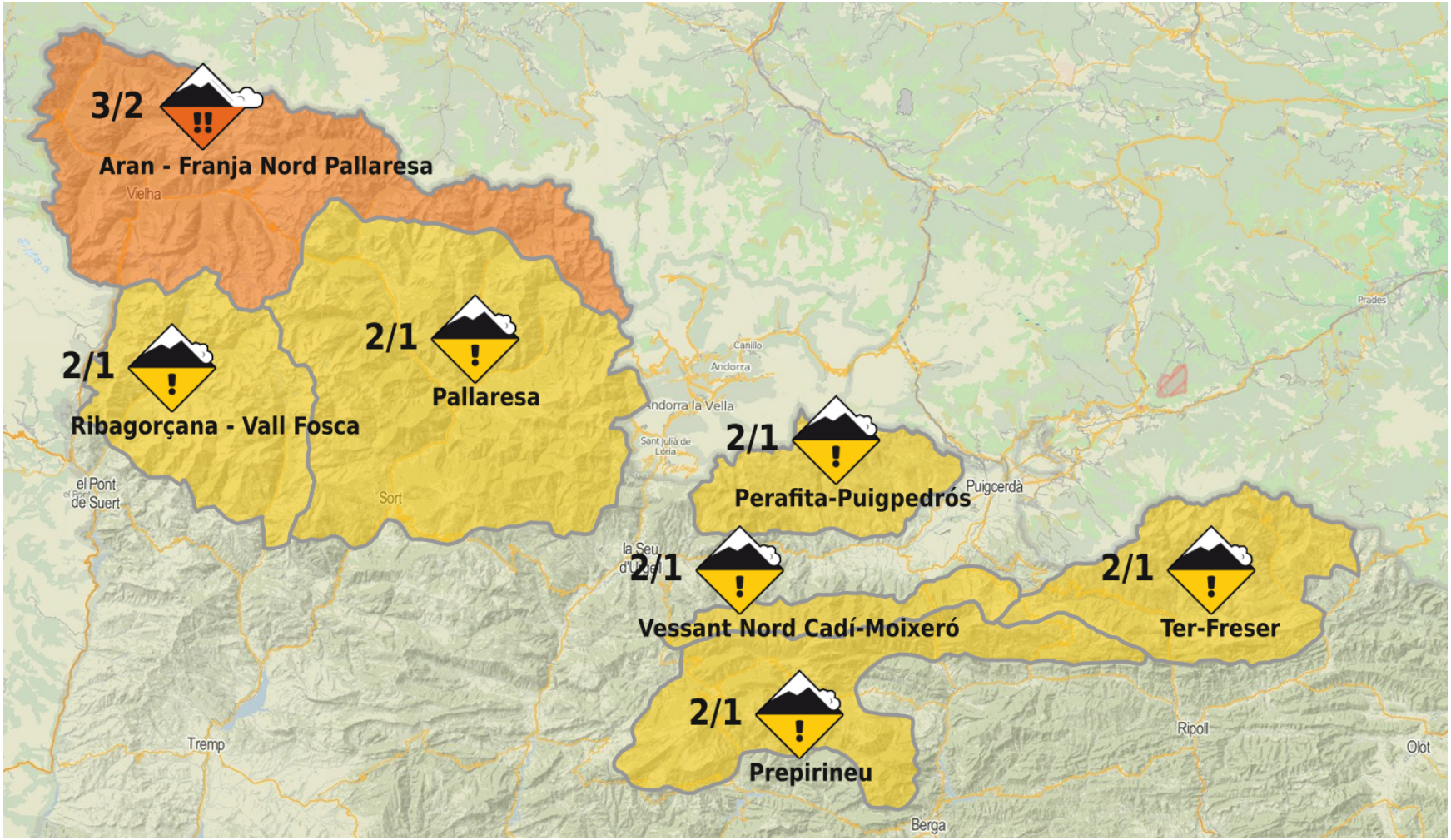

5 MUY FUERTE	4 FUERTE	3 NOTABLE	2 LIMITADO	1 DÉBIL

ICGC Institut Cartogràfic i Geològic de Catalunya

meteo.cat Servei Meteorològic de Catalunya

Boletín de peligro de aludes Aran - Franja Nord Pallaresa Del 17/02/2026 al 18/02/2026

(Válido fuera pistas de esquí y zonas no controladas)

NOTABLE (3) por encima de 2.200 m. LIMITADO (2), por debajo.

Situación primaria

Nieve venteada

Distribución

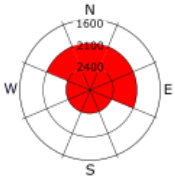

Tamaño

Origen

Tendencia

Situación secundaria

Nieve húmeda

Distribución

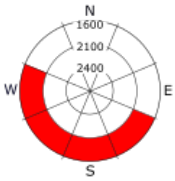

Tamaño

Origen

Tendencia

Estado del manto nivoso

Se ha registrado actividad de aludes naturales de nieve húmeda y placa húmeda. La última nevada y el viento continuado han formado nuevas placas de viento por encima del límite de bosque. Estas placas, aunque pueden ser probables en cualquier orientación de cota alta, serán más frecuentes en umbrías y podrán romper muy fácilmente al paso de una persona y generar aludes de hasta tamaño 2, medio. Aunque con probabilidad menor, en caso de que involucren capas internas, los aludes podrían alcanzar tamaño 3, grande.

En las horas centrales del día, con la insolación y aumento de temperatura, son posibles purgas y aludes pequeños de nieve húmeda, localmente de hasta tamaño 2, medio, en vertientes de fuerte pendiente y orientaciones S sobre todo.

Aún se mantiene también la probabilidad de deslizamientos basales en cualquier hora del día.

Distribución del manto nivoso

Hay nieve en el suelo a 1.400 m en Norte. El manto es esquiable por encima de unos 1.500 m en umbrías. Los espesores a unos 2.200 m son superiores a los normales y rondan los 120-140 cm en el norte de Arán y los 160-200 cm en la Franja Nort Pallaresa y en el sur de Aran.

Tendencia para las próximas 48-72h

Posibilidad de formación de nuevas placas con previsión de viento y nevadas para el jueves. Peligro EN AUMENTO.

El próximo boletín será emitido el día 2026-02-18

5 MUY FUERTE	4 FUERTE	3 NOTABLE	2 LIMITADO	1 DÉBIL

EAWS EUROPEAN AVALANCHE WARNING SERVICES

ICGC Institut Cartogràfic i Geològic de Catalunya

Servei Meteorològic de Catalunya meteo.cat

Boletín de peligro de aludes Ribagorçana - Vall Fosca Del 17/02/2026 al 18/02/2026

(Válido fuera pistas de esquí y zonas no controladas)

LIMITADO (2), por encima de 2.300 m
DÉBIL (1), por debajo

Situación primaria

Nieve venteada

Distribución

Tamaño

Origen

Tendencia

Estado del manto nivoso

El manto se encuentra bastante endurecido, formado mayoritariamente por grano fino y costras. Con las lluvias de ayer hasta los 2.400 m y la nevada húmeda a altitudes superiores, el manto se humedeció y reheló posteriormente, presentando una costra superficial. Podemos encontrar placas de viento locales, predominantemente en orientaciones E y N, de cota alta, bajo collados y cordales. Estas placas son por lo general de poco espesor dado que el fuerte viento barrió mucho la nieve, pero localmente pueden mostrarse todavía reactivas y romper al paso de una persona generando aludes que por lo general serían de tamaño pequeño, o medio en sectores de mayor sobreacumulación o que impliquen nieve vieja.
No se descarta que en las horas centrales del día haya caída de bolas o purgas de nieve húmeda en las vertientes más inclinadas orientadas a S.

Distribución del manto nivoso

Hay nieve en el suelo a 1.500 m. El manto es esquiable por encima de unos 1500-1600 m. Los grosores alcanzan los 130-160 cm. Estos valores son muy superiores a los normales en la época.

Tendencia para las próximas 48-72h

Posibilidad de formación de nuevas placas con previsión de viento y nevadas para el jueves. Peligro EN LEVE AUMENTO.

El próximo boletín será emitido el día 2026-02-18

5 MUY FUERTE	4 FUERTE	3 NOTABLE	2 LIMITADO	1 DÉBIL

EAWS EUROPEAN AVALANCHE WARNING SERVICES

ICGC Institut Cartogràfic i Geològic de Catalunya

Servei Meteorològic de Catalunya

Boletín de peligro de aludes Pallaresa
Del 17/02/2026 al 18/02/2026

(Válido fuera pistas de esquí y zonas no controladas)

LIMITADO (2), por encima de 2.300 m
DÉBIL (1), por debajo

Situación primaria

Nieve venteada

Distribución

Tamaño

Origen

Tendencia

Estado del manto nivoso

El manto se encuentra bastante endurecido, formado mayoritariamente por grano fino y costras. Con las lluvias de ayer hasta los 2.400 m y la nevada húmeda a altitudes superiores, el manto se humedeció y reheló posteriormente, presentando una costra superficial. Podemos encontrar placas de viento locales, predominantemente en orientaciones E y N, de cota alta, bajo collados y cordales. Estas placas son por lo general de poco espesor dado que el fuerte viento barrió mucho la nieve, pero localmente pueden mostrarse todavía reactivas y romper al paso de una persona generando aludes que por lo general serían de tamaño pequeño, o medio en sectores de mayor sobreacumulación o que impliquen nieve vieja.
No se descarta que en las horas centrales del día haya caída de bolas o purgas de nieve húmeda en las vertientes más inclinadas orientadas a S.

Distribución del manto nivoso

Hay nieve en el suelo a 1.500 m. El manto es esquiable por encima de unos 1500-1600 m. Los grosores alcanzan los 130-160 cm. Estos valores son muy superiores a los normales en la época.

Tendencia para las próximas 48-72h

Posibilidad de formación de nuevas placas con previsión de viento y nevadas para el jueves. Peligro EN LEVE AUMENTO.

El próximo boletín será emitido el día 2026-02-18

5 MUY FUERTE	4 FUERTE	3 NOTABLE	2 LIMITADO	1 DÉBIL

EAWS EUROPEAN AVALANCHE WARNING SERVICES

ICGC Institut Cartogràfic i Geològic de Catalunya

Servei Meteorològic de Catalunya

Boletín de peligro de aludes Perafita-Puigpedrós Del 17/02/2026 al 18/02/2026

(Válido fuera pistas de esquí y zonas no controladas)

LIMITADO (2), por encima de 2.300 m
DÉBIL (1), por debajo

Situación primaria

Nieve venteada

Distribución

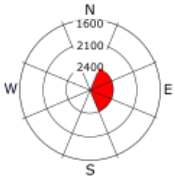

Tamaño

Origen

Tendencia

Estado del manto nivoso

El manto se humedeció ayer hasta unos 2.400 m por las débiles lluvias o nieve húmeda. Superficialmente, encontramos un manto encostrado por el rehielo nocturno con también numerosas costras internas, o bien endurecido por efecto del viento, que sopló intensamente sobre todo a partir de ayer lunes tarde. Podemos encontrar placas de viento locales, predominantemente en orientaciones E, SE y NE de cota alta, bajo collados y cordales o, puntualmente, a niveles inferiores más resguardados. Estas placas son por lo general de poco espesor y localmente pueden mostrarse todavía reactivas y romper al paso de una persona generando aludes que por lo general serían de pequeño tamaño, o medio en sectores de mayor sobreacumulación o que impliquen nieve vieja, que en este caso tendrían capacidad para enterrar a una persona.

Distribución del manto nivoso

Hay nieve en el suelo por encima de 1.400-1500 m. Sin embargo, el manto es esquiable por encima de 1.500-1.600 m. Los grosores alcanzan los 130-150 cm a 2.200 m. Son grosores muy por encima de los habituales por la época.

Tendencia para las próximas 48-72h

Posibilidad de nuevas y pequeñas placas con el viento y nevadas del jueves. Peligro ESTACIONARIO o EN LEVE AUMENTO.

El próximo boletín será emitido el día 2026-02-18

5 MUY FUERTE	4 FUERTE	3 NOTABLE	2 LIMITADO	1 DÉBIL

EAWS EUROPEAN AVALANCHE WARNING SERVICES

ICGC Institut Cartogràfic i Geològic de Catalunya

meteo.cat Servei Meteorològic de Catalunya

Boletín de peligro de aludes
Vessant Nord Cadí-Moixeró
Del 17/02/2026 al 18/02/2026

(Válido fuera pistas de esquí y zonas no controladas)

LIMITADO (2), por encima de 2.300 m
DÉBIL (1), por debajo

Situación primaria

Nieve venteada

Distribución

Tamaño

Origen

Tendencia

Estado del manto nivoso
El manto presenta una costra superficial, no portante por debajo del nivel de bosque y portante por encima del bosque, donde aquí encontramos también placas de viento, más frecuentes en orientaciones N y E. Estas placas son por lo general de poco grosor y localmente pueden mostrarse todavía reactivas y romper al paso de una persona generando aludes que en general serían de tamaño pequeño o medio, sobre todo a la salida de las canales o en sectores de sobreacumulación o que impliquen nieve vieja. Hay que tener cuidado con el terreno trampa, donde un alud pequeño puede llegar a enterrarnos.

Distribución del manto nivoso
Hay nieve desde 1.300 m. en norte y desde 1.400 a 1500 m. en sur, esquiable por encima de unos 1.500 m. Los grosores están alrededor de 150-170 cm a 2.200 m. Estos valores son muy excedentarios para la época del año.

Tendencia para las próximas 48-72h
Posibilidad de nuevas y pequeñas placas con el viento y nevadas del jueves. Peligro ESTACIONARIO o EN LEVE AUMENTO.

El próximo boletín será emitido el día 2026-02-18

5 MUY FUERTE	4 FUERTE	3 NOTABLE	2 LIMITADO	1 DÉBIL

EAWS EUROPEAN AVALANCHE WARNING SERVICES

ICGC Institut Cartogràfic i Geològic de Catalunya

meteo.cat Servei Meteorològic de Catalunya

Boletín de peligro de aludes Prepirineu
Del 17/02/2026 al 18/02/2026

(Válido fuera pistas de esquí y zonas no controladas)

LIMITADO (2), por encima de 2.300 m
DÉBIL (1), por debajo

Situación primaria

Nieve venteada

Distribución

Tamaño

Origen

Tendencia

Estado del manto nivoso
El humedecimiento del manto y posterior encostramiento, y el fuerte viento, han dejado un manto muy endurecido superficialmente en gran parte del sector. Podemos encontrar placas de viento locales, predominantemente en orientaciones E y N de cota alta, bajo collados y cordales. Estas placas son por lo general de poco espesor y localmente pueden mostrarse todavía reactivas y romper al paso de una persona generando aludes que por lo general serían de pequeño tamaño, o medio en sectores de mayor sobreacumulación o que impliquen nieve vieja, que en este caso tendrían capacidad para enterrar a una persona.

Distribución del manto nivoso
Hay nieve desde 1400-1500 m. El manto es esquiable a partir de 1600 m. Los grosores están alrededor de 110-130 cm a unos 2.200 m y son superiores a los habituales.

Tendencia para las próximas 48-72h
Posibilidad de nuevas y pequeñas placas con el viento y nevadas del jueves. Peligro ESTACIONARIO o EN LEVE AUMENTO.

El próximo boletín será emitido el día 2026-02-18

5 MUY FUERTE	4 FUERTE	3 NOTABLE	2 LIMITADO	1 DÉBIL

EAWS EUROPEAN AVALANCHE WARNING SERVICES

ICGC Institut Cartogràfic i Geològic de Catalunya

meteo.cat Servei Meteorològic de Catalunya

Boletín de peligro de aludes Ter-Freser
Del 17/02/2026 al 18/02/2026

(Válido fuera pistas de esquí y zonas no controladas)

LIMITADO (2), por encima de 2.300 m
DÉBIL (1), por debajo

Situación primaria

Nieve venteada

Distribución

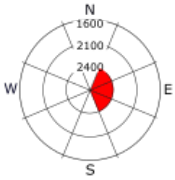

Tamaño

Origen

Tendencia

Estado del manto nivoso

El manto se humedeció ayer hasta unos 2.400 m por las débiles lluvias o nieve húmeda. Superficialmente, encontramos un manto encostrado por el rehielo nocturno o endurecido por efecto del viento, que sopló intensamente sobre todo a partir de ayer lunes tarde. Podemos encontrar placas de viento locales, predominantemente en orientaciones E, SE y NE de cota alta, bajo collados y cordales o, puntualmente, a media vertiente. Estas placas son por lo general de poco espesor y localmente pueden mostrarse todavía reactivas y romper al paso de una persona generando aludes que por lo general serían de pequeño tamaño, o medio en sectores de mayor sobreacumulación o que impliquen nieve vieja, que en este caso tendrían capacidad para enterrar a una persona.

Distribución del manto nivoso

El manto nivoso presenta grosores muy excedentarios para la época del año. En lugares no afectados por el viento, los espesores oscilan entre 100-140 cm a unos 2.000 m, siendo esquiable a partir de unos 1.500 m.

Tendencia para las próximas 48-72h

Posibilidad de nuevas y pequeñas placas con el viento y nevadas del jueves. Peligro ESTACIONARIO o EN LEVE AUMENTO.

El próximo boletín será emitido el día 2026-02-18

5 MUY FUERTE	4 FUERTE	3 NOTABLE	2 LIMITADO	1 DÉBIL

EAWS EUROPEAN AVALANCHE WARNING SERVICES