BUTLLETÍ DEL PERILL D'ALLAUS DEL PRINCIPAT D'ANDORRA

Servei meteorològic nacional
Principat d'Andorra

Elaborat el 17/02/2026 16:00
Propera actualització 18/02/2026 a les 16h

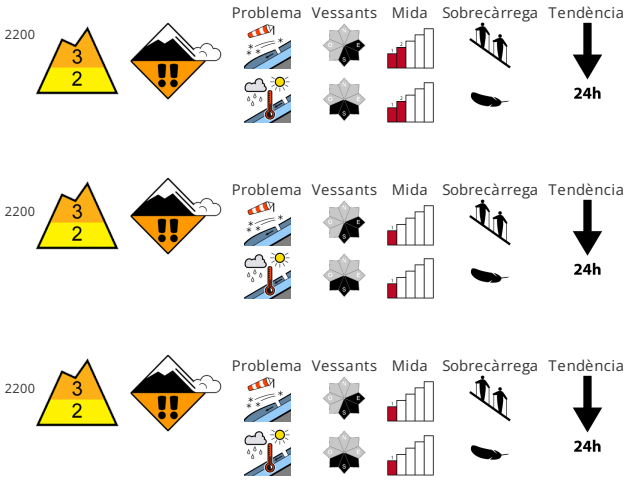

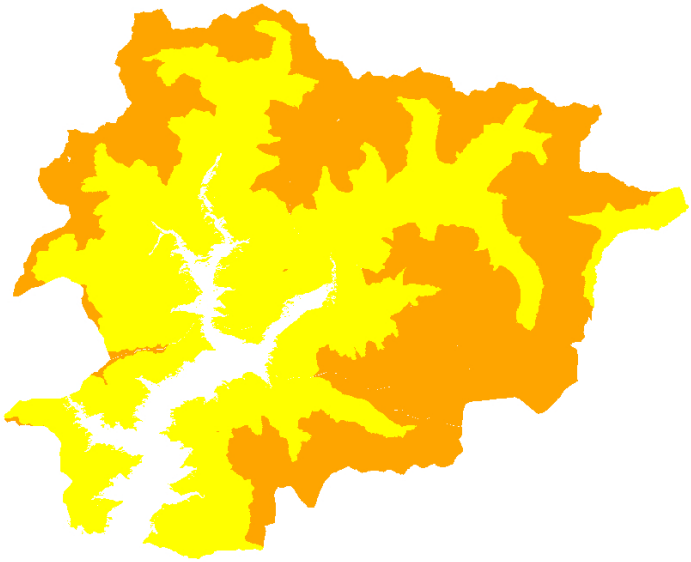

ESTABILITAT DEL MANTELL NIVAL

La neu recent i les plaques de vent han de ser avaluades amb cautela., especialment en vessants inclinats orientats a nord-est , sud i sud-est , i també en cubetes, canals i darrere de canvis abruptes de pendent. A conseqüencia de l'augment de la temperatura diürna i la radiació solar, augment progressiu del perill d'allaus de neu humida. Això es dona especialment en vessants assolellats inclinats i en cotes baixes i mitges. Es recomana una selecció acurada de la ruta i mantenir la distància entre els components.

QUALITAT DE LA NEU

Amb la neu recent i el vent les plaques de vent han augmentat de mida. Aquesta neu ha de ser avaluada amb cautela. El refredament nocturn serà força bo. A causa de la crosta de gel hi ha el perill de relliscar i caure. A cotes altes :. La neu recent esdevindrà progressivament més inestable vessants assolellats .

GRUIXOS DEL MANTELL NIVAL FORA DE PISTA

Zona nord		Gruix neu		
Mantell Nival		1500m	2000m	2500m
N	1300 m	50 cm	150 cm	200 cm
S	1400 m	30 cm	100 cm	150 cm

Zona centre		Gruix neu		
Mantell Nival		1500m	2000m	2500m
N	1300 m	30 cm	150 cm	200 cm
S	1400 m	10 cm	100 cm	150 cm

Zona sud		Gruix neu		
Mantell Nival		1500m	2000m	2500m
N	1300 m	30 cm	120 cm	150 cm
S	1400 m	10 cm	60 cm	100 cm

Govern d'Andorra

EAWS
EUROPEAN AVALANCHE WARNING SERVICES

Aquest butlletí ha estat elaborat seguint les normes i recomanacions de l'**European Avalanche Warning Services**, del qual el **Servei meteorològic Nacional** n'és membre

BUTLLETÍ DEL PERILL D'ALLAUS DEL PRINCIPAT D'ANDORRA

Servei meteorològic nacional
Principat d'Andorra

Informació detallada per espais naturals protegits

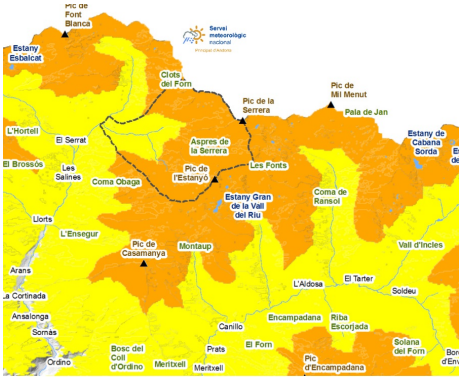

SORTENY

Les nevades del cap de setmana han estat conseqüents i han deixat gruixos de neu nova superiors als 50 cm, modelats pel vent. La pluja humidificarà el mantell fins a cotes mitges i la sobrecàrrega pot fer baixar allaus de manera natural Les activitats fora de les pistes controlades requereixen experiència i molta cura en l´elecció del territori.

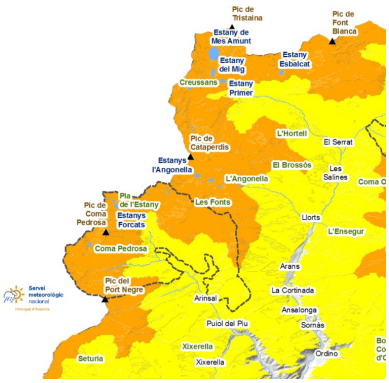

COMAPEDROSA

Les activitats a la muntanya són desaconsellables fins que la neu recent s´hagi estabilitzat . S´esperen nombroses allaus naturals.

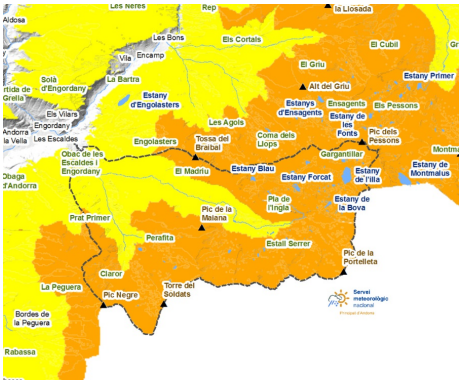

MADRIU-PERAFITA-CLAROR

A la part alta del Madriu també hi ha nevat, tot i que les nevades al sud del país han estat menys intenses, també esperem la formació de plaques de vent. La pluja humifdificarà la neu recent en les cotes baixes dificultant els accessos amb esquís.

Govern d'Andorra

EAWS
EUROPEAN AVALANCHE WARNING SERVICES

Aquest butlletí ha estat elaborat seguint les normes i recomanacions de l'**European Avalanche Warning Services**, del qual el **Servei meteorològic Nacional** n'és membre

BUTLLETÍ DEL PERILL D'ALLAUS DEL PRINCIPAT D'ANDORRA

Servei meteorològic nacional
Principat d'Andorra

Gruixos de neu nova dels darrers dies (de les últimes 24h mesurat a les 06:00h UTC)

	13/02/2026	14/02/2026	15/02/2026	16/02/2026
FEDA (Central)	0 cm	0 cm	0 cm	0 cm
Engolasters - FEDA	10 cm	3 cm	0 cm	0 cm
Bony de les Neres	14 cm	0 cm	0 cm	0 cm
Sorteny	36 cm	0 cm	2 cm	4 cm
Les Fonts d'Arinsal	18 cm	0 cm	0 cm	0 cm
Perafita	0 cm	12 cm	0 cm	0 cm
Tossa Espiolets	8 cm	3 cm	56 cm	0 cm
Grau Roig - FEDA	10 cm	0 cm	0 cm	0 cm
Fontverd	8 cm	13 cm	0 cm	0 cm
Ransol - FEDA	13 cm	2 cm	0 cm	0 cm
Setúria	8 cm	0 cm	0 cm	0 cm
Caborreu	8 cm	0 cm	4 cm	6 cm
Envalira Antenes	6 cm	8 cm	0 cm	0 cm