BUTLLETÍ DEL PERILL D'ALLAUS DEL PRINCIPAT D'ANDORRA

Servei meteorològic nacional
Principat d'Andorra

Préparé le 17/02/2026 16:00
Prochaine mise à jour le 18/02/2026 à 16h

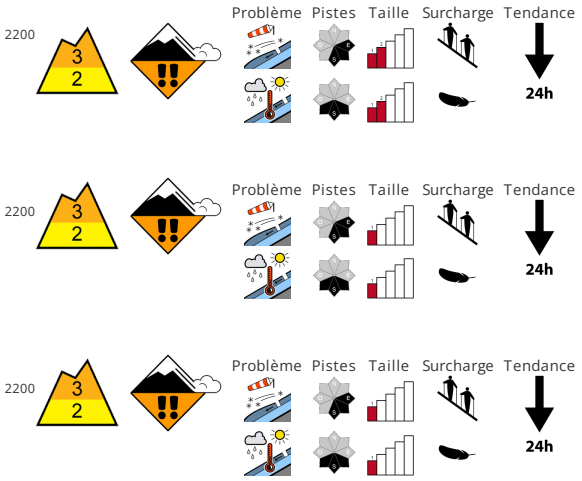

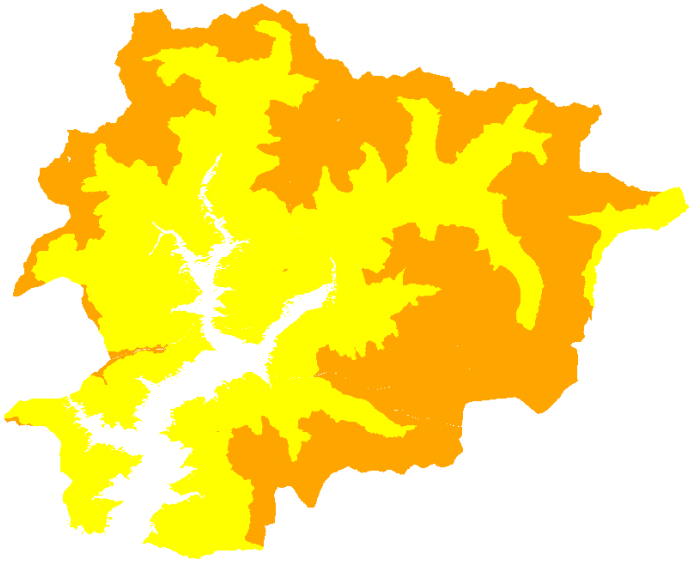

STABILITÉ DU MANTEAU NEIGEUX

La neige fraîche et la neige soufflée doivent être évaluées avec précaution. , surtout sur les pentes raides exposées au nord-est , au sud et au sud-est comme dans les combes, couloirs et derrière les ruptures de terrain. Augmentation progressive du danger d'avalanches humides avec le réchauffement diurne et le rayonnement solaire. Ceci surtout sur les pentes raides ensoleillées et à basse et moyenne altitude. Un choix prudent d'itinéraire et des distances de délestage sont recommandés..

QUALITÈ DE LA NEIGE

Les accumulations de neige soufflée se sont avec la neige fraîche et le vent. Elle doit être évaluée avec précaution. Le rayonnement nocturne est assez bon.. Sur la croûte glacée il existe un risque de chute.. À haute altitude (-):. La neige fraîche devient de plus en plus fragile ensoleillées.

EPAISSEUR DE NEIGE HORS PISTE

Zone nord		Epaisseur de neige		
Nival manteau		1500m	2000m	2500m
N	1300 m	50 cm	150 cm	200 cm
S	1400 m	30 cm	100 cm	150 cm

Zone centre		Epaisseur de neige		
Nival manteau		1500m	2000m	2500m
N	1300 m	30 cm	150 cm	200 cm
S	1400 m	10 cm	100 cm	150 cm

Zone sud		Epaisseur de neige		
Nival manteau		1500m	2000m	2500m
N	1300 m	30 cm	120 cm	150 cm
S	1400 m	10 cm	60 cm	100 cm

BUTLLETÍ DEL PERILL D'ALLAUS DEL PRINCIPAT D'ANDORRA

Servei meteorològic nacional
Principat d'Andorra

Des informations détaillées par espace naturel protégé

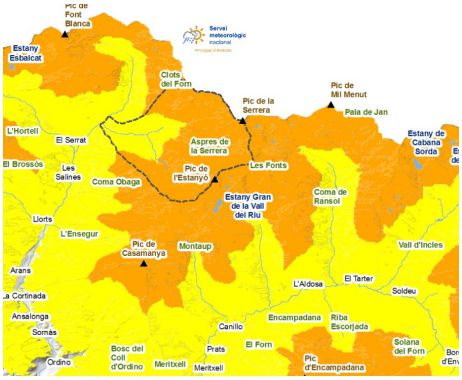

SORTENY

Les chutes de neige du week-end ont été constantes et ont laissé des épaisseurs de neige fraîche supérieures à 50 cm, façonnées par le vent. La pluie humidifiera le manteau jusqu'à des niveaux moyens et la surcharge pourra faire tomber les avalanches de manière naturelle. Les activités en dehors des pistes contrôlées nécessitent de l'expérience et un grand soin dans le choix du territoire. , , ,

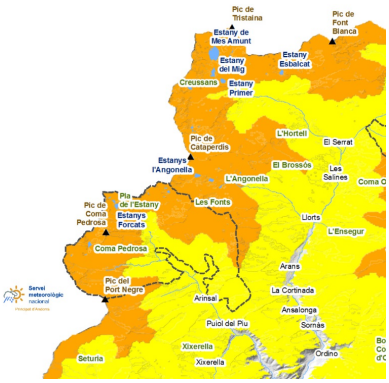

COMAPEDROSA

Les activités de montagne ne sont pas recommandées tant que la neige récente n'est pas stabilisée. De nombreuses avalanches naturelles sont attendues. , , ,

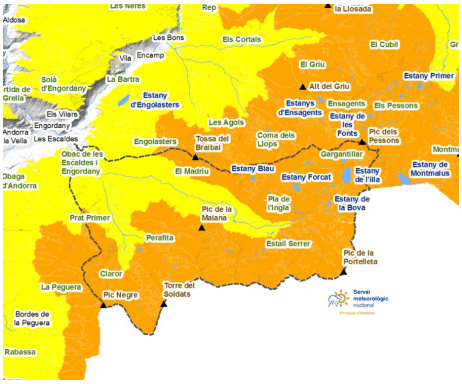

MADRIU-PERAFITA-CLAROR

Il y a aussi de la neige dans la partie supérieure du Madriu, même si les chutes de neige dans le sud du pays ont été moins intenses, on s'attend également à la formation de plaques de vent. La pluie humidifiera la neige récente à basse altitude, rendant l'accès à skis difficile. , , ,

Govern d'Andorra

EAWS
EUROPEAN AVALANCHE WARNING SERVICES

Aquest butlletí ha estat elaborat seguint les normes i recomanacions de l'**European Avalanche Warning Services**, del qual el **Servei meteorològic Nacional** n'és membre

BUTLLETÍ DEL PERILL D'ALLAUS DEL PRINCIPAT D'ANDORRA

Servei meteorològic nacional
Principat d'Andorra

Couche de neige fraiche des derniers jours (De 24 h mesurée à 06:00 h UTC)

	13/02/2026	14/02/2026	15/02/2026	16/02/2026
FEDA (Central)	0 cm	0 cm	0 cm	0 cm
Engolasters - FEDA	10 cm	3 cm	0 cm	0 cm
Bony de les Neres	14 cm	0 cm	0 cm	0 cm
Sorteny	36 cm	0 cm	2 cm	4 cm
Les Fonts d'Arinsal	18 cm	0 cm	0 cm	0 cm
Perafita	0 cm	12 cm	0 cm	0 cm
Tossa Espiolets	8 cm	3 cm	56 cm	0 cm
Grau Roig - FEDA	10 cm	0 cm	0 cm	0 cm
Fontverd	8 cm	13 cm	0 cm	0 cm
Ransol - FEDA	13 cm	2 cm	0 cm	0 cm
Setúria	8 cm	0 cm	0 cm	0 cm
Caborreu	8 cm	0 cm	4 cm	6 cm
Envalira Antenes	6 cm	8 cm	0 cm	0 cm