MINISTERO DELLA DIFESA

meteomont
Servizio Nazionale di previsione neve e valanghe

EAWS EUROPEAN AVALANCHE WARNING SERVICES

CARABINIERI

AERONAUTICA MILITARE SERVIZIO METEOROLOGICO

# ALPI CARNICHE OCCIDENTALI

Bollettino Valanghe N. 347/2026 del 16/02/2026 ore 14.00
Validità 48 ore prossima emissione 17/02/2026

**A cura del Servizio METEOMONT dell'ARMA dei CARABINIERI**
**In collaborazione con Servizio Meteorologico dell'Aeronautica militare**

## SITUAZIONE alle 14:00 del 16/02/2026

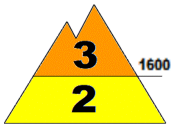


**SITUAZIONE TIPO: neve a debole coesione e vento.**

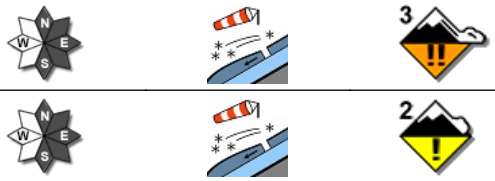


**SITUAZIONE TIPO: neve a debole coesione e vento.**

| Quota neve (mslm) | Nord | Sud |
|---|---|---|
| | 700 | 900 - 1000 |

| Altezza Neve (cm) | Neve al suolo | Neve Fresca | Quota (mslm) |
|---|---|---|---|
| | 93 | 00 | 1870 |
| | 60 | 03 | 1425 |

**VALANGHE OSSERVATE: -.**

## PREVISIONI 17/02/2026

# GRADO DI PERICOLO: MARCATO 3

## SITUAZIONE TIPO: neve a debole coesione e vento.

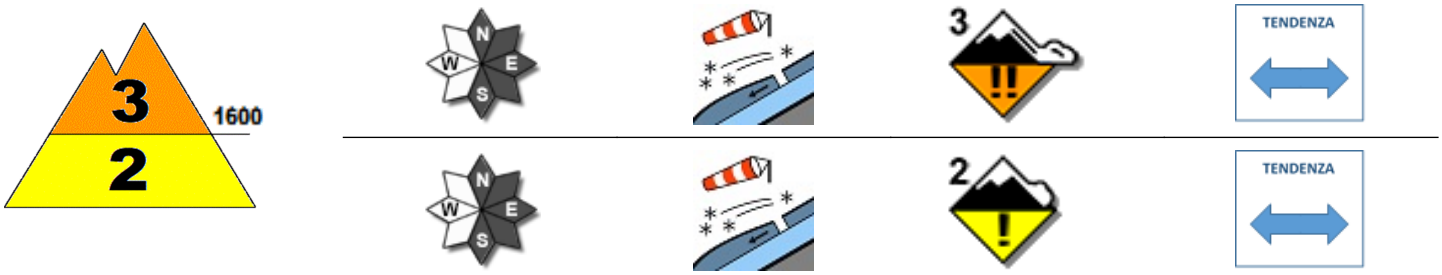


## SITUAZIONE TIPO: neve a debole coesione e vento.

**MANTO NEVOSO: La stabilità del manto nevoso è scarsa su molti punti (aree) per versanti da nord a sud compresi al di sopra di 1600 mslm, possibili valanghe di dimensioni medie.**
**La stabilità del manto nevoso è scarsa su pochi punti (aree) per versanti da nord a sud compresi al di sotto di 1600 mslm, possibili valanghe di dimensioni medie.**

## AVVERTENZE

A seguito dell'attività eolica registrata sono da evitare le zone di accumulo, conche, canaloni, cambi di pendenza e pendii sotto vento in genere.

## SCALA EUROPEA DEL GRADO DI PERICOLO VALANGHE

*5 - MOLTO FORTE* | *4 - FORTE* | *3 - MARCATO* | *2 - MODERATO* | *1 - DEBOLE* | NO NEVE *NO NEVE* | *NO INFO*

## LEGENDA PROBLEMA

*NEVE FRESCA* | *LASTRONI DA VENTO* | *STRATI DEBOLI PERSISTENTI* | *NEVE BAGNATA* | *SLITTAMENTO* | *CORNICI* | *NESSUN PROBLEMA VALANGHIVO EVIDENTE* | *NO_INFO*

**Bollettino realizzato su scala sinottica-regionale (standard EAWS). La sua valutazione non può escludere in alcun modo la necessità di una seria e capace valutazione locale del pericolo (singolo pendio) che può essere anche sensibilmente diverso. Le previsioni meteorologiche sono relative all'orario UTC (per l'Italia +1 in inverno e +2 in estate).**

MINISTERO DELLA DIFESA

meteomont
Servizio Nazionale di previsione neve e valanghe

EAWS EUROPEAN AVALANCHE WARNING SERVICES

CARABINIERI

# ALPI CARNICHE OCCIDENTALI

## PREVISIONE METEO

| Quota | | 17/02/2026 h6:00 | 17/02/2026 h12:00 | 17/02/2026 h18:00 |
|---|---|---|---|---|
| 1000 | Venti | 02 Nodi da Ovest | 03 nodi da N-Ovest | 03 Nodi da Ovest |
| | Temperature | -06 °C | -04 °C | -05 °C |
| | Temp.percepita | -6 °C | -6 °C | -8 °C |
| 2000 | Venti | 03 nodi da N-Ovest | 08 nodi da N-Ovest | 06 Nodi da Ovest |
| | Temperature | -06 °C | -06 °C | -06 °C |
| | Temp.percepita | -9 °C | -12 °C | -11 °C |
| 3000 | Venti | 16 nodi da N-Ovest | 21 nodi da N-Ovest | 13 nodi da N-Ovest |
| | Temperature | -14 °C | -14 °C | -14 °C |
| | Temp.percepita | -25 °C | -26 °C | -24 °C |
| Zero termico | | 0700-0900 m. | 1000-1200 m. | 0800-1000 m. |
| Fenomeno | | — | — | — |
| Stato del cielo | | | | |

## LEGENDA FENOMENI

— Assenza Fenomeni · Nebbia · Foschia · Pioggia debole · Pioggia moderata · Pioggia forte · Temporali

Nevicata debole · Nevicata moderata · Nevicata forte

## STATO DEL CIELO

Sereno · Poco nuvoloso · Nuvoloso · Molto nuvoloso · Coperto

## Parametri meteonivometrici registrati presso i campi di rilevamento il 16/02/2026.

| Località | Comune | Quota (m.s.l.m.) | Altezza neve (cm) | Neve caduta nelle 24 ore (cm) | Temp. Min (°C) | Temp. Max (°C) | Condizioni del tempo |
|---|---|---|---|---|---|---|---|
| SAURIS DI SOPRA | Sauris (UD) | 1425 | 60 | 3 | -4 | +7 | Assenza di precipitazioni |

(*) Rilievi fuori campo

**L'INFORMAZIONE E' PREVENZIONE - LEGGI L'ATTUALE GRADO DI PERICOLO VALANGHE!**

**IL CAPO DEL CENTRO NAZIONALE METEOMONT**
**(Ten. Col. RFI Emanuela Gini)**
**FIRMA AUTOGRAFA OMESSA AI SENSI**
**DELL'ART.3 DEL D.LGS N.39/1993**