MINISTERO DELLA DIFESA

meteomont Servizio Nazionale di previsione neve e valanghe

EAWS EUROPEAN AVALANCHE WARNING SERVICES

CARABINIERI

In collaborazione con: arpav

DOLOMITI SETTENTRIONALI

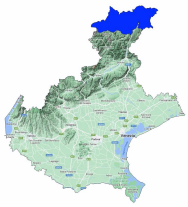

Bollettino Valanghe N. 348/2026 del 17/02/2026 ore 14.00
Validità 48 ore prossima emissione 18/02/2026

A cura del Servizio METEOMONT dell'ARMA dei CARABINIERI
In collaborazione con Servizio Meteorologico dell'Aeronautica militare

SITUAZIONE alle 14:00 del 17/02/2026

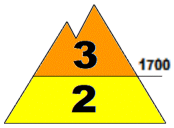

SITUAZIONE TIPO: nessuna situazione tipo evidente.



SITUAZIONE TIPO: neve a debole coesione e vento.

Quota neve (mslm)	Nord	Sud
	1000 - 1200	1400 - 1500

Altezza Neve (cm)	Neve al suolo	Neve Fresca	Quota (mslm)
	095	002	2151
	084	000	1930

VALANGHE OSSERVATE: Nessuna valanga.

PREVISIONI 18/02/2026

GRADO DI PERICOLO: MARCATO 3

SITUAZIONE TIPO: neve a debole coesione e vento.

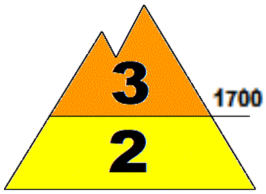

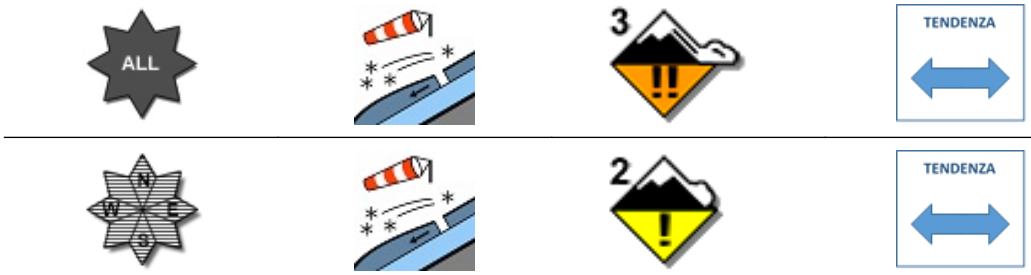

SITUAZIONE TIPO: neve a debole coesione e vento.

MANTO NEVOSO: La stabilità del manto nevoso è scarsa su molti punti (aree) per tutte le esposizioni al di sopra di 1700 mslm, possibili valanghe di dimensioni medie.
La stabilità del manto nevoso è scarsa su alcuni punti (aree) per isolati pendii al di sotto di 1700 mslm, possibili valanghe di dimensioni medie.

AVVERTENZE

A seguito dell'attività eolica registrata sono da evitare le zone di accumulo, conche, canaloni, cambi di pendenza e pendii sotto vento in genere.

SCALA EUROPEA DEL GRADO DI PERICOLO VALANGHE

5 - MOLTO FORTE | 4 - FORTE | 3 - MARCATO | 2 - MODERATO | 1 - DEBOLE | NO NEVE | NO INFO

LEGENDA PROBLEMA

NEVE FRESCA | LASTRONI DA VENTO | STRATI DEBOLI PERSISTENTI | NEVE BAGNATA | SLITTAMENTO | CORNICI | NESSUN PROBLEMA VALANGHIVO EVIDENTE | NO_INFO

Bollettino realizzato su scala sinottica-regionale (standard EAWS). La sua valutazione non può escludere in alcun modo la necessità di una seria e capace valutazione locale del pericolo (singolo pendio) che può essere anche sensibilmente diverso. Le previsioni meteorologiche sono relative all'orario UTC (per l'Italia +1 in inverno e +2 in estate).

MINISTERO DELLA DIFESA

meteomont
Servizio Nazionale di previsione neve e valanghe

EAWS EUROPEAN AVALANCHE WARNING SERVICES

CARABINIERI

In collaborazione con: arpav

DOLOMITI SETTENTRIONALI

PREVISIONE METEO

Quota		18/02/2026 h6:00	18/02/2026 h12:00	18/02/2026 h18:00
1000	Venti	01 nodi da N-Ovest	00 Calma	01 Nodi da S-Est
	Temperature	-10 °C	-06 °C	-05 °C
	Temp.percepita	-10 °C	-6 °C	-5 °C
2000	Venti	02 Nodi da Ovest	01 Nodi da Ovest	01 Nodi da S-Ovest
	Temperature	-09 °C	-06 °C	-06 °C
	Temp.percepita	-9 °C	-6 °C	-6 °C
3000	Venti	11 nodi da N-Ovest	09 Nodi da Ovest	09 nodi da N-Ovest
	Temperature	-15 °C	-11 °C	-09 °C
	Temp.percepita	-24 °C	-18 °C	-16 °C
Zero termico		0100-0300 m.	0900-1100 m.	0700-0900 m.
Fenomeno		—	—	—
Stato del cielo				

LEGENDA FENOMENI

— Assenza Fenomeni · Nebbia · Foschia · Pioggia debole · Pioggia moderata · Pioggia forte · Temporali

Nevicata debole · Nevicata moderata · Nevicata forte

STATO DEL CIELO

Sereno · Poco nuvoloso · Nuvoloso · Molto nuvoloso · Coperto

Parametri meteonivometrici registrati presso i campi di rilevamento il 17/02/2026.

Località	Comune	Quota (m.s.l.m.)	Altezza neve (cm)	Neve caduta nelle 24 ore (cm)	Temp. Min (°C)	Temp. Max (°C)	Condizioni del tempo
MISURINA	Auronzo di Cadore (BL)	1759	61	1	-13	+14	Nevicata debole continua
MONTE AGUDO	Auronzo di Cadore (BL)	1530	64	Tracce di neve	-7	-1	Assenza di precipitazioni
MONTE FALORIA	Cortina d'Ampezzo (BL)	2119	71	0	-8	+7	Precipitazioni all'orizzonte (pioggia, neve, grandine, temporali) ma non sulla stazione
COL DELLA TENDA	Comelico Superiore (BL)	1930	84	0	-8	+6	Assenza di precipitazioni
COL DE VARDA *	Auronzo di Cadore (BL)	2151	95	2	N.P.	N.P.	Nevicata debole continua
CREPA NEGRA *	Cortina d'Ampezzo (BL)	2159	82	0	N.P.	N.P.	Precipitazioni all'orizzonte (pioggia, neve, grandine, temporali) ma non sulla stazione

(*) Rilievi fuori campo

L'INFORMAZIONE E' PREVENZIONE - LEGGI L'ATTUALE GRADO DI PERICOLO VALANGHE!

IL CAPO DEL CENTRO NAZIONALE METEOMONT
(Ten. Col. RFI Emanuela Gini)
FIRMA AUTOGRAFA OMESSA AI SENSI
DELL'ART.3 DEL D.LGS N.39/1993

Bollettino realizzato su scala sinottica-regionale (standard EAWS). La sua valutazione non può escludere in alcun modo la necessità di una seria e capace valutazione locale del pericolo (singolo pendio) che può essere anche sensibilmente diverso. Le previsioni meteorologiche sono relative all'orario UTC (per l'Italia +1 in inverno e +2 in estate).