MINISTERO DELLA DIFESA

meteomont
Servizio Nazionale di previsione neve e valanghe

EAWS EUROPEAN AVALANCHE WARNING SERVICES

CARABINIERI

ALPI RETICHE

Bollettino Valanghe N. 350/2026 del 17/02/2026 ore 14.00
Validità 48 ore prossima emissione 18/02/2026

A cura del Servizio METEOMONT dell'ARMA dei CARABINIERI
In collaborazione con Servizio Meteorologico dell'Aeronautica militare

SITUAZIONE alle 14:00 del 17/02/2026

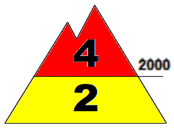

SITUAZIONE TIPO: neve a debole coesione e vento.



SITUAZIONE TIPO: strato debole persistente basale.

Quota neve (mslm)	Nord	Sud
	900 - 1100	1200 - 1500

Altezza Neve (cm)	Neve al suolo	Neve Fresca	Quota (mslm)
	83	13	2280
	059	2	1640

VALANGHE OSSERVATE: -.

PREVISIONI 18/02/2026

GRADO DI PERICOLO: FORTE 4

SITUAZIONE TIPO: neve a debole coesione e vento.

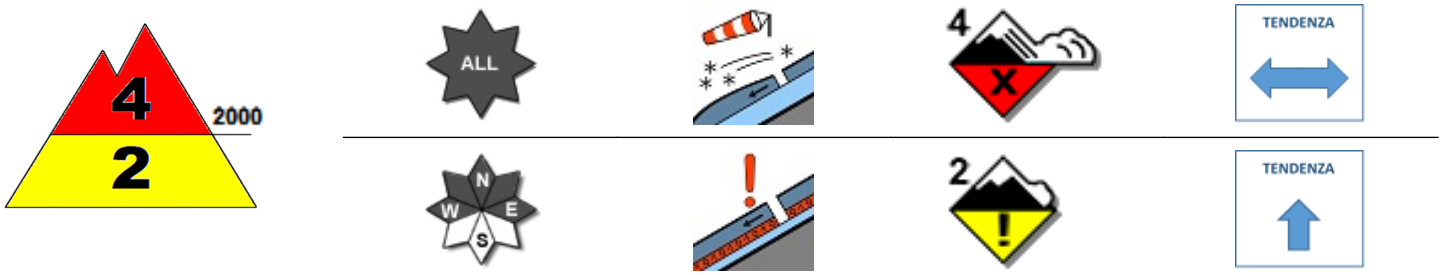

SITUAZIONE TIPO: strato debole persistente basale.

MANTO NEVOSO: La stabilità del manto nevoso è molto scarsa su molti punti (aree) per tutte le esposizioni al di sopra di 2000 mslm, possibili valanghe di dimensioni grandi.
La stabilità del manto nevoso è scarsa su alcuni punti (aree) per versanti da ovest a est al di sotto di 2000 mslm, possibili valanghe di dimensioni medie.

AVVERTENZE

In considerazione delle avverse condizioni meteorologiche in atto, le attività al di fuori delle piste battute e segnalate sono sconsigliate.

SCALA EUROPEA DEL GRADO DI PERICOLO VALANGHE

LEGENDA PROBLEMA

Bollettino realizzato su scala sinottica-regionale (standard EAWS). La sua valutazione non può escludere in alcun modo la necessità di una seria e capace valutazione locale del pericolo (singolo pendio) che può essere anche sensibilmente diverso. Le previsioni meteorologiche sono relative all'orario UTC (per l'Italia +1 in inverno e +2 in estate).

Bollettino sottoposto a processi di: Acquisizione e controllo del C-Sifa e della rete di Osservatori e Esperti - Validazione del Previsore di turno - Certificazione della Sezione Meteomont.

MINISTERO DELLA DIFESA

meteomont
Servizio Nazionale di previsione neve e valanghe

EAWS EUROPEAN AVALANCHE WARNING SERVICES

CARABINIERI

ALPI RETICHE

PREVISIONE METEO

Quota		18/02/2026 h6:00	18/02/2026 h12:00	18/02/2026 h18:00
1000	Venti	01 nodi da N-Ovest	01 Nodi da N-Est	01 Nodi da S-Est
	Temperature	-06 °C	-04 °C	-05 °C
	Temp.percepita	-6 °C	-4 °C	-5 °C
2000	Venti	01 nodi da N-Ovest	01 Nodi da N-Est	01 Nodi da S-Est
	Temperature	-06 °C	-04 °C	-05 °C
	Temp.percepita	-6 °C	-4 °C	-5 °C
3000	Venti	08 nodi da N-Ovest	06 Nodi da Ovest	03 Nodi da Ovest
	Temperature	-11 °C	-10 °C	-07 °C
	Temp.percepita	-18 °C	-16 °C	-10 °C
Zero termico		0800-1000 m.	1100-1300 m.	1000-1200 m.
Fenomeno		—	—	—
Stato del cielo				

LEGENDA FENOMENI

— Assenza Fenomeni · Nebbia · Foschia · Pioggia debole · Pioggia moderata · Pioggia forte · Temporali

Nevicata debole · Nevicata moderata · Nevicata forte

STATO DEL CIELO

Sereno · Poco nuvoloso · Nuvoloso · Molto nuvoloso · Coperto

Parametri meteonivometrici registrati presso i campi di rilevamento il 17/02/2026.

Località	Comune	Quota (m.s.l.m.)	Altezza neve (cm)	Neve caduta nelle 24 ore (cm)	Temp. Min (°C)	Temp. Max (°C)	Condizioni del tempo
BORMIO2000-LECCIONA	Valdisotto (SO)	2050	69	11	-7	-1	Nevicata forte
NASSEGNO *	Valfurva (SO)	1805	51	4	N.P.	N.P.	Nevicata debole continua
ALPE PALU'	Chiesa in Valmalenco (SO)	2010	83	6	-7	+1	Nevicata moderata
COLONIA VIGILI	Ponte di Legno (BS)	1640	59	2	-6	+4	Nevicata moderata
PISTA STELVIO *	Valdisotto (SO)	2280	83	13	N.P.	N.P.	Nevicata moderata
VALLE DI STERLA *	Madesimo (SO)	1724	74	20	N.P.	N.P.	Nevicata moderata

(*) Rilievi fuori campo

L'INFORMAZIONE E' PREVENZIONE - LEGGI L'ATTUALE GRADO DI PERICOLO VALANGHE!

IL CAPO DEL CENTRO NAZIONALE METEOMONT
(Ten. Col. RFI Emanuela Gini)
FIRMA AUTOGRAFA OMESSA AI SENSI
DELL'ART.3 DEL D.LGS N.39/1993

Bollettino realizzato su scala sinottica-regionale (standard EAWS). La sua valutazione non può escludere in alcun modo la necessità di una seria e capace valutazione locale del pericolo (singolo pendio) che può essere anche sensibilmente diverso. Le previsioni meteorologiche sono relative all'orario UTC (per l'Italia +1 in inverno e +2 in estate).