Bulletin d'estimation du risque d'avalanche
(valable en dehors des pistes balisées et ouvertes)

MASSIF : Bauges

Rédigé le mardi 17 Février 2026 à 16h

Estimation des risques pour le : MERCREDI 18 FÉVRIER

INSTABILITÉS FORMÉES PAR LE VENT DE NORD-OUEST À SUD-OUEST. FORMATION DE NOMBREUSES ACCUMULATIONS/CONGÈRES ET DÉPARTS SPONTANÉS POSSIBLES.

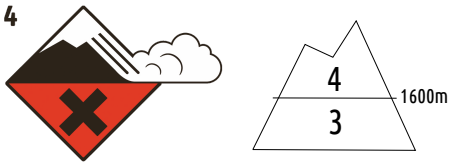

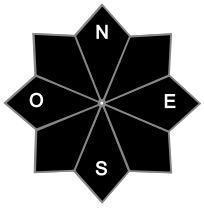

Au-dessus de 1600m indice de risque fort, plus bas indice marqué.

Départs spontanés : Les pentes se remplissent avec le transport par le vent. Possibles grandes avalanches.

Déclenchements provoqués : Nombreuses plaques à vent réactives dans la neige récente.

Indices de risque : 5 très fort - 4 fort - 3 marqué - 2 limité - 1 faible -- En noir : les pentes les plus dangereuses

Stabilité du manteau neigeux

Situation avalancheuse typique : neige ventée

Déclenchements provoqués :
* **Plaques dans la neige récente**. Plus nombreuses et épaisses au dessus de 1600/1800 m. Formées et en cours de formation par **le vent de Nord-Ouest à Sud-Ouest** de ces deniers jours. Bien **réactives** sous les skis/raquettes. Taille 2 (moyenne) à 3 (grande). Cassures possibles de 30/70cm selon les pentes.
Observables : fissures devant les skis, zones d'accumulation, transport de neige par le vent ...

Départs spontanés :
* **Instabilités dans l'épaisse couche de neige récente**. Rares départs par **surcharge lors de transport de neige par le vent de Nord-Ouest à Sud-Ouest** dans les pentes. Taille 2 (moyenne) à 3 (grande).
* **Départs dans la neige récente au fil du réchauffement**. Départs plus probables sous les éclaircies dans les pentes au soleil.

Qualité de la neige

Enneigement : Bon à excédentaire pour la saison grâce aux fréquentes chutes de neige du mois de février. On peut chausser les skis vers 1200 m dans tous les versants. L'épaisseur du manteau neigeux varie : nombreuses congères et corniches.

Qualité de la neige ce mercredi :
* Le matin, quelques cm de neige fraîche en surface, tombés la journée de mardi.
* Neige froide et légère dans le pentes peu soumises au vent de NO à SO. L'enfoncement piéton est important. Dans les pentes exposées au vent de NO à SO, neige durcie/travaillée en surface.
* L'après-midi, le redoux transforme la surface de la neige et l'alourdit à toute altitude, notamment dans les versants au soleil).
* Manteau neigeux irrégulier, dépendant de la topographie : combes chargées, crêtes et arêtes décapées.

Aperçu météo pour le mercredi 18 février

nuit	matin	après-midi	soir

Ciel couvert. Floconnade en matinée, plus lumineux l'après-midi. Vent d'Ouest à Sud/Ouest fort en altitude.

Pluie-Neige		1 300 m		
Iso 0 °C	1 400 m	1 700 m	2 100 m	2 300 m
Vent 1500 m	10 km/h	15 km/h	20 km/h	40 km/h
Vent 2000 m	15 km/h	20 km/h	30 km/h	60 km/h

Épaisseur de neige hors-piste

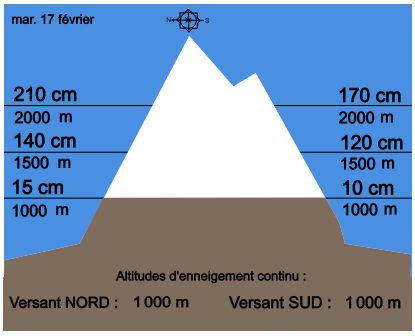

Précipitations à 1800 m

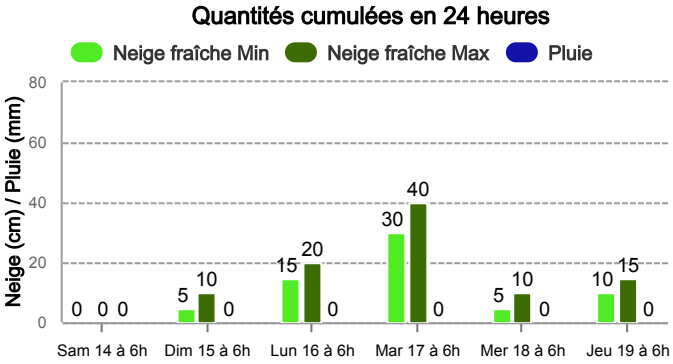

Tendance du jeudi 19 février

Indice de risque fort

Des importantes chutes s'installent dans la nuit de mercredi à jeudi et sur la journée de jeudi : 15-30 cm de neige attendus au-dessus de 1500 m (limite pluie-neige vers 1000 m). De nombreuses instabilités se forment encore au fil des chutes pouvant provoquer de grandes avalanches spontanées.

Pour consulter la vigilance en cours, veuillez vous rendre sur le site https://vigilance.meteofrance.fr/fr

Météo-France - 73 avenue de Paris, 94165 Saint-Mandé cedex - Contact : contact@meteo.fr

Rédigé par Météo-France avec la contribution des observateurs du réseau nivo-météorologiques. Partenariat : ANMSM (Maires de Stations de Montagne), DSF (Domaines Skiables de France), ADSP (Directeurs de Pistes et de la Sécurité des Stations de Sports d'Hiver) et autres acteurs de la montagne.

Bulletin neige & avalanches par téléphone au **0 892 68 10 20** Service 0,35 € / min + prix appel

RÉPUBLIQUE FRANÇAISE
Liberté Égalité Fraternité

METEO FRANCE
À VOS CÔTÉS, DANS UN CLIMAT QUI CHANGE

Bulletin d'estimation du risque d'avalanche

(valable en dehors des pistes balisées et ouvertes)

MASSIF : Bauges

Rédigé le mardi 17 Février 2026 à 16h

Conditions nivo-météo des 7 derniers jours

	mer. 11/02				jeu. 12/02				ven. 13/02				sam. 14/02				dim. 15/02				lun. 16/02				mar. 17/02			
	03h	09h	15h	21h	03h	09h	15h	21h	03h	09h	15h	21h	03h	09h	15h	21h	03h	09h	15h	21h	03h	09h	15h	21h	03h	09h	15h	21h
Météo																												
Vent (km/h)	65	50	45	65	60	60	50	60	50	40	40	30	30	30	35	35	45	35	35	45	45	55	60	55	55	50	40	30
à 2000m	→	→	→	↗	↗	→	→	→	→	↗	↗	↑	↓	↙	↓	↓	↓	↘	↘	→	→	→	→	↘	↘	↘	↘	↘
Vent (km/h)	50	40	35	55	50	40	40	50	40	30	20	20	20	20	25	25	35	20	20	25	30	45	50	40	40	40	25	20
à 1500m	→	↗	↗	↗	↗	↗	→	→	→	↗	↗	↑	↓	↙	↓	↓	↓	↓	↘	↗	↑	→	→	↘	↘	↘	↘	↘

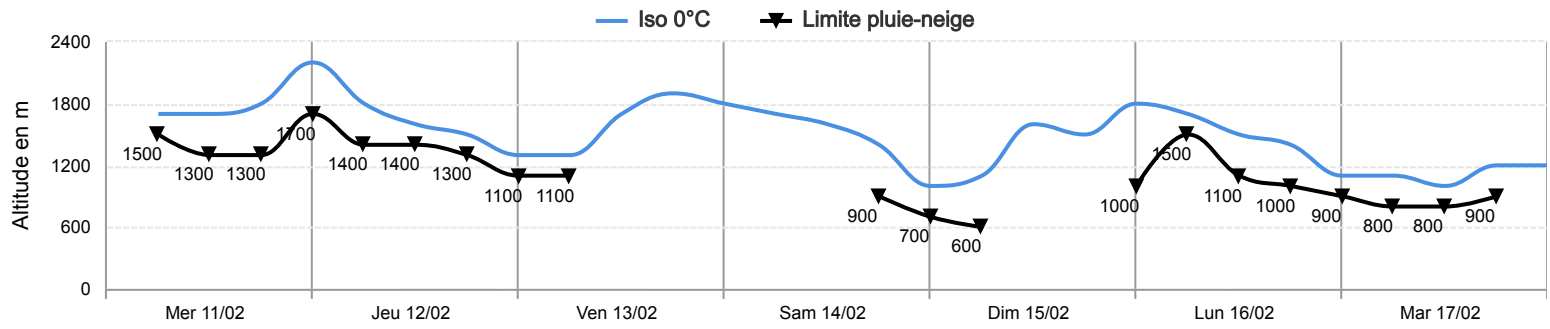

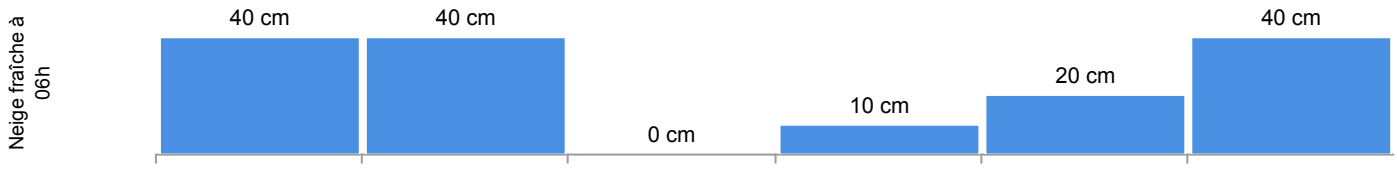

Risque d'avalanche							
	mer. 11/02	jeu. 12/02	ven. 13/02	sam. 14/02	dim. 15/02	lun. 16/02	mar. 17/02

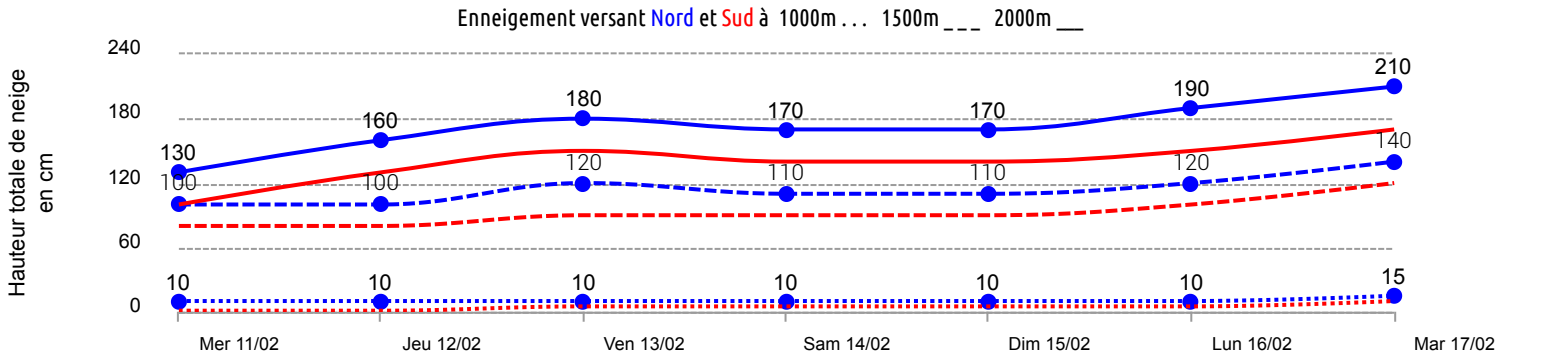

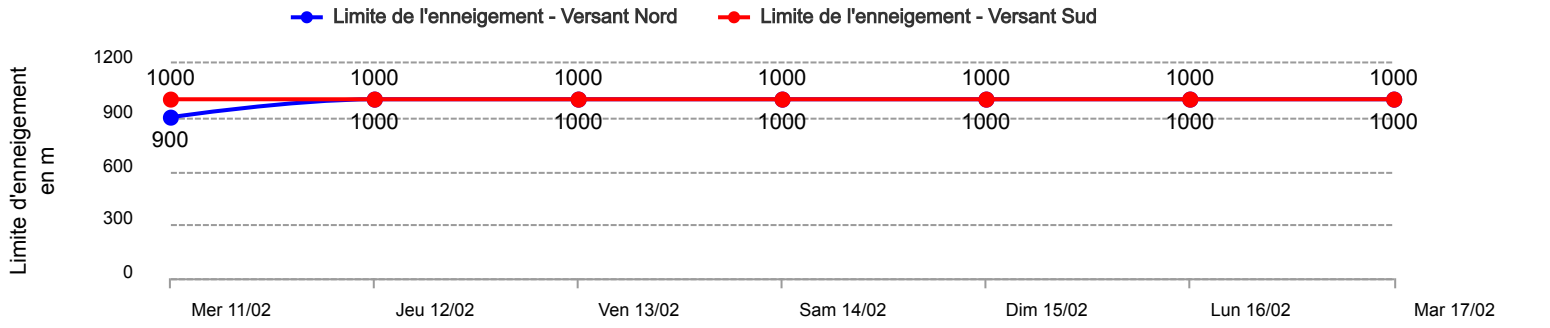

Pour consulter la vigilance en cours, veuillez vous rendre sur le site https://vigilance.meteofrance.fr/fr

Météo-France - 73 avenue de Paris, 94165 Saint-Mandé cedex - Contact : contact@meteo.fr

Rédigé par Météo-France avec la contribution des observateurs du réseau nivo-météorologiques. Partenariat : ANMSM (Maires de Stations de Montagne), DSF (Domaines Skiables de France), ADSP (Directeurs de Pistes et de la Sécurité des Stations de Sports d'Hiver) et autres acteurs de la montagne.

Bulletin neige & avalanches par téléphone au

0 892 68 10 20 Service 0,35 € / min + prix appel