Bulletin d'estimation du risque d'avalanche

(valable en dehors des pistes balisées et ouvertes)

MASSIF : Belledonne

Rédigé le mardi 17 Février 2026 à 16h

Estimation des risques pour le : MERCREDI 18 FÉVRIER

FORT RISQUE ACCIDENTEL EN ALTITUDE. LOCALEMENT, DES AVALANCHES SPONTANEES AU SOLEIL, DEVALANT DE LONGS COULOIRS...

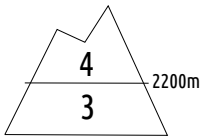

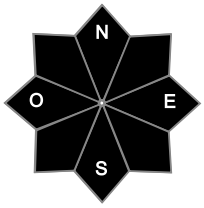

Altitude+ au soleil

Au-dessus de 2200m indice de risque fort, plus bas indice marqué.

Départs spontanés : Mercredi, près des rochers lors d'éclaircies des avalanches de neige récente, parfois conséquentes et descendant les couloirs jusqu'en moyenne montagne ? En pentes herbeuses de modeste altitude, rare avalanche de fond...

Déclenchements provoqués : Risque accidentel encore fort en altitude, parfois à distance de pentes raides... Risque de larges ruptures en "cascade"...

Indices de risque : 5 très fort - 4 fort - 3 marqué - 2 limité - 1 faible -- En noir : les pentes les plus dangereuses

Stabilité du manteau neigeux

Situation avalancheuse typique : neige ventée neige humide

Importantes quantités de neige fraîche/récente très peu stabilisée en altitude avec parfois un risque de déclenchement à distance. Noter aussi un redoux probable lors d'éclaircies, risque d'avalanche spontanée aussi vers les rochers, dans les couloirs...

Départs spontanés :

Mercredi avec un redoux relatif en mi-journée/l'après-midi, on peut s'attendre à de nombreuses avalanches de surface de taille moyenne, notamment près des rochers. Localement ces avalanches peuvent prendre de l'ampleur (pentes récemment chargées par le vent de Nord-Ouest). Une avalanche pourrait dévaler un long couloir avec gros dépôt jusqu'en moyenne montagne?... Enfin dans certaines pentes herbeuses de modeste altitude, on peut redouter une avalanche de fond (glissement au terrain), plutôt le soir.

Déclenchements provoqués :

En haute montagne, les récentes épaisses plaques (formées par flux de Nord-Ouest) ne sont pas bien stabilisées. Ce risque accidentel est aussi présent loin des crêtes, au passage d'une personne... Par déclenchement en cascade une très grande avalanche n'est pas exclue en contrebas (configuration locale aggravante : présence de couches fragiles enfouies en versants froids).

Sous 2000/2200m environ les sous couches se sont un peu tassées, risque accidentel a priori plus localisé, près des crêtes. En pentes ensoleillées, risque de départ humide ponctuel sous les skis...

Mercredi soir le vent de Sud-Sud-Ouest va se lever en altitude et formera de nouvelles plaques bien instables !

Qualité de la neige

Qualification de l'enneigement : L'enneigement est faible aux basses altitude, très bon pour la saison dès la moyenne altitude puis abondant dès 1800m et dans toutes les combes... Hautes crêtes parfois dégarnies/ grosses congères et corniches...

Limites skiables : vers 1200/1400 m...

Qualité de la neige mercredi : Le matin neige fraîche poudreuse en combes abritées, épaisse en altitude.

Lors des éclaircies, sous 2000/2200m environ neige collante puis humide en surface. A l'abord des croupes/crêtes d'altitude neige très chahutée, irrégulière, de grosses corniches...

Aperçu météo pour le mercredi 18 février

	nuit	matin	après-midi	soir

Passages nuageux le matin, puis des éclaircies l'après-midi, rafales de Sud mercredi soir, avant une nouvelle perturbation...

Pluie-Neige	800 m	1 000 m		1 800 m
Iso 0 °C	1 300 m	1 800 m	2 200 m	2 300 m
Vent 2000 m	↓ 20 km/h	↗ 20 km/h	↗ 20 km/h	↑ 75 km/h
Vent 3000 m	↘ 45 km/h	↘ 30 km/h	↗ 40 km/h	↗ 90 km/h

Épaisseur de neige hors-piste

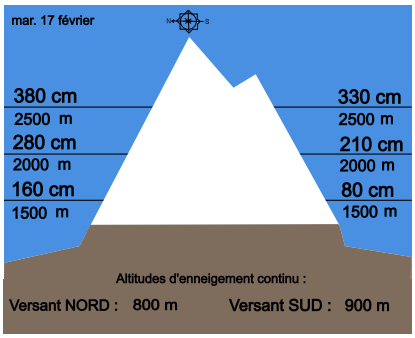

Précipitations à 1800 m

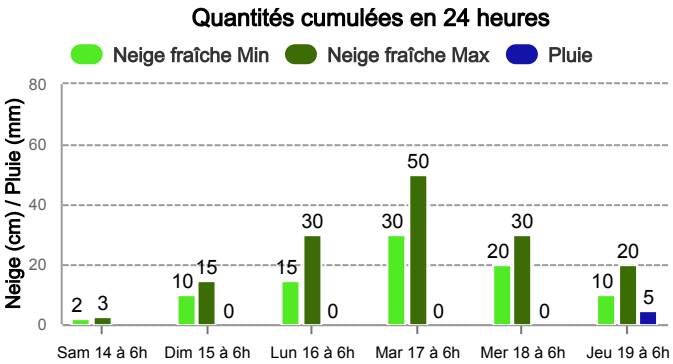

Tendance du jeudi 19 février

Indice de risque fort

Risque d'avalanche en hausse progressive jeudi.

Jeudi 20 cm de fraîche le matin, 50 voire 60 cm le soir sous le vent de Nord Ouest.

Risque de rupture de corniches/épaisses plaques. Nombreux couloirs impactés...

Pour consulter la vigilance en cours, veuillez vous rendre sur le site https://vigilance.meteofrance.fr/fr

Météo-France - 73 avenue de Paris, 94165 Saint-Mandé cedex - Contact : contact@meteo.fr

Bulletin neige & avalanches par téléphone au 0 892 68 10 20 Service 0,35 € / min + prix appel

Rédigé par Météo-France avec la contribution des observateurs du réseau nivo-météorologiques. Partenariat : ANMSM (Maires de Stations de Montagne), DSF (Domaines Skiables de France), ADSP (Directeurs de Pistes et de la Sécurité des Stations de Sports d'Hiver) et autres acteurs de la montagne.

Bulletin d'estimation du risque d'avalanche

(valable en dehors des pistes balisées et ouvertes)

MASSIF : Belledonne

Rédigé le mardi 17 février 2026 à 16h

Conditions nivo-météo des 7 derniers jours

	mer. 11/02				jeu. 12/02				ven. 13/02				sam. 14/02				dim. 15/02				lun. 16/02				mar. 17/02			
	03h	09h	15h	21h	03h	09h	15h	21h	03h	09h	15h	21h	03h	09h	15h	21h	03h	09h	15h	21h	03h	09h	15h	21h	03h	09h	15h	21h
Météo																												
Vent (km/h)	100	85	85	100	100	100	90	50	40	30	35	15	30	15	40	40	50	40	45	65	75	100	110	115	95	75	55	40
à 3000m																												
Vent (km/h)	80	55	55	90	80	85	75	30	25	10	10	15	20	15	25	30	30	20	15	35	50	70	80	85	80	60	40	25
à 2000m																												

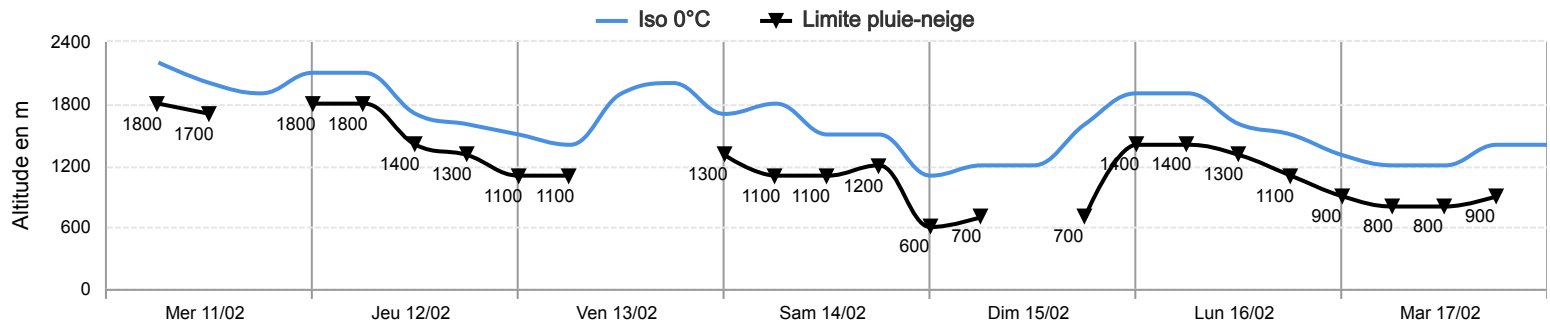

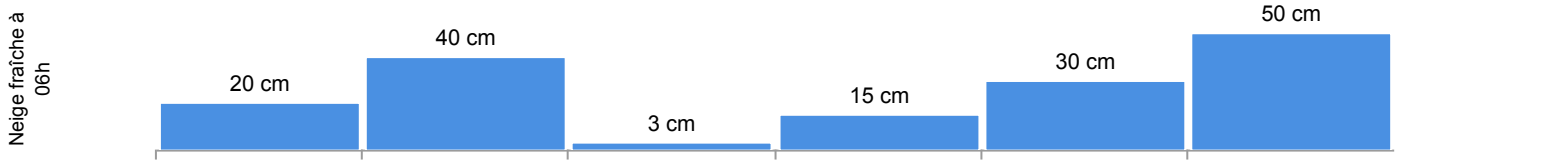

Risque d'avalanche	mer. 11/02	jeu. 12/02	ven. 13/02	sam. 14/02	dim. 15/02	lun. 16/02	mar. 17/02
	4	4	4	3	3	4	4

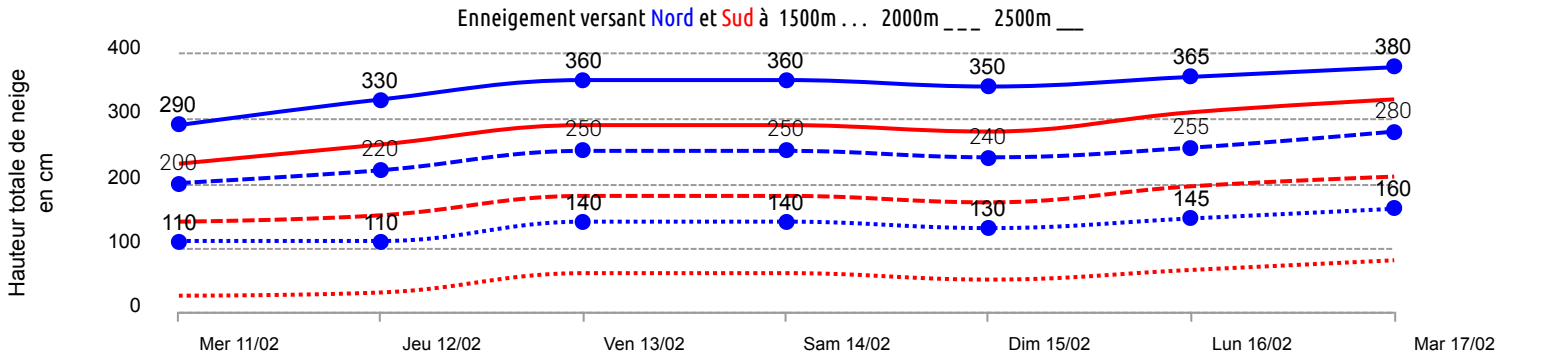

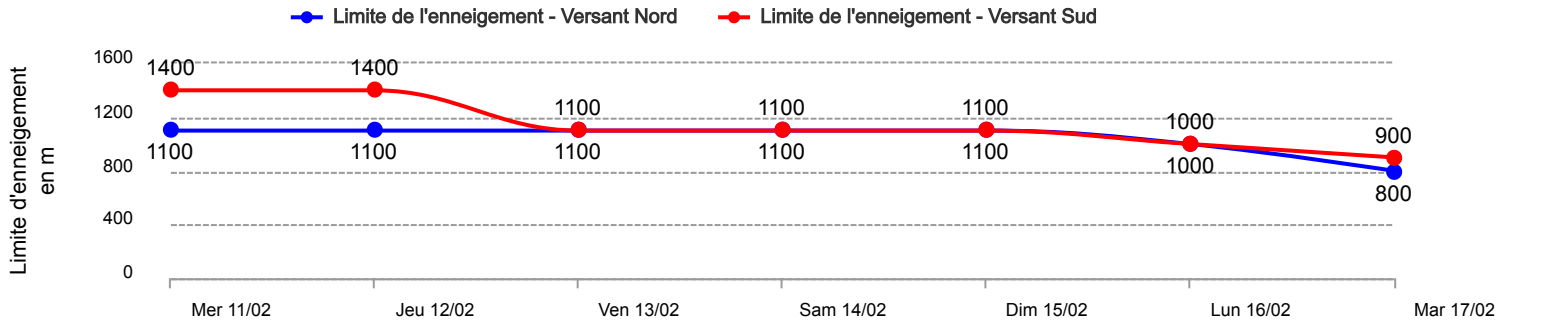

Pour consulter la vigilance en cours, veuillez vous rendre sur le site https://vigilance.meteofrance.fr/fr

Météo-France - 73 avenue de Paris, 94165 Saint-Mandé cedex - Contact : contact@meteo.fr

Rédigé par Météo-France avec la contribution des observateurs du réseau nivo-météorologiques. Partenariat : ANMSM (Maires de Stations de Montagne), DSF (Domaines Skiables de France), ADSP (Directeurs de Pistes et de la Sécurité des Stations de Sports d'Hiver) et autres acteurs de la montagne.

Bulletin neige & avalanches par téléphone au 0 892 68 10 20 Service 0,35 € / min + prix appel