Bulletin d'estimation du risque d'avalanche

(valable en dehors des pistes balisées et ouvertes)

MASSIF : Chartreuse

Rédigé le mardi 17 Février 2026 à 16h

Estimation des risques pour le : MERCREDI 18 FÉVRIER

DES AVALANCHES SPONTANEES AU SOLEIL, VERS LES HAUTES CRETES ENCORE UN RISQUE DE PLAQUES...

3

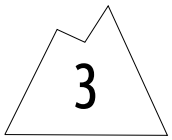

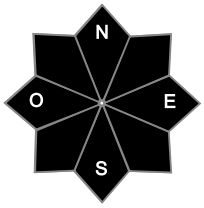

Altitude + soleil

Indices de risque : 5 très fort - 4 fort - 3 marqué - 2 limité - 1 faible -- En noir : les pentes les plus dangereuses

Indice de risque marqué.

Départs spontanés : Mercredi lors d'éclaircies des coulées ponctuelles et avalanches de neige récente, parfois une avalanche de fond (glissement en pente herbeuse) ...

Déclenchements provoqués : Risque de plaque à l'abord des crêtes/sommets, parfois sous les barres rocheuses...

Stabilité du manteau neigeux

Situation avalancheuse typique : neige ventée neige humide

Pas mal de neige fraîche/récente peu stabilisée, plus un redoux probable lors d'éclaircies, risque d'avalanche encore marqué mercredi...

Départs spontanés :

Mercredi avec un redoux possible en mi-journée, l'après-midi, on peut s'attendre à de nombreuses coulées ponctuelles/avalanches de surface.
Localement ces avalanches pourraient prendre de l'ampleur (de taille moyenne à grandes) dans les couloirs récemment chargées par le vent de Nord-Ouest ?
Enfin dans certaines pentes herbeuses, on peut redouter une avalanche de fond (glissement au terrain)

Déclenchements provoqués :

En pentes ensoleillées, risque de départ humide ponctuel sous les skis... Sinon en altitude les récentes plaques formées ne sont pas toutes stabilisées. Risque encore localement présent, notamment au passage de skieurs groupés. Une épaisse cassure accidentelle n'est pas exclue.
Vigilance aussi à l'abord des corniches... En pieds de barres rocheuses la neige est également plus cohésive, le risque accidentel n'est pas exclu. Mercredi soir le vent de Sud-Sud-Ouest va se lever et formera de nouvelles plaques.

Qualité de la neige

Qualification de l'enneigement : L'enneigement est faible aux basses altitudes, sous les sapins mais il est très bon pour la saison dès la moyenne altitude et dans les combes sommitales... Crêtes parfois dégarnies/ grosses congères et corniches sommitales...

Limites skiables : vers 1200/1300 m... sur les pistes forestières/clairières...

Qualité de la neige mercredi : Le matin neige fraîche poudreuse (plus conséquente et soufflée en altitude, jusque 40/70 cm).
Lors des éclaircies, neige collante puis humide en surface. Vers les hautes crêtes neige très chahutée, irrégulière, des corniches...

Aperçu météo pour le mercredi 18 février

	nuit	matin	après-midi	soir

Passages nuageux le matin, puis des éclaircies l'après-midi, rafales de Sud mercredi soir, avant une nouvelle perturbation...

Pluie-Neige	900 m	1 100 m		1 800 m
Iso 0 °C	1 300 m	1 800 m	2 200 m	2 300 m
Vent 1500 m	↙ 15 km/h	↑ 15 km/h	↑ 25 km/h	↑ 75 km/h
Vent 2000 m	↓ 30 km/h	→ 20 km/h	↗ 45 km/h	↑ 90 km/h

Épaisseur de neige hors-piste

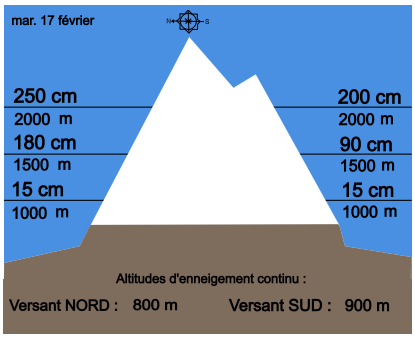

Précipitations à 1800 m

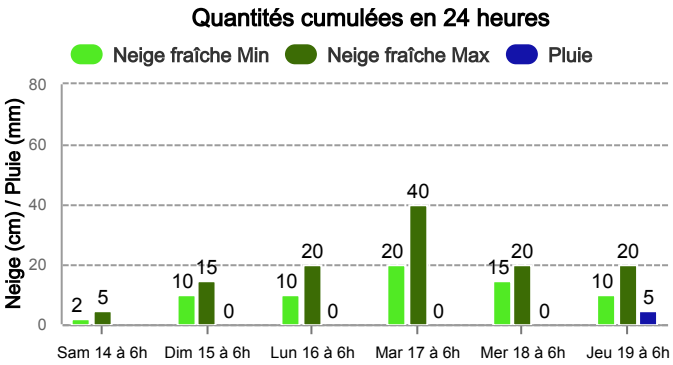

Tendance du jeudi 19 février

Indice de risque fort

Risque d'avalanche en hausse progressive. Jeudi 20 cm de fraîche le matin, 40 voire 50 cm le soir sous le vent de Nord Ouest. En altitude vers de nombreuses plaques et avalanches spontanées, risque de rupture de corniche...

Pour consulter la vigilance en cours, veuillez vous rendre sur le site https://vigilance.meteofrance.fr/fr

Météo-France - 73 avenue de Paris, 94165 Saint-Mandé cedex - Contact : contact@meteo.fr

Rédigé par Météo-France avec la contribution des observateurs du réseau nivo-météorologiques. Partenariat : ANMSM (Maires de Stations de Montagne), DSF (Domaines Skiables de France), ADSP (Directeurs de Pistes et de la Sécurité des Stations de Sports d'Hiver) et autres acteurs de la montagne.

Bulletin neige & avalanches par téléphone au

0 892 68 10 20 Service 0,35 € / min + prix appel

Bulletin d'estimation du risque d'avalanche

(valable en dehors des pistes balisées et ouvertes)

MASSIF : Chartreuse

Rédigé le mardi 17 février 2026 à 16h

Conditions nivo-météo des 7 derniers jours

	mer. 11/02				jeu. 12/02				ven. 13/02				sam. 14/02				dim. 15/02				lun. 16/02				mar. 17/02			
	03h	09h	15h	21h	03h	09h	15h	21h	03h	09h	15h	21h	03h	09h	15h	21h	03h	09h	15h	21h	03h	09h	15h	21h	03h	09h	15h	21h
Météo																												
Vent (km/h)	65	65	65	100	85	70	70	35	35	20	15	15	15	25	40	35	45	25	30	55	65	75	80	80	75	60	45	30
à 2000m																												
Vent (km/h)	40	30	35	85	70	50	45	15	15	20	25	10	10	20	30	35	35	10	10	25	35	45	60	60	50	40	30	20
à 1500m																												

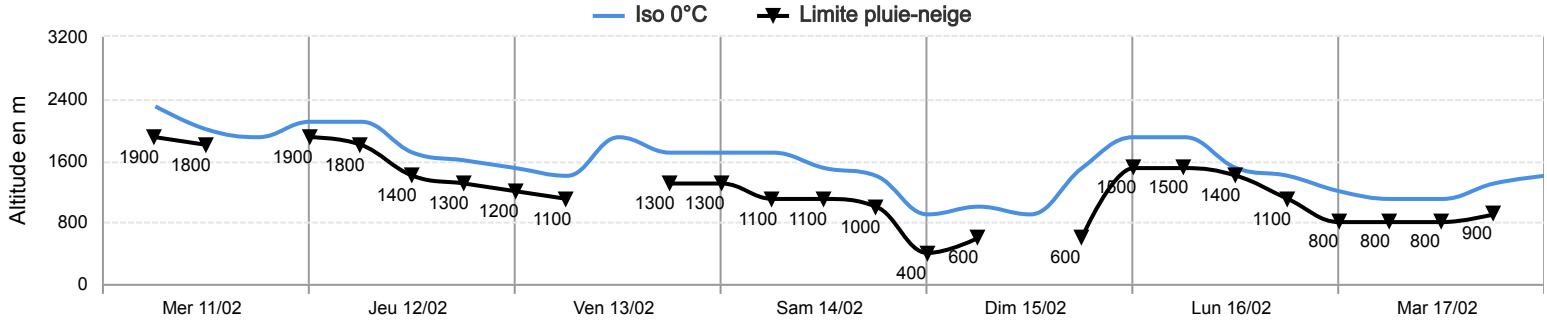

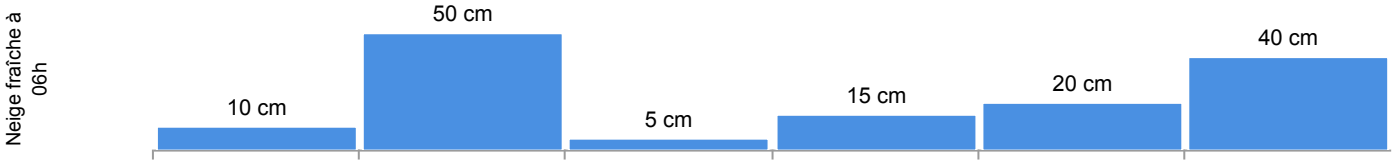

Risque d'avalanche	mer. 11/02	jeu. 12/02	ven. 13/02	sam. 14/02	dim. 15/02	lun. 16/02	mar. 17/02
	3	3	3	3	3	3	3

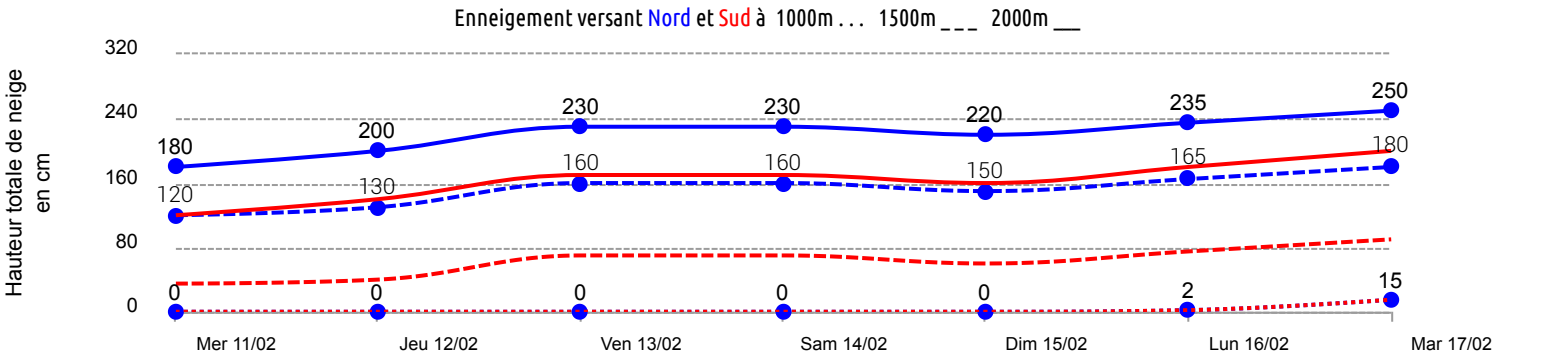

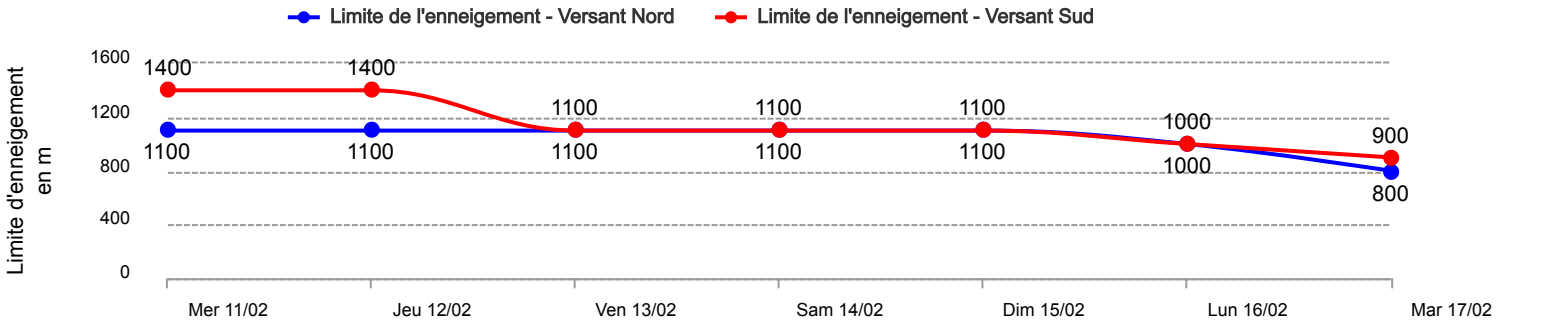

Pour consulter la vigilance en cours, veuillez vous rendre sur le site https://vigilance.meteofrance.fr/fr

Météo-France - 73 avenue de Paris, 94165 Saint-Mandé cedex - Contact : contact@meteo.fr

Bulletin neige & avalanches par téléphone au 0 892 68 10 20 Service 0,35 € / min + prix appel

Rédigé par Météo-France avec la contribution des observateurs du réseau nivo-météorologiques. Partenariat : ANMSM (Maires de Stations de Montagne), DSF (Domaines Skiables de France), ADSP (Directeurs de Pistes et de la Sécurité des Stations de Sports d'Hiver) et autres acteurs de la montagne.